Bulletin d'estimation du risque d'avalanche
(valable en dehors des pistes balisées et ouvertes)
MASSIF : Luchonnais

Rédigé le mardi 21 avril 2026 à 16h

Estimation des risques pour le : MERCREDI 22 AVRIL

ABSENCE DE REGEL, ACTIVITÉ DÈS LE MATIN, AUGMENTANT EN JOURNÉE

3

2 → 3

N O E S

Pas de regel

Indice de risque limité évoluant en marqué.

Départs spontanés : En negie humide, grandes à très grandes rares mais possibles

Déclenchements provoqués : En neige humide sous les skis

Indices de risque : 5 très fort - 4 fort - 3 marqué - 2 limité - 1 faible -- En noir : les pentes les plus dangereuses

Stabilité du manteau neigeux

Situation avalancheuse typique : neige humide — avalanches de fond

Départs spontanés :
En l'absence de regel après une nuit nuageuse et ventée de sud, des départs ponctuels de taille petite à moyenne sont déjà attendus le matin et deviennent nombreux au cours de la journée. Des avalanches de fond sont aussi possibles, partant en général d'une des nombreuses fissures déjà ouvertes. Elles restent rares, mais peuvent atteindre une grande voire très grande taille, les fissures ouvertes dépassant le mètre d'épaisseur, en particulier en expositions nord-ouest à nord-est. Dans les autres expositions, les accumulations sont moindres et le manteau est plus tassé, moins instable.
Ces avalanches de fond peuvent parcourir des dénivelés importants et atteindre des sentiers à des altitudes inférieures à la limite d'enneigement dans les couloirs d'avalanche habituels.

Déclenchements provoqués : en neige humide
Au passage d'un skieur ou randonneur, déclenchement aisé de neige très humide à gorgée d'eau, plutôt des coulées en versant nord, petites avalanches à très rarement moyennes en sud sur le haut du massif.

Autres : corniches et ponts de neige encore en place extrêmement peu résistants, pouvant céder dès le matin sous le poids d'une seule personne.

Qualité de la neige

Enneigement : plutôt bon pour la saison et débutant encore vers 1700m en nord, 2000m en sud.
Les limites de cet enneigement remontent progressivement dans la douceur ambiante, sous les éclaircies matinales et les quelques averses de l'après-midi.
État de la neige : Manteau neigeux humidifié sur toute son épaisseur dès le matin, avec des enfoncements importants en expositions nord, un peu moindre en versants ensoleillés et sur la neige ocre déjà bien tassée.

Aperçu météo pour le mercredi 22 avril

	nuit	matin	après-midi	soir
	Très nuageux en début de journée, matinée, ensoleillée, puis développement de nuages donnant des averses localement orageuses			
Pluie-Neige				
Iso 0 °C	3 500 m	3 300 m	3 300 m	3 400 m
Vent 2000 m	↑ 35 km/h	↑ 25 km/h	↓ 20 km/h	↑ 10 km/h
Vent 3000 m	→ 35 km/h	→ 40 km/h	↗ 25 km/h	↗ 30 km/h

Épaisseur de neige hors-piste

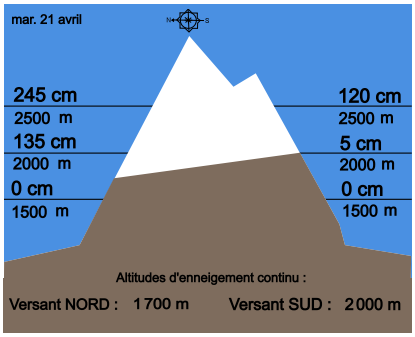

Précipitations à 1800 m

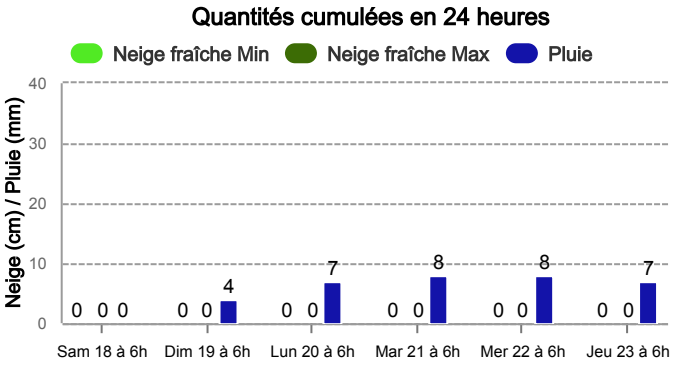

Tendance du jeudi 23 avril

3

Indice de risque marqué

Regel à peine meilleur, problème persistant d'avalanches de fond

Pour consulter la vigilance en cours, veuillez vous rendre sur le site https://vigilance.meteofrance.fr/fr

Météo-France - 73 avenue de Paris, 94165 Saint-Mandé cedex - Contact : contact@meteo.fr

Rédigé par Météo-France avec la contribution des observateurs du réseau nivo-météorologiques. Partenariat : ANMSM (Maires de Stations de Montagne), DSF (Domaines Skiables de France), ADSP (Directeurs de Pistes et de la Sécurité des Stations de Sports d'Hiver) et autres acteurs de la montagne.

Bulletin neige & avalanches par téléphone au 0 892 68 10 20 Service 0,35 € / min + prix appel

RÉPUBLIQUE FRANÇAISE
Liberté Égalité Fraternité

METEO FRANCE
À VOS CÔTÉS, DANS UN CLIMAT QUI CHANGE

Bulletin d'estimation du risque d'avalanche

(valable en dehors des pistes balisées et ouvertes)

MASSIF : Luchonnais

Rédigé le mardi 21 avril 2026 à 16h

Conditions nivo-météo des 7 derniers jours

	mer. 15/04				jeu. 16/04				ven. 17/04				sam. 18/04				dim. 19/04				lun. 20/04				mar. 21/04			
	03h	09h	15h	21h	03h	09h	15h	21h	03h	09h	15h	21h	03h	09h	15h	21h	03h	09h	15h	21h	03h	09h	15h	21h	03h	09h	15h	21h
Météo																												
Vent (km/h)	45	20	25	30	20	15	15	20	20	15	10	10	10	10	25	20	20	20	30	25	25	20	55	25	20	25	30	45
à 3000m																												
Vent (km/h)	5	10	15	5	5	5	5	5	5	5	5	5	5	5	15	10	15	15	20	10	5	10	15	5	5	10	10	15
à 2000m																												

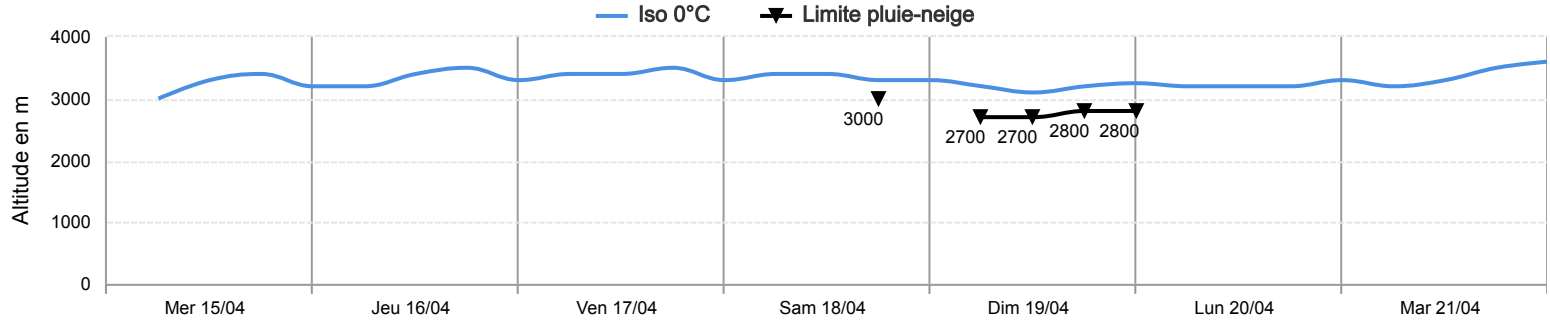

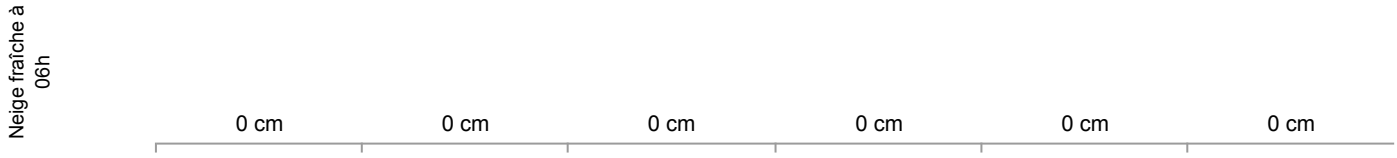

Risque d'avalanche	mer. 15/04	jeu. 16/04	ven. 17/04	sam. 18/04	dim. 19/04	lun. 20/04	mar. 21/04
	2	2	2	2	2	2	2

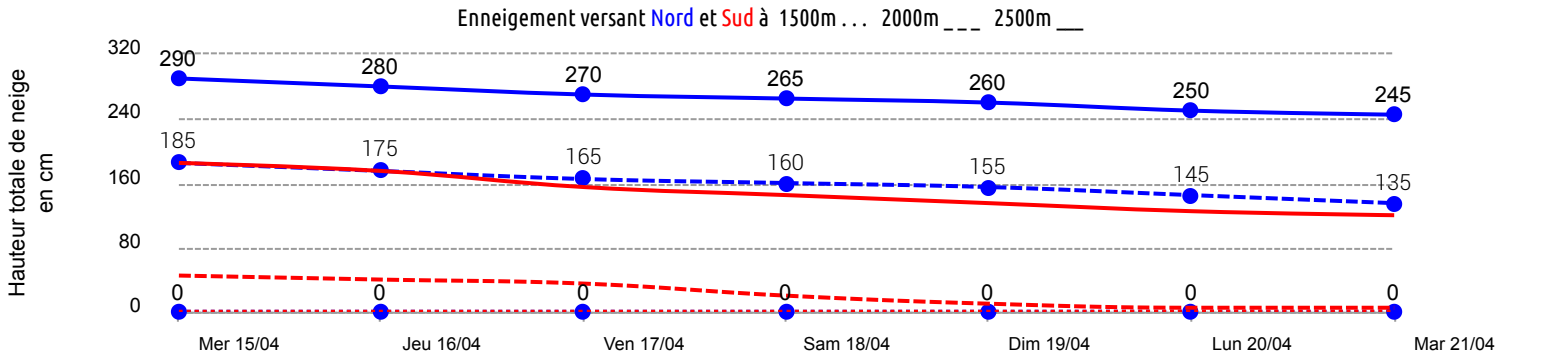

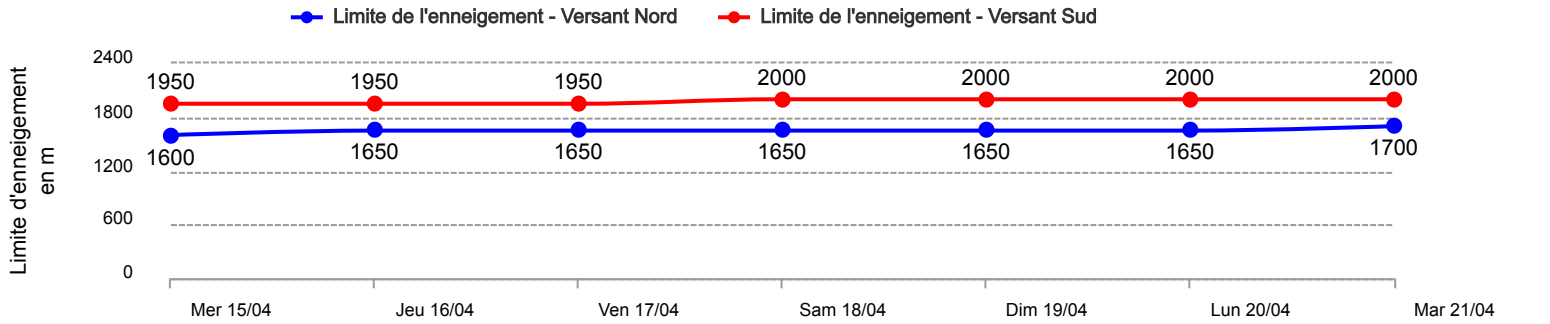

Pour consulter la vigilance en cours, veuillez vous rendre sur le site https://vigilance.meteofrance.fr/fr

Météo-France - 73 avenue de Paris, 94165 Saint-Mandé cedex - Contact : contact@meteo.fr

Bulletin neige & avalanches par téléphone au

0 892 68 10 20 Service 0,35 € / min + prix appel

Rédigé par Météo-France avec la contribution des observateurs du réseau nivo-météorologiques. Partenariat : ANMSM (Maires de Stations de Montagne), DSF (Domaines Skiables de France), ADSP (Directeurs de Pistes et de la Sécurité des Stations de Sports d'Hiver) et autres acteurs de la montagne.