Bulletin d'estimation du risque d'avalanche
(valable en dehors des pistes balisées et ouvertes)

MASSIF : Pays-Basque

Rédigé le mardi 21 avril 2026 à 16h

Estimation des risques pour le : MERCREDI 22 AVRIL

HUMIDIFICATION EN PROFONDEUR.

2

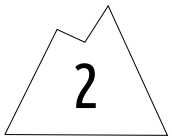

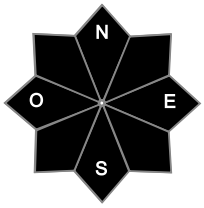

Indice de risque limité.

Départs spontanés : en neige humide, quelques avalanches de fond.

Déclenchements provoqués : en neige humide.

Indices de risque : 5 très fort - 4 fort - 3 marqué - 2 limité - 1 faible -- En noir : les pentes les plus dangereuses

Stabilité du manteau neigeux

Situation avalancheuse typique : neige humide avalanches de fond

Départs spontanés : manteau neigeux humidifié sur toute son épaisseur, **sans regel nocturne.**
Activité faible mais déjà possible en fin de nuit et début de matinée, puis, dans la douceur ambiante, sous le soleil du matin et sous les quelques averses de l'après-midi, manteau neigeux très humide à gorgé d'eau, favorable à des départs ponctuels de plus en plus nombreux en pentes raides encore enneigées, souvent de petite taille. Quelques avalanches de fond ou de glissement de taille moyenne encore possibles au plus doux et au plus humide de la journée, partant des quelques accumulations encore en place au plus haut du massif vers le secteur de la Pierre-Saint-Martin
Aucune orientation ne sera épargnée, départs à proximité des rochers, des zones déneigées et des nombreuses fissures ouvertes.

Déclenchements provoqués : en neige humide exclusivement.
Au passage d'**un skieur ou randonneur**, **déclenchement aisé** de **neige très humide à gorgée d'eau**, plutôt des **coulées en versant nord**, **petites avalanches à très rarement moyennes en sud** sur le haut du massif, dans le **secteur de la Pierre-Saint-Martin** essentiellement.

Autres : corniches et ponts de neige encore en place extrêmement peu résistants, pouvant céder dès le matin sous le poids d'une seule personne.

Qualité de la neige

Enneigement : plutôt bon pour la saison vers La Pierre-Saint-Martin, débutant vers 1650m en nord et 2000m en sud.
Les limites de cet enneigement remontent progressivement dans la douceur ambiante, sous les éclaircies matinales et les quelques averses de l'après-midi. Enneigement discontinu et faible en allant vers l'ouest (pic d'Orhy).
État de la neige : pas de regel nocturne, manteau neigeux humidifié sur toute son épaisseur, humide mais encore assez portant au petit matin, devenant très humide (en nord) à gorgé d'eau (en sud) et pourri au cours de la journée.

Aperçu météo pour le mercredi 22 avril

	nuit	matin	après-midi	soir
	Très nuageux en début de journée, matinée, ensoleillée, puis développement de nuages, rares averses possibles			
Pluie-Neige				
Iso 0 °C	3 500 m	3 300 m	3 300 m	3 400 m
Vent 1000 m	↑ 40 km/h	↗ 30 km/h	↓ 25 km/h	← 10 km/h
Vent 2000 m	↑ 70 km/h	↑ 50 km/h	↘ 25 km/h	↑ 20 km/h

Épaisseur de neige hors-piste

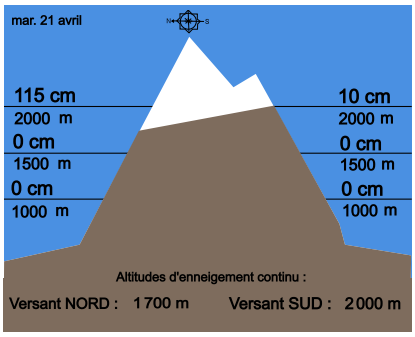

Précipitations à 1800 m

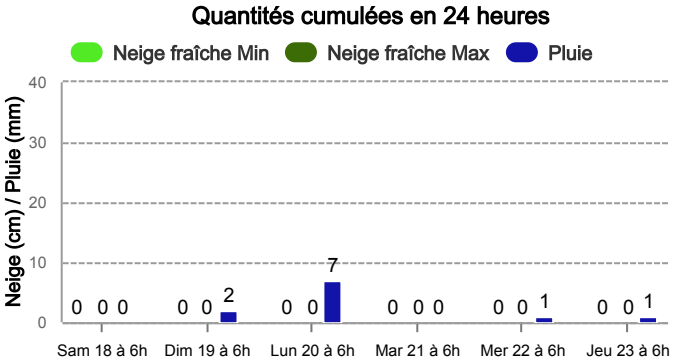

Tendance du jeudi 23 avril

2

Indice de risque limité

Peu d'évolution, douceur persistante

Pour consulter la vigilance en cours, veuillez vous rendre sur le site https://vigilance.meteofrance.fr/fr

Météo-France - 73 avenue de Paris, 94165 Saint-Mandé cedex - Contact : contact@meteo.fr

Rédigé par Météo-France avec la contribution des observateurs du réseau nivo-météorologiques. Partenariat : ANMSM (Maires de Stations de Montagne), DSF (Domaines Skiables de France), ADSP (Directeurs de Pistes et de la Sécurité des Stations de Sports d'Hiver) et autres acteurs de la montagne.

Bulletin neige & avalanches par téléphone au
0 892 68 10 20 Service 0,35 € / min + prix appel

RÉPUBLIQUE FRANÇAISE
Liberté Égalité Fraternité

METEO FRANCE
À VOS CÔTÉS, DANS UN CLIMAT QUI CHANGE

Bulletin d'estimation du risque d'avalanche

(valable en dehors des pistes balisées et ouvertes)

MASSIF : Pays-Basque

Rédigé le mardi 21 avril 2026 à 16h

Conditions nivo-météo des 7 derniers jours

	mer. 15/04				jeu. 16/04				ven. 17/04				sam. 18/04				dim. 19/04				lun. 20/04				mar. 21/04			
	03h	09h	15h	21h	03h	09h	15h	21h	03h	09h	15h	21h	03h	09h	15h	21h	03h	09h	15h	21h	03h	09h	15h	21h	03h	09h	15h	21h
Météo																												
Vent (km/h)	35	35	35	25	15	15	15	10	10	10	10	10	20	15	15	20	25	25	25	30	30	25	35	30	25	30	35	55
à 2000m																												
Vent (km/h)	10	15	15	10	5	5	5	5	5	5	5	5	5	10	10	10	10	15	15	15	5	5	15	10	10	10	10	15
à 1000m																												

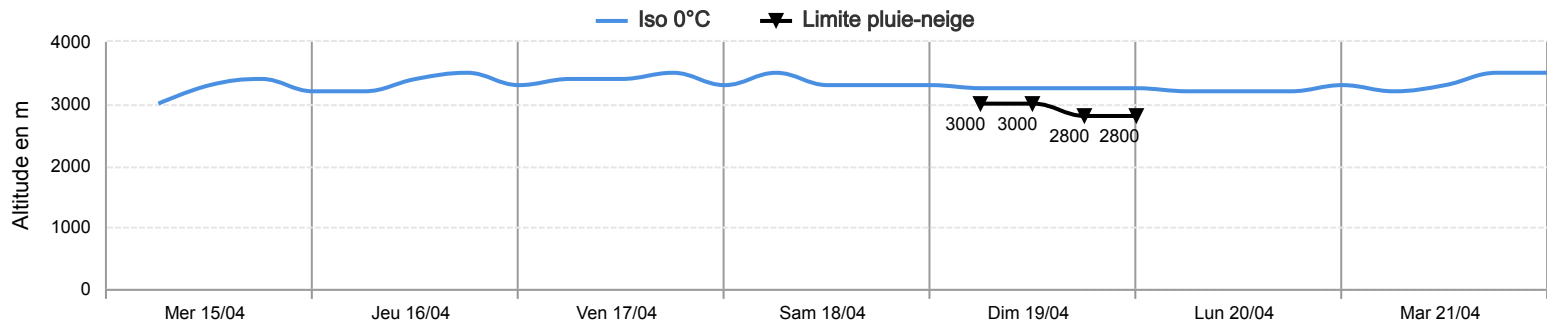

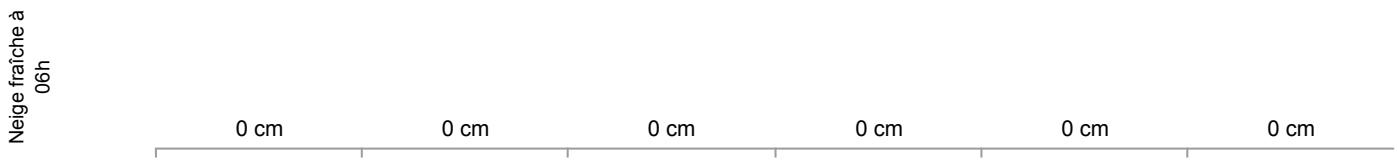

Risque d'avalanche	mer. 15/04	jeu. 16/04	ven. 17/04	sam. 18/04	dim. 19/04	lun. 20/04	mar. 21/04
	2	2	2	2	2	2	2

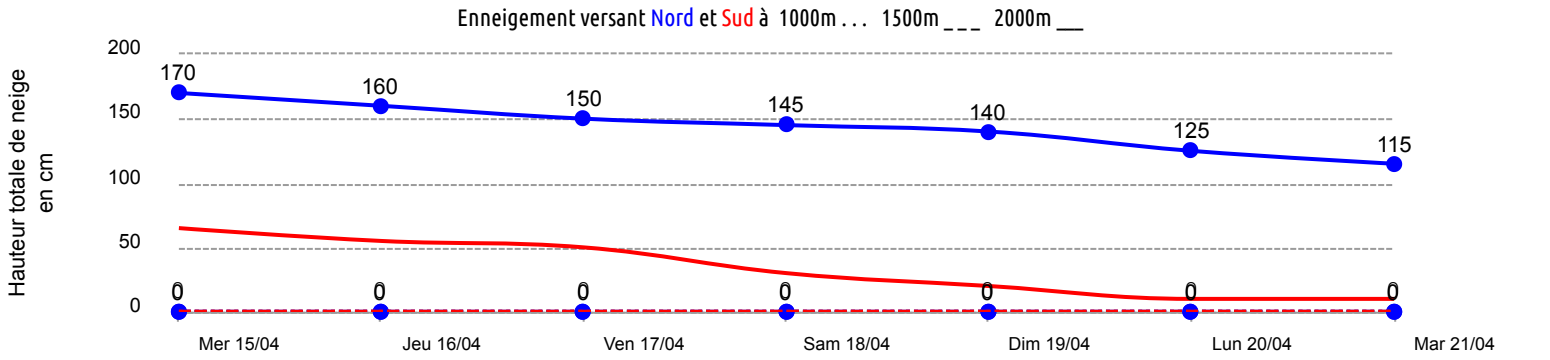

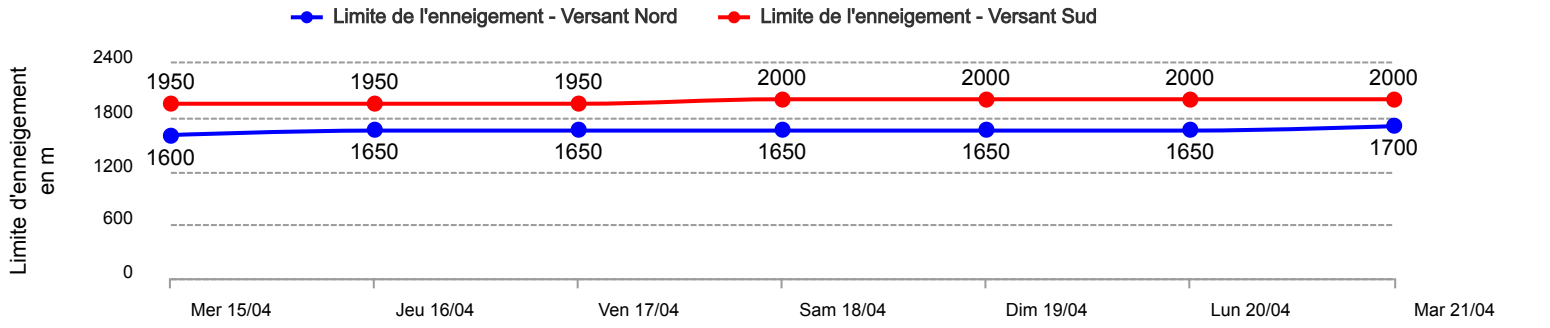

Pour consulter la vigilance en cours, veuillez vous rendre sur le site https://vigilance.meteofrance.fr/fr

Météo-France - 73 avenue de Paris, 94165 Saint-Mandé cedex - Contact : contact@meteo.fr

Rédigé par Météo-France avec la contribution des observateurs du réseau nivo-météorologiques. Partenariat : ANMSM (Maires de Stations de Montagne), DSF (Domaines Skiables de France), ADSP (Directeurs de Pistes et de la Sécurité des Stations de Sports d'Hiver) et autres acteurs de la montagne.

Bulletin neige & avalanches par téléphone au
0 892 68 10 20 Service 0,35 € / min + prix appel