Bulletin d'estimation du risque d'avalanche

(valable en dehors des pistes balisées et ouvertes)

MASSIF : Renoso Incudine

Rédigé le mardi 21 avril 2026 à 16h

Estimation des risques pour le : MERCREDI 22 AVRIL

MANTEAU NEIGEUX PRINTANIER

1

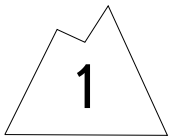

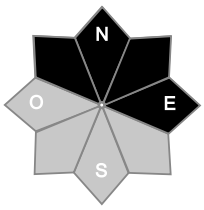

Indice de risque faible.

Départs spontanés : Coulées de neige humide en journée dans les pentes raides

Déclenchements provoqués : Peu probables

Indices de risque : 5 très fort - 4 fort - 3 marqué - 2 limité - 1 faible -- En noir : les pentes les plus dangereuses

Stabilité du manteau neigeux

Situation avalancheuse typique : neige humide

Départs spontanés : Le manteau neigeux est bien humidifié et bien tassé. En journée, sous l'effet de la douceur, de rares coulées ou petites avalanches de neige humide sont attendues dans les pentes raides. À noter également qu'une avalanche de fond n'est pas exclue sur les dalles rocheuses pouvant être de taille moyenne l'après midi.
Déclenchements provoqués : Dans la plupart des secteurs, il est difficile de provoquer une avalanche dans ce manteau. Un skieur peut éventuellement favoriser un départ ponctuel en coupant une pente raide en neige très humide.
Autres : Prendre garde également aux effondrements de corniches et ponts de neige qui peuvent céder.

Qualité de la neige

Qualification de l'enneigement : L'enneigement est encore très bon pour la saison. À Ghisoni, on relève près de 1,5 à 2 m de neige vers 1800 à 1900 m d'altitude.
Limite d'enneigement skiable : Limite d'enneigement skiable : vers 1600 à 1700 m en Nord, 1800 à 1900 m en Sud mais cette limite progresse chaque jour avec la fonte.
État de la neige : Absence de regel mais neige portant le matin au plus haut du massif en expositions nord. Neige dense en sud au lever du jour mais généralement non croûtée, devenant vite printanière, très humide. La surface du manteau est majoritairement constituée de neige colorée, chargée en poussières sahariennes. Les cols et crêtes ouest se dégarnissent en neige ou sont parfois "pelés". Nombreuses fissures en place.

Aperçu météo pour le mercredi 22 avril

	nuit	matin	après-midi	soir
Pluie-Neige		2 500 m		
Iso 0 °C	3 300 m	3 100 m	3 000 m	2 900 m
Vent 1500 m	15 km/h	20 km/h	20 km/h	15 km/h
Vent 2000 m	40 km/h	25 km/h	25 km/h	20 km/h

Épaisseur de neige hors-piste

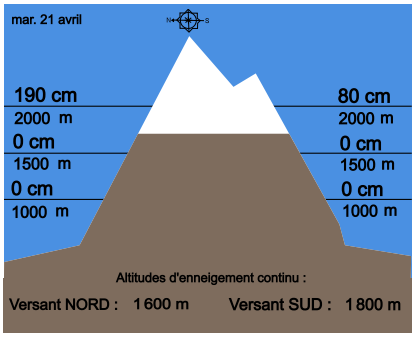

Précipitations à 1800 m

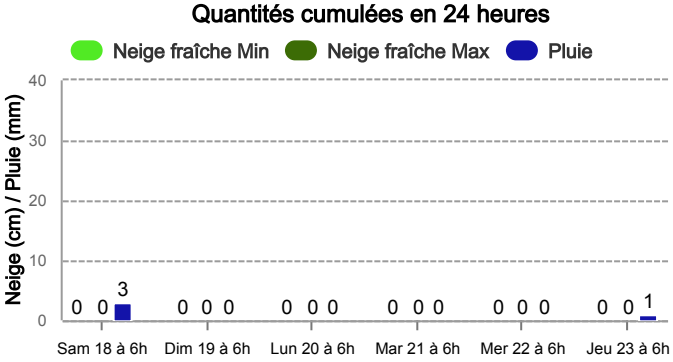

Tendance du jeudi 23 avril

1

Indice de risque faible

Pas d'évolution notable en termes de risque.

Pour consulter la vigilance en cours, veuillez vous rendre sur le site https://vigilance.meteofrance.fr/fr

Météo-France - 73 avenue de Paris, 94165 Saint-Mandé cedex - Contact : contact@meteo.fr

Rédigé par Météo-France avec la contribution des observateurs du réseau nivo-météorologiques. Partenariat : ANMSM (Maires de Stations de Montagne), DSF (Domaines Skiables de France), ADSP (Directeurs de Pistes et de la Sécurité des Stations de Sports d'Hiver) et autres acteurs de la montagne.

Bulletin neige & avalanches par téléphone au

0 892 68 10 20 Service 0,35 € / min + prix appel

RÉPUBLIQUE FRANÇAISE
Liberté Égalité Fraternité

METEO FRANCE
À VOS CÔTÉS, DANS UN CLIMAT QUI CHANGE

Bulletin d'estimation du risque d'avalanche

(valable en dehors des pistes balisées et ouvertes)

MASSIF : Renoso Incudine

Rédigé le mardi 21 avril 2026 à 16h

Conditions nivo-météo des 7 derniers jours

	mer. 15/04				jeu. 16/04				ven. 17/04				sam. 18/04				dim. 19/04				lun. 20/04				mar. 21/04			
	03h	09h	15h	21h	03h	09h	15h	21h	03h	09h	15h	21h	03h	09h	15h	21h	03h	09h	15h	21h	03h	09h	15h	21h	03h	09h	15h	21h
Météo																												
Vent (km/h)	30	30	35	30	20	20	15	30	20	15	15	20	15	20	15	15	10	15	30	25	35	40	55	60	45	40	40	30
à 2000m																												
Vent (km/h)	30	30	30	25	20	15	10	25	20	15	10	15	10	15	10	5	10	20	35	25	25	35	40	45	30	30	30	15
à 1500m																												

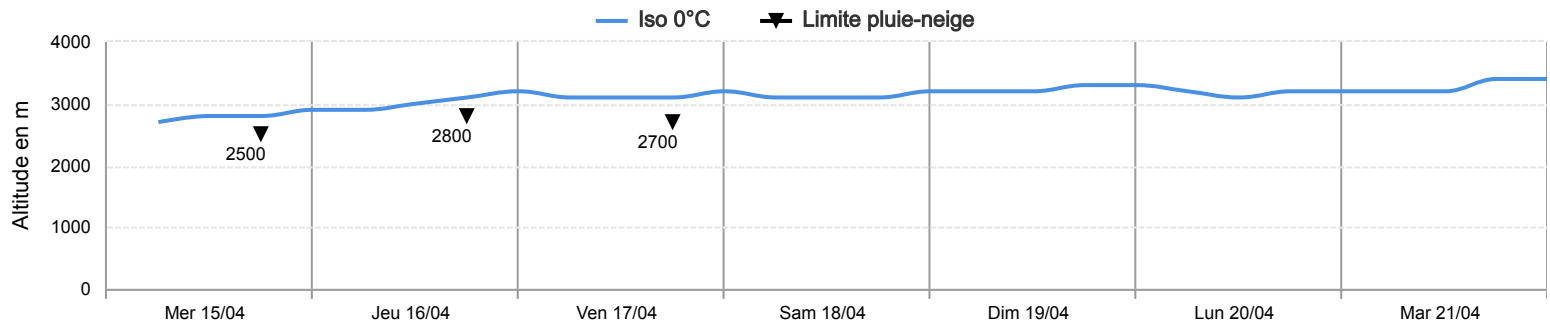

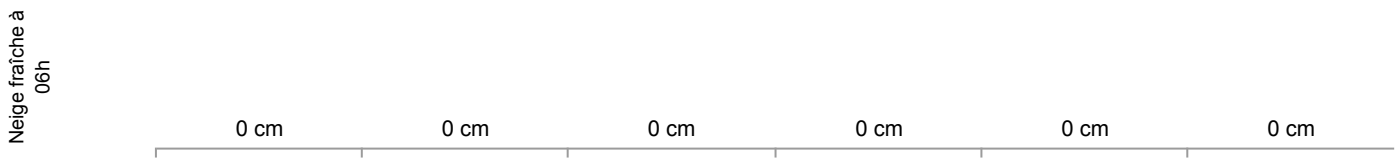

Risque d'avalanche	mer. 15/04	jeu. 16/04	ven. 17/04	sam. 18/04	dim. 19/04	lun. 20/04	mar. 21/04
	3	2	2	1	1	1	2

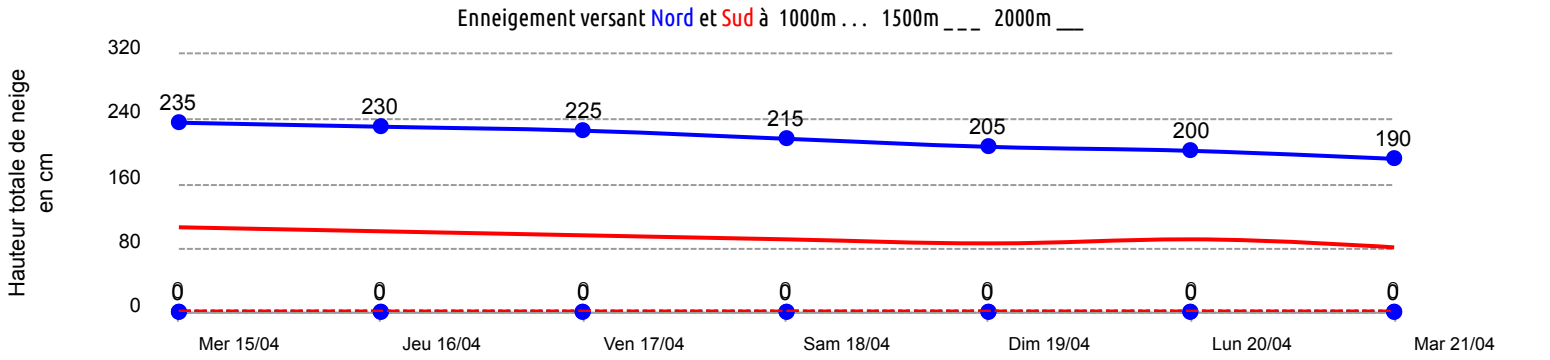

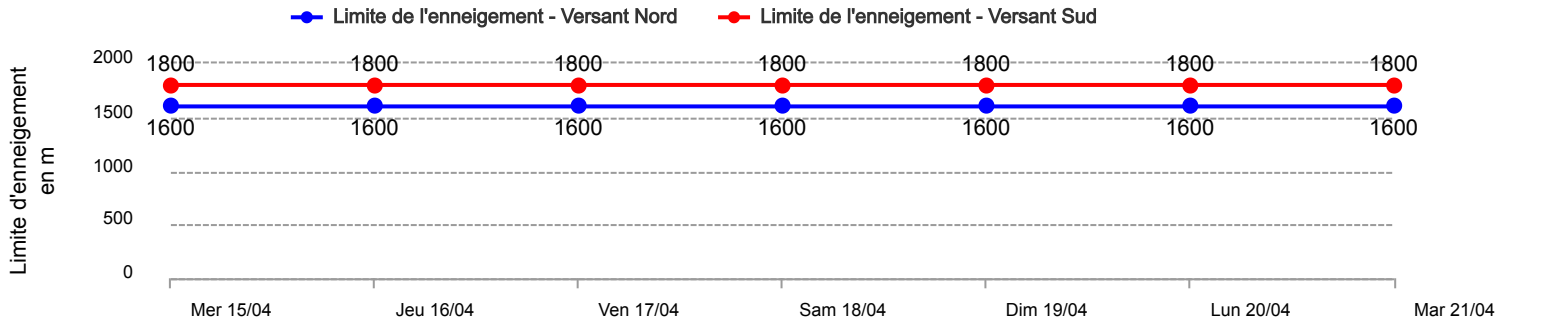

Pour consulter la vigilance en cours, veuillez vous rendre sur le site https://vigilance.meteofrance.fr/fr

Météo-France - 73 avenue de Paris, 94165 Saint-Mandé cedex - Contact : contact@meteo.fr

Rédigé par Météo-France avec la contribution des observateurs du réseau nivo-météorologiques. Partenariat : ANMSM (Maires de Stations de Montagne), DSF (Domaines Skiables de France), ADSP (Directeurs de Pistes et de la Sécurité des Stations de Sports d'Hiver) et autres acteurs de la montagne.

Bulletin neige & avalanches par téléphone au
0 892 68 10 20 Service 0,35 € / min + prix appel