RÉPUBLIQUE FRANÇAISE
Liberté Égalité Fraternité

METEO FRANCE
À VOS CÔTÉS, DANS UN CLIMAT QUI CHANGE

Bulletin d'estimation du risque d'avalanche
(valable en dehors des pistes balisées et ouvertes)

MASSIF : Thabor

Rédigé le mardi 21 avril 2026 à 16h

Estimation des risques pour le : MERCREDI 22 AVRIL

MANTEAU NEIGEUX BIEN STABILISÉ, ACTIVITÉ EN NEIGE HUMIDE EN NETTE ATTÉNUATION AVEC LE CIEL NUAGEUX

1

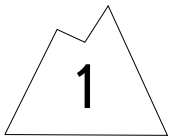

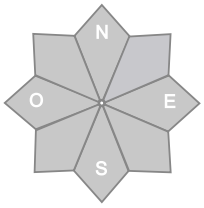

Indice de risque faible.

Départs spontanés : peu probables

Déclenchements provoqués : peu probables

Indices de risque : 5 très fort - 4 fort - 3 marqué - 2 limité - 1 faible -- En noir : les pentes les plus dangereuses

Stabilité du manteau neigeux

Situation avalancheuse typique : pas de situation prédominante

Déclenchements provoqués : le manteau neigeux est ancien, très dense et bien stabilisé. On ne peut exclure de déclenchements de neige humide sous les éclaircies par des skieurs en versants nord d'altitude supérieure à 2400 m, cependant le voile nuageux épais et le léger rafraîchissement de la masse d'air limitent fortement l'activité par rapport aux jours précédents.

Départs spontanés : peu probables. Le bon regel nocturne puis la couverture nuageuse limitent l'humidification du manteau neigeux par rapport aux jours précédents.

Qualité de la neige

Enneigement déficitaire sur le massif, particulièrement en adrets.
Hauteurs de neige observées vers 2500 m : 114 cm dans le vallon du Chardonnet, 80 cm aux Rochilles

Limite d'enneigement skiable : très localement vers 1800 m en terrain favorable, 2300/2400 m en adrets.

État de la neige de surface : manteau neigeux printanier, voire de névé en toute orientation sous 2300/2400 m environ et en adrets d'altitude. Bon regel nocturne, humidification limitée en journée en raison de la couverture nuageuse.

Aperçu météo pour le mercredi 22 avril

	nuit	matin	après-midi	soir
	Nuageux à couvert après une nuit dégagée et un bon regel nocturne.			
Pluie-Neige				
Iso 0 °C	2 800 m	2 700 m	2 600 m	2 700 m
Vent 2000 m	15 km/h	20 km/h	25 km/h	10 km/h
Vent 3000 m	30 km/h	25 km/h	25 km/h	20 km/h

Épaisseur de neige hors-piste

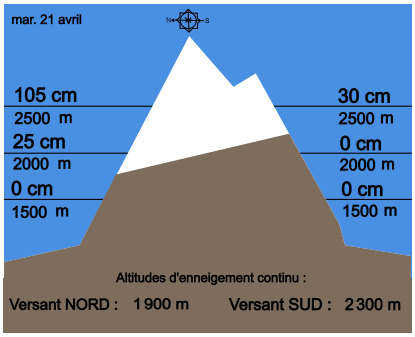

Précipitations à 1800 m

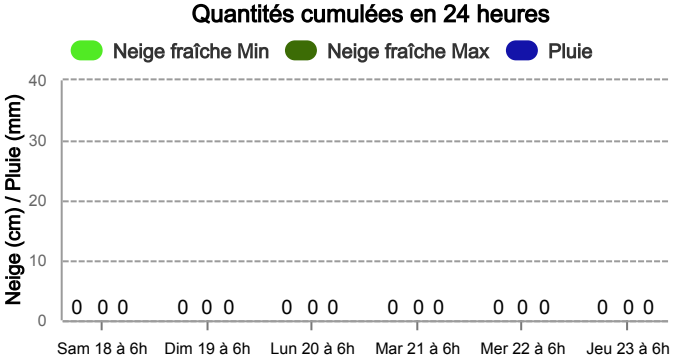

Tendance du jeudi 23 avril

1

Indice de risque faible

Peu d'évolution de la situation nivologique. Bon regel nocturne, ensoleillé en journée, masse d'air moins chaud que les jours précédents. Risque faible

Pour consulter la vigilance en cours, veuillez vous rendre sur le site https://vigilance.meteofrance.fr/fr

Météo-France - 73 avenue de Paris, 94165 Saint-Mandé cedex - Contact : contact@meteo.fr

Rédigé par Météo-France avec la contribution des observateurs du réseau nivo-météorologiques. Partenariat : ANMSM (Maires de Stations de Montagne), DSF (Domaines Skiables de France), ADSP (Directeurs de Pistes et de la Sécurité des Stations de Sports d'Hiver) et autres acteurs de la montagne.

Bulletin neige & avalanches par téléphone au
0 892 68 10 20 Service 0,35 € / min + prix appel

RÉPUBLIQUE FRANÇAISE
Liberté Égalité Fraternité

METEO FRANCE
À VOS CÔTÉS, DANS UN CLIMAT QUI CHANGE

Bulletin d'estimation du risque d'avalanche

(valable en dehors des pistes balisées et ouvertes)

MASSIF : Thabor

Rédigé le mardi 21 avril 2026 à 16h

Conditions nivo-météo des 7 derniers jours

	mer. 15/04				jeu. 16/04				ven. 17/04				sam. 18/04				dim. 19/04				lun. 20/04				mar. 21/04			
	03h	09h	15h	21h	03h	09h	15h	21h	03h	09h	15h	21h	03h	09h	15h	21h	03h	09h	15h	21h	03h	09h	15h	21h	03h	09h	15h	21h
Météo																												
Vent (km/h)	15	15	15	15	15	15	10	5	5	5	5	10	15	15	15	15	20	25	30	20	25	25	30	25	25	25	30	25
à 3000m																												
Vent (km/h)	10	15	15	10	10	10	10	5	5	5	10	5	5	5	10	10	15	25	30	15	15	20	30	15	15	20	25	15
à 2000m																												

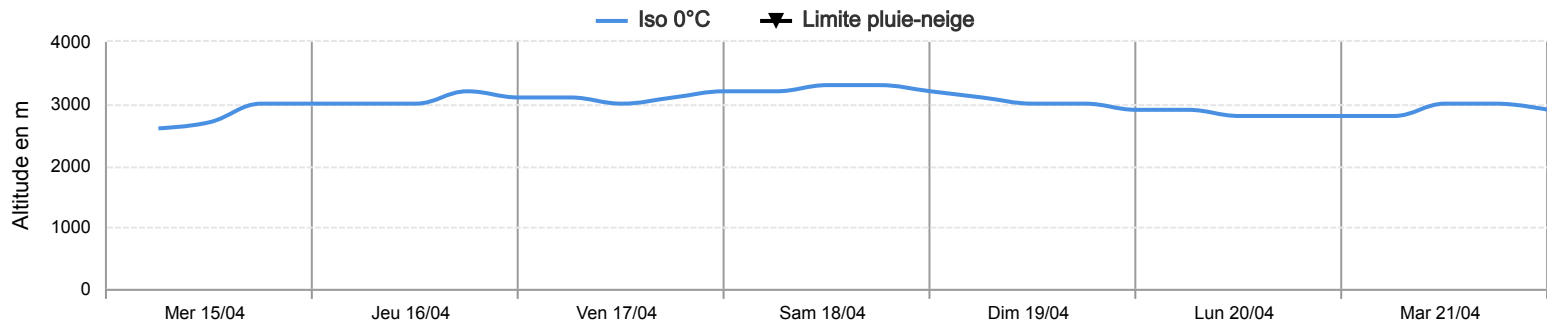

Neige fraîche à 06h

mer. 15/04	jeu. 16/04	ven. 17/04	sam. 18/04	dim. 19/04	lun. 20/04
0 cm	0 cm	0 cm	0 cm	0 cm	0 cm

Risque d'avalanche	mer. 15/04	jeu. 16/04	ven. 17/04	sam. 18/04	dim. 19/04	lun. 20/04	mar. 21/04
	2	2	2	2	2	2	2

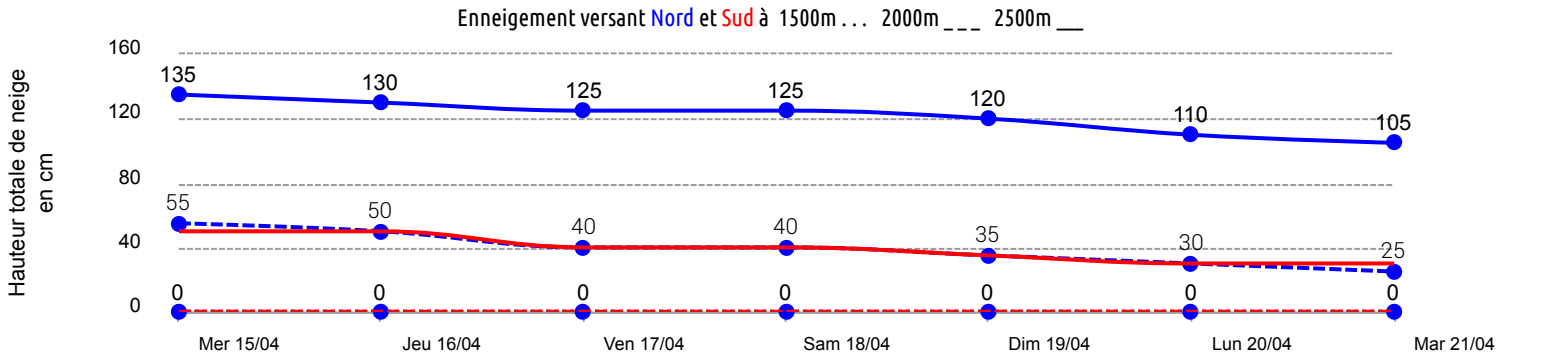

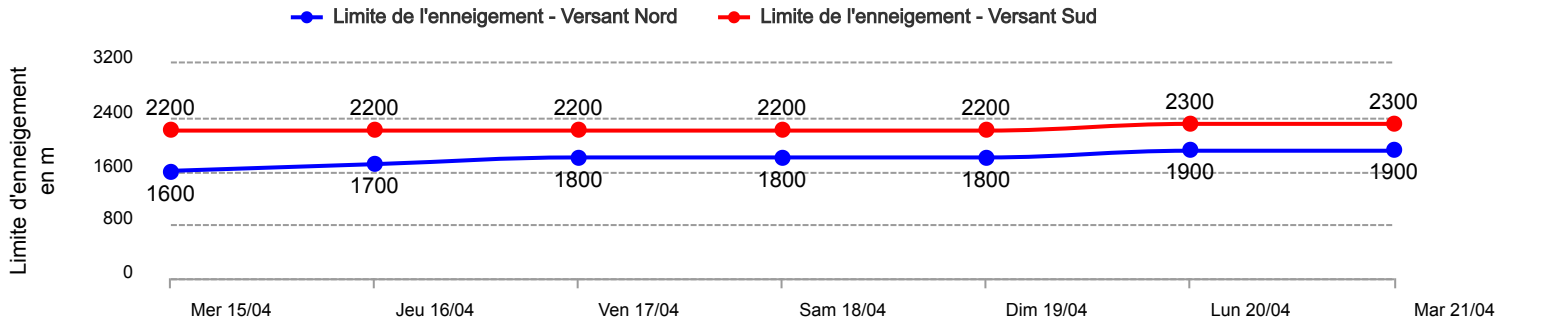

Pour consulter la vigilance en cours, veuillez vous rendre sur le site https://vigilance.meteofrance.fr/fr

Météo-France - 73 avenue de Paris, 94165 Saint-Mandé cedex - Contact : contact@meteo.fr

Rédigé par Météo-France avec la contribution des observateurs du réseau nivo-météorologiques. Partenariat : ANMSM (Maires de Stations de Montagne), DSF (Domaines Skiables de France), ADSP (Directeurs de Pistes et de la Sécurité des Stations de Sports d'Hiver) et autres acteurs de la montagne.

Bulletin neige & avalanches par téléphone au

0 892 68 10 20 Service 0,35 € / min + prix appel