Bulletin d'estimation du risque d'avalanche
(valable en dehors des pistes balisées et ouvertes)

MASSIF : Ubaye

Rédigé le mardi 21 avril 2026 à 16h

Estimation des risques pour le : MERCREDI 22 AVRIL

MANTEAU NEIGEUX PRINTANIER - UN PEU D'ACTIVITÉ EN NEIGE HUMIDE

2

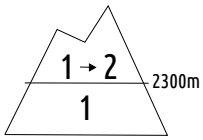

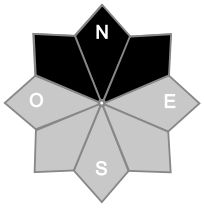

Au-dessus de 2300m indice de risque faible évoluant en limité, plus bas indice faible.

Départs spontanés : avalanches en neige humide. Peu fréquent, mais possiblement volumineuse en ubacs d'altitude.

Déclenchements provoqués : en neige humide sous les skis.

Indices de risque : 5 très fort - 4 fort - 3 marqué - 2 limité - 1 faible -- En noir : les pentes les plus dangereuses

Stabilité du manteau neigeux

Situation avalancheuse typique : neige humide

Départs spontanés : avalanches en neige humide en pentes raides, généralement superficielles de petite taille. Toutefois un départ linéaire plus volumineux de taille moyenne, grande non exclue, reste possible dans les pentes nord-ouest à nord-est au-dessus de 2300/2400 m environ, emportant la totalité du manteau neigeux en place. Peu probables en début de journée après un regel nocturne plutôt bon, puis risque en augmentation avec le réchauffement par le soleil matinal, mais aussi les nuages et les quelques averses l'après-midi, pluvieuses sous 2500 m environ.

Déclenchements provoqués : un skieur coupant une pente raide trop tardivement peut initier un départ de neige humide sous ses skis. À noter également que dans les ubacs d'altitude supérieure à 2300/2400 m, une première avalanche superficielle de neige humide déclenchée par un skieur peut dans de très rares cas provoquer un second départ linéaire plus volumineux.

Qualité de la neige

Enneigement très déficitaire pour la période, avec une fonte qui se poursuit à un rythme élevé. Absence de précipitations significatives depuis plus d'1 mois et grande douceur en place depuis début avril.
Hauteurs de neige observées : plus que 23 cm à la nivose de Restefond à 2550 m. Il s'agit de la 2e valeur la plus faible pour un 20 avril en 31 ans de mesures.

Enneigement skiable généralement à partir de 1900/2000 m en ubacs sur terrain favorable, mais plus de 2500 m en sud.

État de la neige en surface : manteau neigeux printanier, croûté le matin, puis s'humidifiant rapidement en journée. Manteau neigeux pas totalement transformé en ubac au dessus de 2300/2400 m. L'après-midi, localement un peu de neige fraiche au-dessus de 2500 m environ avec les averses.

Aperçu météo pour le mercredi 22 avril

	nuit	matin	après-midi	soir

Nebbia secteur frontalier. Ciel s'ennuageant plus franchement dès la mi-journée. Quelques averses l'après-midi. Encore doux. Vent d'ouest sensible sur les crêtes.

Pluie-Neige			2 500 m	2 400 m
Iso 0 °C	2 900 m	2 800 m	2 800 m	2 600 m
Vent 2000 m	→ 15 km/h	→ 25 km/h	→ 30 km/h	← 15 km/h
Vent 3000 m	→ 35 km/h	→ 35 km/h	→ 40 km/h	→ 20 km/h

Épaisseur de neige hors-piste

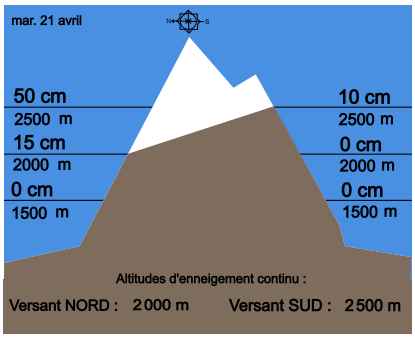

Précipitations à 1800 m

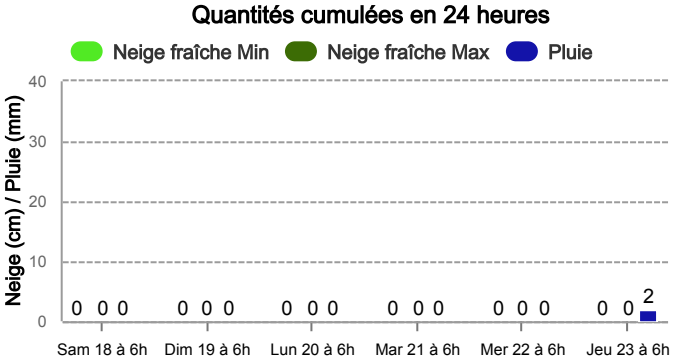

Tendance du jeudi 23 avril

2

Indice de risque limité

La situation nivologique reste similaire et pilotée par l'activité en neige humide au cours de la journée. Rares départs linéaires volumineux dans les ubacs d'altitude.

Pour consulter la vigilance en cours, veuillez vous rendre sur le site https://vigilance.meteofrance.fr/fr

Météo-France - 73 avenue de Paris, 94165 Saint-Mandé cedex - Contact : contact@meteo.fr

Rédigé par Météo-France avec la contribution des observateurs du réseau nivo-météorologiques. Partenariat : ANMSM (Maires de Stations de Montagne), DSF (Domaines Skiables de France), ADSP (Directeurs de Pistes et de la Sécurité des Stations de Sports d'Hiver) et autres acteurs de la montagne.

Bulletin neige & avalanches par téléphone au 0 892 68 10 20 Service 0,35 € / min + prix appel

RÉPUBLIQUE FRANÇAISE
Liberté Égalité Fraternité

METEO FRANCE
À VOS CÔTÉS, DANS UN CLIMAT QUI CHANGE

Bulletin d'estimation du risque d'avalanche

(valable en dehors des pistes balisées et ouvertes)

MASSIF : Ubaye

Rédigé le mardi 21 avril 2026 à 16h

Conditions nivo-météo des 7 derniers jours

	mer. 15/04				jeu. 16/04				ven. 17/04				sam. 18/04				dim. 19/04				lun. 20/04				mar. 21/04			
	03h	09h	15h	21h	03h	09h	15h	21h	03h	09h	15h	21h	03h	09h	15h	21h	03h	09h	15h	21h	03h	09h	15h	21h	03h	09h	15h	21h
Météo																												
Vent (km/h)	25	20	20	10	10	10	15	10	10	10	15	10	15	15	20	20	20	30	40	30	30	35	40	30	30	30	40	30
à 3000m	←	←	↖	↘	↘	↑	↗	↘	↗	↗	↗	↘	→	↗	→	↘	↘	→	→	→	→	→	→	→	→	→	→	→
Vent (km/h)	15	15	15	5	5	10	20	5	5	10	20	5	5	10	20	10	10	15	30	15	10	20	30	15	15	15	30	15
à 2000m	←	←	→	←	↓	←	→	↖	↖	↑	→	←	↖	↗	→	↘	↘	→	→	→	↘	↘	→	↘	→	↘	→	→

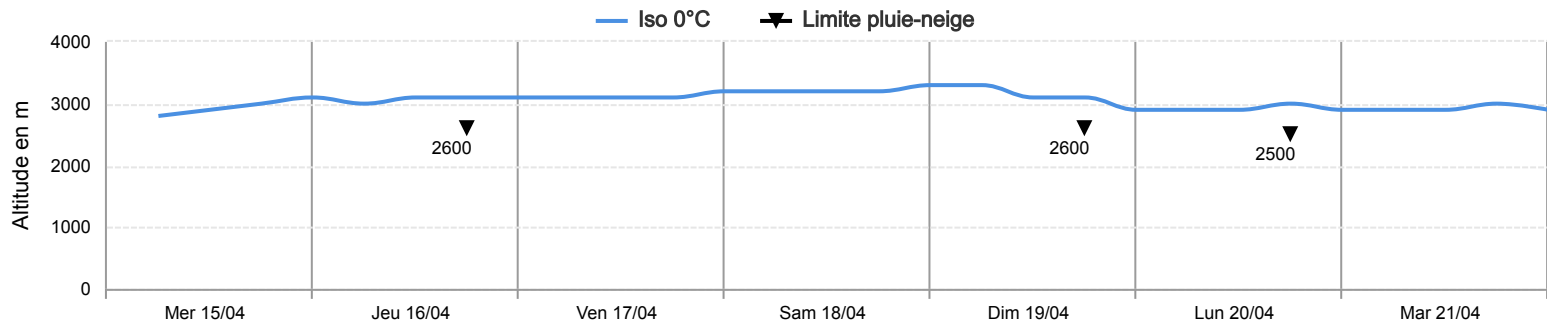

Neige fraîche à 06h

0 cm	0 cm	0 cm	0 cm	0 cm	0 cm

Risque d'avalanche	mer. 15/04	jeu. 16/04	ven. 17/04	sam. 18/04	dim. 19/04	lun. 20/04	mar. 21/04
	2	2	2	2	2	2	2

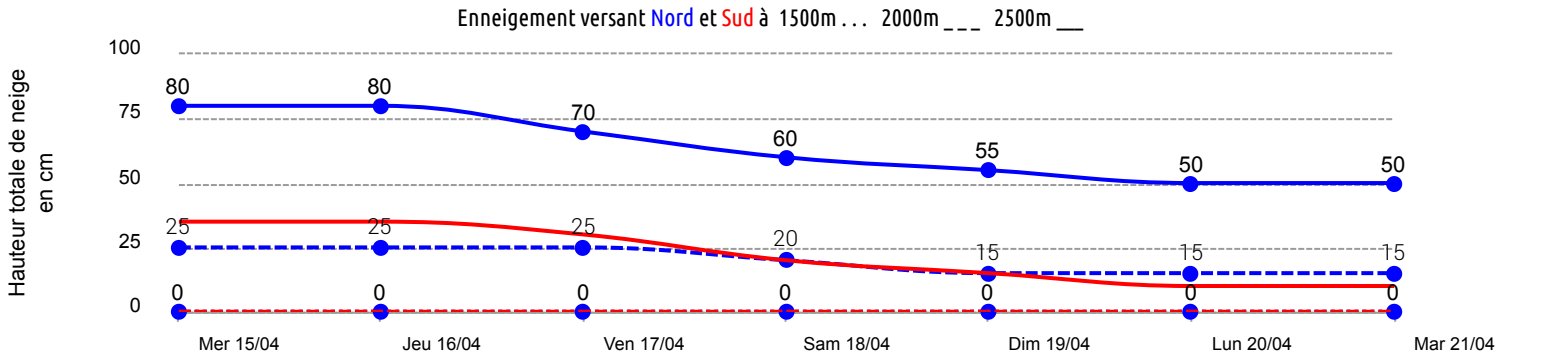

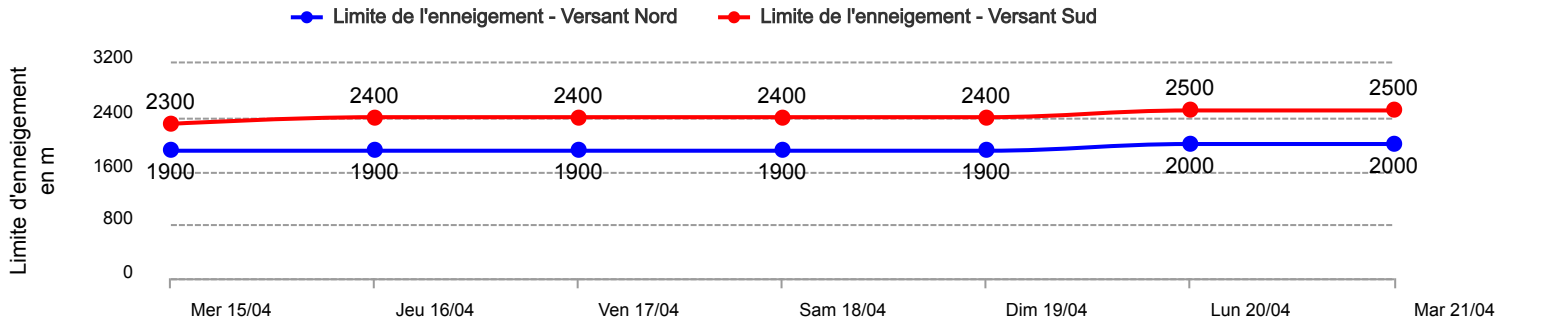

Pour consulter la vigilance en cours, veuillez vous rendre sur le site https://vigilance.meteofrance.fr/fr

Météo-France - 73 avenue de Paris, 94165 Saint-Mandé cedex - Contact : contact@meteo.fr

Bulletin neige & avalanches par téléphone au

0 892 68 10 20 Service 0,35 € / min + prix appel

Rédigé par Météo-France avec la contribution des observateurs du réseau nivo-météorologiques. Partenariat : ANMSM (Maires de Stations de Montagne), DSF (Domaines Skiables de France), ADSP (Directeurs de Pistes et de la Sécurité des Stations de Sports d'Hiver) et autres acteurs de la montagne.