GOBIERNO DE ESPAÑA
VICEPRESIDENCIA TERCERA DEL GOBIERNO
MINISTERIO PARA LA TRANSICIÓN ECOLÓGICA Y EL RETO DEMOGRÁFICO

Boletín de información nivológica y de peligro de aludes

Pirineo Navarro y Aragonés

aemet Agencia Estatal de Meteorología

miércoles, 22 de abril de 2026

Pronóstico hasta las 24 horas del jueves, día 23 de abril

(Válido fuera de pistas de esquí balizadas y abiertas)

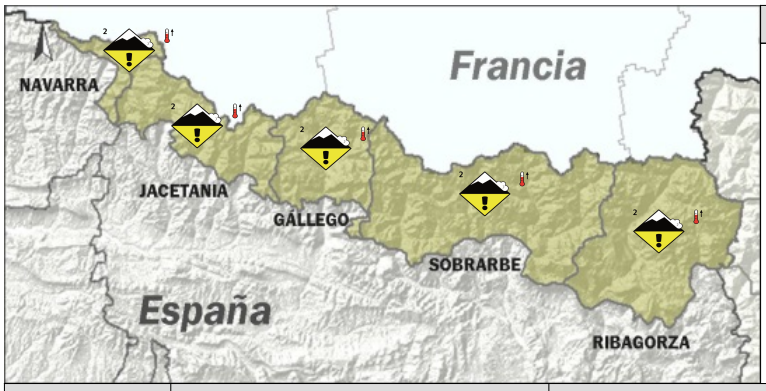

Problemas de aludes

Nieve húmeda

Deslizamientos basales

Macizo	Peligro	Problemas de aludes, cota, orientación, tamaño	Innivación observada (m)
Navarra	2 — 2 — Limitado	Nieve húmeda: 2 — N, O, E, S — 2 Deslizamientos basales: 2 — N, O, E, S — 2	2026-04-22 N / S Cota más baja caras N
Jacetania	2 — 2 — Limitado	Nieve húmeda: 2 — N, O, E, S — 2 Deslizamientos basales: 2 — N, O, E, S — 2	2026-04-22 N / S Cota más baja caras N
Gállego	2 — 2 — Limitado	Nieve húmeda: 2 — N, O, E, S — 2 Deslizamientos basales: 2 — N, O, E, S — 2	2026-04-22 N / S Cota más baja caras N

AEMET. Se autoriza la reproducción de su contenido citando la fuente.

Boletín de información nivológica y de peligro de aludes

Pirineo Navarro y Aragonés

Sobrarbe	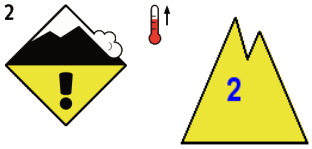 **Limitado**	**Nieve húmeda** 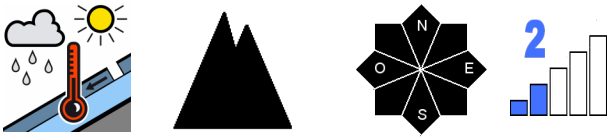 **Deslizamientos basales** 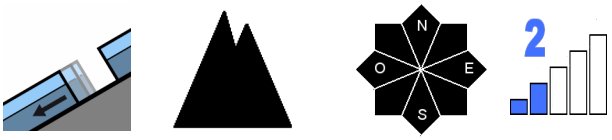	2026-04-22 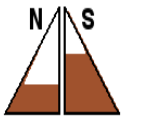 Cota más baja caras N
Ribagorza	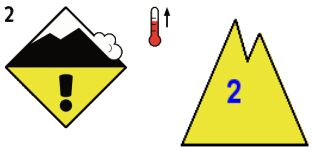 **Limitado**	**Nieve húmeda** **Deslizamientos basales** 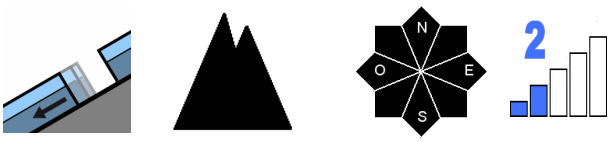	2026-04-22 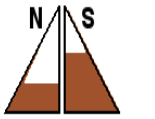 Cota más baja caras N

Estado del manto y observaciones recientes

Continúa el proceso de fusión y humidificación como consecuencia de las altas temperaturas, la insolación y los chubascos que se van produciendo, en forma de lluvia hasta altitudes de unos 2.800 metros, con menguas de varios cm al día en los diferentes puntos de observación. El manto se va replegando a cotas cada vez más altas, en particular en las solanas, donde el suelo desnudo y los afloramientos rocosos ocupan superficies cada vez más extensas. A pesar de ello, aún podemos encontrar espesores que superan los 100 cm por encima de 2.100 metros en numerosas zonas, aún más en ventisqueros y otras áreas propensas a la acumulación.
Nieve típicamente primaveral, muy humedecida y predominio de grano redondo, con rehielo nocturno débil, poco efectivo y prácticamente restringido a la alta montaña.

Evolución del manto y peligro de aludes para el jueves, día 23

Situación de nieve húmeda y deslizamientos basales.

Pocos cambios, con ambiente cálido y previsión de chubascos durante la segunda mitad del día, que allá donde caigan tenderán a humedecer aún más un manto compuesto por nieve vieja muy humedecida. Además, el rehielo nocturno estará generalmente restringido a las zonas de mayor altitud de la cordillera. En consecuencia son probables las purgas de nieve húmeda en pendientes con suficiente inclinación de cualquier orientación, con preferencia en las solanas y áreas afectadas por la lluvia, que podrán ser de tamaño pequeño o, en algunos casos, mediano, pero no se descarta que en laderas herbosas o de roca lisa puedan producirse deslizamiento basales, capaces de adquirir dimensiones incluso grandes, magnitud suficiente como para arrastrar a un grupo de personas, por lo que se recomienda tomar precauciones durante el tránsito.

AEMET. Se autoriza la reproducción de su contenido citando la fuente.

Predicción meteorológica para el jueves, día 23

Poco nuboso o despejado a primeras horas, aunque podrá haber nubes bajas en algunas áreas, localmente asociadas a brumas y nieblas. A partir del mediodía, nubosidad de evolución diurna, con probables chubascos acompañados de tormenta durante la segunda mitad del día, sin descartarse que puedan ser localmente fuertes y con granizo. Cota de nieve: en torno a 2.800 metros. Temperaturas en ligero o moderado descenso. Alguna helada débil en la alta montaña. Vientos flojos o moderados, de componente oeste en cotas altas y con predominio del este y sur en el resto, pudiendo ser más intensos, racheados y dirección variable durante los chubascos o tormentas.

Datos en la atmósfera libre:

Altitud de la isoterma de 0 ºC: 3.200 m
Altitud de la isoterma de -10 ºC: 4.600 m

Viento a 1500 m: SE 30 km/h
Viento a 3000 m: W 20 km/h

Evolución para el viernes día 24

Con pocos cambios.

(Información elaborada a partir de los datos recibidos de los refugios de Linza, Lizara, Respomuso, Panticosa, Bachimaña, Pineta, Estós y Angel Orús y de las estaciones de esquí de Astún, Formigal y Panticosa (lagos))

Escala europea de peligro de aludes

1 Débil — 2 Limitado — 3 Notable — 4 Fuerte — 5 Muy Fuerte

Problemas de aludes

Nieve reciente — Placas de viento — Capas débiles persistentes — Nieve húmeda — Deslizamientos basales — Sin problema evidente

Nota1: Se recuerda que, siempre que haya nieve, la ausencia total de peligro no existe. Hay que tener presente que en circunstancias desfavorables, con aludes de tamaño 1 (alud pequeño o colada) y tamaño 2 (alud mediano), se pueden sufrir severos daños personales.

Nota2: Los BPA se elaboran en base a información meteorológica así como al estado del manto nivoso a través de sondeos puntuales. Se advierte a los usuarios de la variabilidad de esta información al extrapolarla a zonas extensas de montaña. Por ello, AEMET no se hace responsable de su uso para la toma de decisiones que conciernen a la seguridad personal, ni de los riesgos físicos o materiales de ellas derivadas.

AEMET. Se autoriza la reproducción de su contenido citando la fuente.