ICGC Institut Cartogràfic i Geològic de Catalunya

Servei Meteorològic de Catalunya meteo.cat

Boletín de peligro de aludes para el Pirineo de Catalunya
Del 22/04/2026 al 23/04/2026

(Válido fuera pistas de esquí y zonas no controladas)

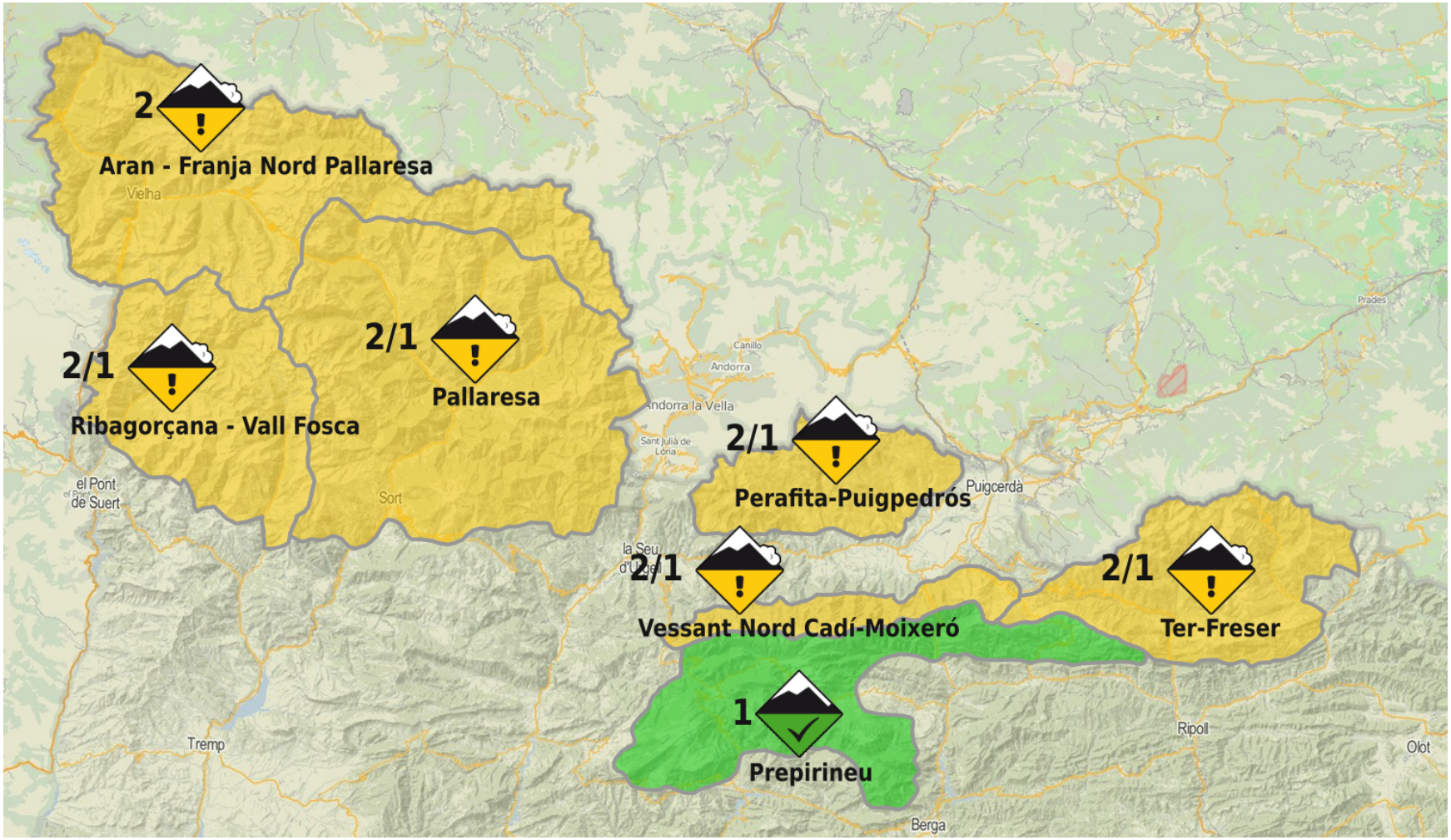

5 MUY FUERTE	4 FUERTE	3 NOTABLE	2 LIMITADO	1 DÉBIL

ICGC Institut Cartogràfic i Geològic de Catalunya

meteo.cat Servei Meteorològic de Catalunya

Boletín de peligro de aludes Aran - Franja Nord Pallaresa Del 22/04/2026 al 23/04/2026

(Válido fuera pistas de esquí y zonas no controladas)

LIMITADO (2).

Situación primaria

Deslizamientos basales **Distribución** **Tamaño** **Origen** **Tendencia**

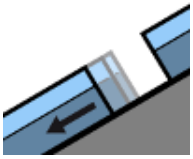

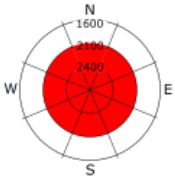

Situación secundaria

Nieve húmeda **Distribución** **Tamaño** **Origen** **Tendencia**

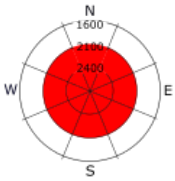

Estado del manto nivoso

Seguiremos con una dinámica primaveral, con rehielo muy poco efectivo y chubascos de tarde que están acabando de humedecer el manto. Durante la madrugada y al amanecer rehiela levemente, pero la nieve se transforma rápidamente con el transcurso de la mañana.

Para este jueves se esperan deslizamientos basales de hasta tamaño 2 (mediano), suficiente para enterrar a una persona y, localmente, no se descarta que puedan alcanzar también el tamaño 3 (grande), con capacidad de enterrar a un grupo de montañeros. Además, son muy probables las caídas naturales de aludes de fusión, que serán, por lo general, también de tamaño mediano.

Es posible la caída de alguna placa húmeda en umbrías elevadas, al humedecerse las capas débiles persistentes. Hay que prestar atención a la aparición de grietas para evitar los deslizamientos y evitar, sobre todo, los momentos de lluvia, que es cuando puede aumentar la actividad de aludes.

Se recomienda empezar temprano las excursiones de montaña y finalizarlas

Distribución del manto nivoso

Hay nieve en el suelo con continuidad por encima de 1.800-1.900 m en umbrías y de 2.000 m en solanas. Los espesores a unos 2.300 m rondan los 100-150 cm en el Aran y rondan los 150-180 cm en la Franja Nord de la Pallaresa. Los valores están algo por encima de los normales para la época.

Tendencia para las próximas 48-72h

Se mantendrá la situación de fusión-rehielo con aludes húmedos a partir de mediodía y en momentos de chubascos. Evolución del peligro: ESTACIONARIO.

El próximo boletín será emitido el día 2026-04-23

5 MUY FUERTE	4 FUERTE	3 NOTABLE	2 LIMITADO	1 DÉBIL

EAWS EUROPEAN AVALANCHE WARNING SERVICES

ICGC Institut Cartogràfic i Geològic de Catalunya

Servei Meteorològic de Catalunya

Boletín de peligro de aludes Ribagorçana - Vall Fosca Del 22/04/2026 al 23/04/2026

(Válido fuera pistas de esquí y zonas no controladas)

LIMITADO (2), a partir de media mañana y con chubascos.
DÉBIL (1), de madrugada y a primera hora.

Situación primaria

Deslizamientos basales **Distribución** **Tamaño** **Origen** **Tendencia**

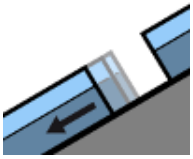

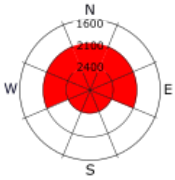

Situación secundaria

Nieve húmeda **Distribución** **Tamaño** **Origen** **Tendencia**

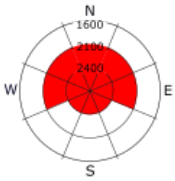

Estado del manto nivoso
Seguiremos con un retroceso progresivo del manto a causa de los chubascos y de las temperaturas positivas. Durante la madrugada y al amanecer rehiela levemente, pero la nieve se transforma en el transcurso de la mañana. Los problemas continuarán relacionados con posibles aludes de nieve húmeda y de deslizamiento basal. Los aludes pueden llegar hasta tamaño 2 (mediano), con capacidad de enterrar a un montañero. Las vertientes más proclives son los terrenos herbosos de fuerte inclinación. Las orientaciones afectadas por deslizamientos y aludes de fusión son todas por encima de 2.100 m en umbrías y por encima de 2.400 m en las solanas. Los tamaños de los aludes de mayor alcance serán en el extremo norte de este sector y por encima de los 2.200 m, donde el grosor movilizable de nieve es mayor. De noche y madrugada el rehielo favorece la estabilidad y el peligro será más débil. Se recomienda empezar temprano las excursiones de montaña y finalizarlas a media mañana.

Distribución del manto nivoso
Hay nieve por encima de 1.900 m pero esquiable en N por encima de 2.100 my de los 2.300 m en S, de forma discontinua. Se alcanzan los 70-90 cm a unos 2.200 m, con frecuentes deflaciones y acumulaciones por encima del nivel del bosque. Estos valores están ligeramente por debajo de los normales para la época.

Tendencia para las próximas 48-72h
Se mantendrá la situación de fusión-rehielo con aludes húmedos a partir de mediodía y en momentos de chubascos. Evolución del peligro: ESTACIONARIO.

El próximo boletín será emitido el día 2026-04-23

5 MUY FUERTE	4 FUERTE	3 NOTABLE	2 LIMITADO	1 DÉBIL

EAWS EUROPEAN AVALANCHE WARNING SERVICES

ICGC Institut Cartogràfic i Geològic de Catalunya

Servei Meteorològic de Catalunya

Boletín de peligro de aludes Pallaresa
Del 22/04/2026 al 23/04/2026

(Válido fuera pistas de esquí y zonas no controladas)

LIMITADO (2), a partir de media mañana y con chubascos.
DÉBIL (1), de madrugada y a primera hora.

Situación primaria

Deslizamientos basales **Distribución** **Tamaño** **Origen** **Tendencia**

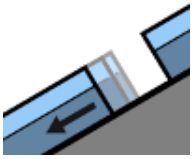

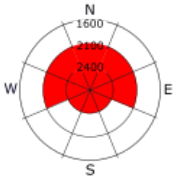

Situación secundaria

Nieve húmeda **Distribución** **Tamaño** **Origen** **Tendencia**

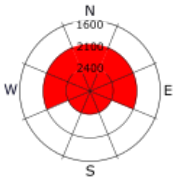

Estado del manto nivoso
Seguiremos con un retroceso progresivo del manto a causa de los chubascos y de las temperaturas positivas. Durante la madrugada y al amanecer rehiela levemente, pero la nieve se transforma en el transcurso de la mañana. Los problemas continuarán relacionados con posibles aludes de nieve húmeda y de deslizamiento basal. Los aludes pueden llegar hasta tamaño 2 (mediano), con capacidad de enterrar a un montañero. Las vertientes más proclives son los terrenos herbosos de fuerte inclinación. Las orientaciones afectadas por deslizamientos y aludes de fusión son todas por encima de 2.100 m en umbrías y por encima de 2.400 m en las solanas. Los tamaños de los aludes de mayor alcance serán en el extremo norte de este sector y por encima de los 2.200 m, donde el grosor movilizable de nieve es mayor. De noche y madrugada el rehielo favorece la estabilidad y el peligro será más débil. Se recomienda empezar temprano las excursiones de montaña y finalizarlas a media mañana.

Distribución del manto nivoso
Hay nieve por encima de 1.800-2.000 m en N por encima de 2.100-2.300 m en S. Se alcanzan los 70-90 cm a unos 2.200 m, con frecuentes deflaciones y acumulaciones por encima del nivel del bosque.

Tendencia para las próximas 48-72h
Se mantendrá la situación de fusión-rehielo con aludes húmedos a partir de mediodía y en momentos de chubascos. Evolución del peligro: ESTACIONARIO.

El próximo boletín será emitido el día 2026-04-23

5 MUY FUERTE	4 FUERTE	3 NOTABLE	2 LIMITADO	1 DÉBIL

EAWS EUROPEAN AVALANCHE WARNING SERVICES

ICGC Institut Cartogràfic i Geològic de Catalunya

Servei Meteorològic de Catalunya

Boletín de peligro de aludes Perafita-Puigpedrós Del 22/04/2026 al 23/04/2026

(Válido fuera pistas de esquí y zonas no controladas)

LIMITADO (2), a partir de media mañana y con chubascos.
DÉBIL (1), de madrugada y a primera hora.

Situación primaria

Deslizamientos basales | **Distribución** | **Tamaño** | **Origen** | **Tendencia**

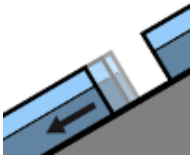

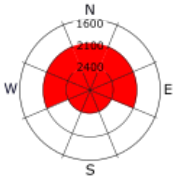

Situación secundaria

Nieve húmeda | **Distribución** | **Tamaño** | **Origen** | **Tendencia**

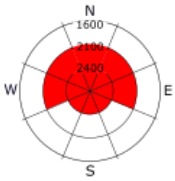

Estado del manto nivoso
Los chubascos, la radiación y las temperaturas positivas mantendrán el manto húmedo y favorecerán su fundición. A primera hora del día aparece un leve encostramiento en umbrías que desaparece en el transcurso de la mañana. Los problemas continuarán relacionados con posibles aludes de nieve húmeda y por algún deslizamiento basal. Los aludes que puedan caer pueden llegar hasta tamaño 2 (mediano), con capacidad de enterrar a un montañero. Las vertientes más proclives son los terrenos herbosos de fuerte inclinación. Las orientaciones afectadas por deslizamientos y aludes de fusión son todas por encima de 2.100 m en umbrías y por encima de 2.400 m en las solanas. Los tamaños de los aludes de mayor alcance serán en el extremo norte de este sector y por encima de los 2.200 m, donde el grosor movilizable de nieve es mayor. De noche y madrugada el rehielo favorece la estabilidad y el peligro será más débil. Se recomienda empezar temprano las excursiones y finalizarlas a media mañana.

Distribución del manto nivoso
Hay nieve por encima de 1.900-2.000 m en orientaciones N y de 2.200 m en Sur. El grosor total en el suelo oscila entre los 30 y los 70 cm a unos 2.400 m, con frecuentes deflaciones y acumulaciones por encima del nivel del bosque. Estos valores están algo por debajo de los normales por la época.

Tendencia para las próximas 48-72h
Se mantendrá la situación de fusión-rehielo con aludes húmedos a partir de mediodía y en momentos de chubascos. Evolución del peligro: ESTACIONARIO.

El próximo boletín será emitido el día 2026-04-23

5 MUY FUERTE	4 FUERTE	3 NOTABLE	2 LIMITADO	1 DÉBIL

EAWS EUROPEAN AVALANCHE WARNING SERVICES

ICGC Institut Cartogràfic i Geològic de Catalunya

Servei Meteorològic de Catalunya

Boletín de peligro de aludes
Vessant Nord Cadí-Moixeró
Del 22/04/2026 al 23/04/2026

(Válido fuera pistas de esquí y zonas no controladas)

LIMITADO (2), a partir de los 2.200 m.
DÉBIL (1), en el resto.

Situación primaria

Nieve húmeda

Distribución

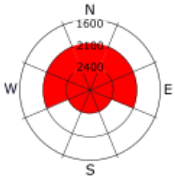

Tamaño

Origen

Tendencia

Estado del manto nivoso
Los chubascos de tarde, la intensa radiación y las temperaturas positivas mantendrán el manto húmedo y favorecerán su fundición. A primera hora del día aparece un leve encostramiento en umbrías que desaparece rápidamente con el transcurso de la mañana. Para el jueves se esperan caídas naturales de aludes de fusión, sobre todo en momentos de chubascos en cualquier orientación y alcanzarán mayor alcance por encima de los 2.200 m, donde hay mayor grosor de manto movilizable. En caso de que se desencadenen pueden alcanzar tamaño 2 (mediano), suficiente para enterrar a un montañero. Los sectores más peligrosos son los canales donde los grosores acumulados son mayores. Habrá que evitar los momentos de chubascos y las horas de mayor humedecimiento. Se recomienda empezar las actividades de montaña temprano y finalizarlas a media mañana.

Distribución del manto nivoso
Hay nieve por encima de 1.900 m en N y de 2.100 m en S. Se alcanzan los 100-130 cm a unos 2.200 m, con frecuentes deflaciones y acumulaciones por encima del nivel del bosque. Estos valores están por encima de los normales para la época.

Tendencia para las próximas 48-72h
Se mantendrá la situación de fusión-rehielo con aludes húmedos a partir de mediodía y en momentos de chubascos. Evolución del peligro: ESTACIONARIO.

El próximo boletín será emitido el día 2026-04-23

5 MUY FUERTE	4 FUERTE	3 NOTABLE	2 LIMITADO	1 DÉBIL

EAWS EUROPEAN AVALANCHE WARNING SERVICES

ICGC Institut Cartogràfic i Geològic de Catalunya

Servei Meteorològic de Catalunya meteo.cat

Boletín de peligro de aludes Prepirineu
Del 22/04/2026 al 23/04/2026

(Válido fuera pistas de esquí y zonas no controladas)

DÉBIL (1).

Situación primaria

Nieve húmeda

Distribución

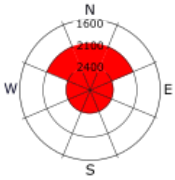

Tamaño

Origen

Tendencia

Estado del manto nivoso

Los chubascos de tarde, la intensa radiación y las temperaturas positivas mantendrán el manto húmedo y favorecerán su fundición. De madrugada y a primera hora del día aparece un leve encostramiento a umbrías que desaparece rápidamente con el transcurso de la mañana. Con estas condiciones, para este jueves se esperan caídas naturales de aludes de fusión, sobre todo en momentos de chubascos, en umbrías, donde hay más grosor de manto movilizable. Los aludes llegarán a tamaño 1 (pequeño), sin capacidad para enterrar a un montañero. Los sectores más peligrosos es el terreno trampa, como las depresiones, donde los grosores acumulados en caso de alud pueden ser mayores. Habrá que evitar los momentos de chubascos y las horas de mayor humedecimiento. Se recomienda empezar temprano las excursiones de montaña y finalizarlas a media mañana.

Distribución del manto nivoso

Hay nieve por encima de 1.900 m en N y es más continua a partir de 2.100 m. En orientación Sur es discontinua a partir de 2.200 m. Encontramos alrededor de 50-70 cm de nieve en el suelo a unos 2.300 m, en umbrías, con frecuentes deflaciones y acumulaciones por encima del nivel del bosque.

Tendencia para las próximas 48-72h

Se mantendrá la situación de fusión-rehielo con aludes húmedos a partir de mediodía y en momentos de chubascos. Evolución del peligro: ESTACIONARIO.

El próximo boletín será emitido el día 2026-04-23

5 MUY FUERTE	4 FUERTE	3 NOTABLE	2 LIMITADO	1 DÉBIL

EAWS EUROPEAN AVALANCHE WARNING SERVICES

ICGC Institut Cartogràfic i Geològic de Catalunya

Servei Meteorològic de Catalunya

Boletín de peligro de aludes Ter-Freser
Del 22/04/2026 al 23/04/2026

(Válido fuera pistas de esquí y zonas no controladas)

LIMITADO (2), a partir de media mañana y con chubascos.
DÉBIL (1), de madrugada y a primera hora.

Situación primaria

Deslizamientos basales **Distribución** **Tamaño** **Origen** **Tendencia**

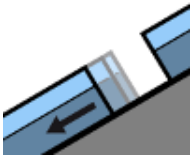

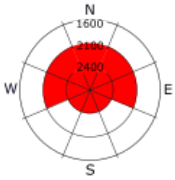

Situación secundaria

Nieve húmeda **Distribución** **Tamaño** **Origen** **Tendencia**

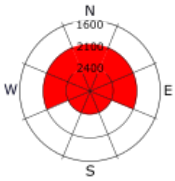

Estado del manto nivoso
Los chubascos, la intensa radiación y las temperaturas positivas mantendrán el manto húmedo y favorecerán su fundición. A primera hora del día aparece un leve encostramiento a umbrías que desaparece rápidamente con el transcurso de la mañana. Los problemas continuarán relacionados con posibles aludes de nieve húmeda y por algún deslizamiento basal. Los aludes que puedan caer pueden llegar hasta tamaño 2 (mediano), con capacidad de enterrar a un montañero. Las vertientes más proclives son los terrenos herbosos de fuerte inclinación. Las orientaciones afectadas por deslizamientos y aludes de fusión son todas por encima de 2.100 m en umbrías y por encima de 2.400 m en las solanas. Los tamaños de los aludes de mayor alcance serán en el extremo norte de este sector y por encima de los 2.200 m, donde el grosor movilizable de nieve es mayor. De madrugada el rehielo favorece la estabilidad y el peligro será débil. Se recomienda empezar temprano las excursiones y finalizarlas a media mañana.

Distribución del manto nivoso
Hay nieve por encima de 1.900 m en N y de 2.100 - 2.200 m en S. Los espesores rondan los 40-70 cm a unos 2.200 m, y más de 130-190 cm por encima de 2.400 m, con frecuentes deflaciones y acumulaciones por encima del nivel del bosque . Estos valores están por encima de la media.

Tendencia para las próximas 48-72h
Se mantendrá la situación de fusión-rehielo con aludes húmedos a partir de mediodía y en momentos de chubascos. Evolución del peligro: ESTACIONARIO.

El próximo boletín será emitido el día 2026-04-23

5 MUY FUERTE	4 FUERTE	3 NOTABLE	2 LIMITADO	1 DÉBIL

EAWS EUROPEAN AVALANCHE WARNING SERVICES