Bulletin d'estimation du risque d'avalanche

(valable en dehors des pistes balisées et ouvertes)

MASSIF : Bauges

Rédigé le mercredi 22 avril 2026 à 16h

Estimation des risques pour le : JEUDI 23 AVRIL

POURSUITE DE L'HUMIDIFICATION DU MANTEAU NEIGEUX.

1

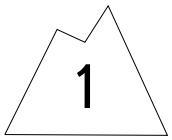

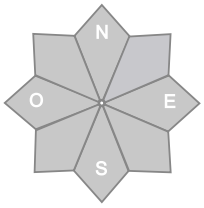

Indice de risque faible.

Départs spontanés : rares avalanches de neige humide

Déclenchements provoqués : rares avalanches de neige humide

Indices de risque : 5 très fort - 4 fort - 3 marqué - 2 limité - 1 faible -- En noir : les pentes les plus dangereuses

Stabilité du manteau neigeux

Situation avalancheuse typique : avalanches de fond neige humide

Départs spontanés :
* fissures de reptation sur pentes raides herbeuses très raides et dalles rocheuses. Plaques de fond rares mais possibles, à toute heure. Taille 1 à 2 (petite à moyenne).

Déclenchements provoqués :
* un skieur peut pousser une avalanche de neige humide, une fois le manteau réchauffé par le soleil. Principalement en pentes raides. Taille 1 à 2.
Observables : enfoncement piéton important.

Qualité de la neige

Enneigement :
Il reste encore pas mal de neige dans les ubacs au-dessus de 1600 m. Dans les versants S, on peut encore trouver quelques bancs de neige au-dessus de 1800 m.

Qualité de la neige ce jeudi :
* manteau neigeux printanier. Bon regel nocturne : neige dure le matin, puis rapidement humide, voire très humide en journée.

Aperçu météo pour le jeudi 23 avril

nuit	matin	après-midi	soir

Ensoleillé, rares cumulus l'après-midi. Températures à 1500 m : 3/12°C.

Pluie-Neige				
Iso 0 °C	2 600 m	2 700 m	2 900 m	3 100 m
Vent 1500 m	5 km/h	5 km/h	5 km/h	5 km/h
Vent 2000 m	10 km/h	10 km/h	10 km/h	10 km/h

Épaisseur de neige hors-piste

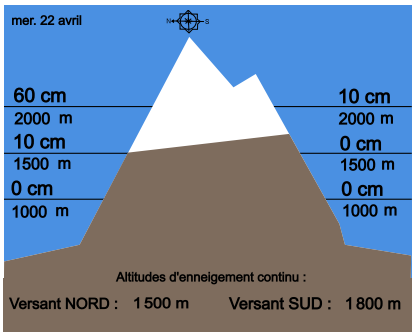

Précipitations à 1800 m

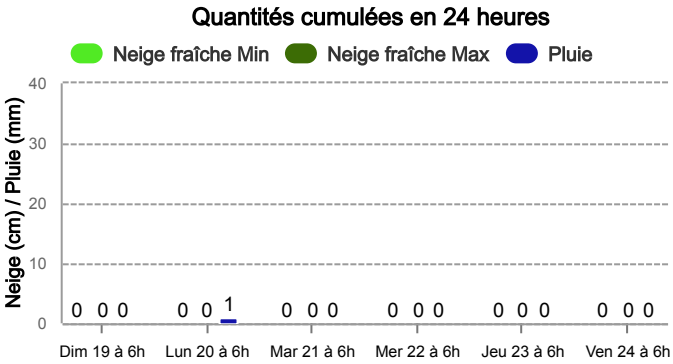

Tendance du vendredi 24 avril

1

Indice de risque faible

Ensoleillé, températures en hausse.
Poursuite de l'humidification du manteau neigeux.

Pour consulter la vigilance en cours, veuillez vous rendre sur le site https://vigilance.meteofrance.fr/fr

Météo-France - 73 avenue de Paris, 94165 Saint-Mandé cedex - Contact : contact@meteo.fr

Rédigé par Météo-France avec la contribution des observateurs du réseau nivo-météorologiques. Partenariat : ANMSM (Maires de Stations de Montagne), DSF (Domaines Skiables de France), ADSP (Directeurs de Pistes et de la Sécurité des Stations de Sports d'Hiver) et autres acteurs de la montagne.

Bulletin neige & avalanches par téléphone au
0 892 68 10 20 Service 0,35 € / min + prix appel

RÉPUBLIQUE FRANÇAISE
Liberté Égalité Fraternité

METEO FRANCE
À VOS CÔTÉS, DANS UN CLIMAT QUI CHANGE

Bulletin d'estimation du risque d'avalanche

(valable en dehors des pistes balisées et ouvertes)

MASSIF : Bauges

Rédigé le mercredi 22 avril 2026 à 16h

Conditions nivo-météo des 7 derniers jours

	jeu. 16/04				ven. 17/04				sam. 18/04				dim. 19/04				lun. 20/04				mar. 21/04				mer. 22/04			
	03h	09h	15h	21h	03h	09h	15h	21h	03h	09h	15h	21h	03h	09h	15h	21h	03h	09h	15h	21h	03h	09h	15h	21h	03h	09h	15h	21h
Météo																												
Vent (km/h)	20	15	20	10	20	20	10	10	10	10	10	10	15	25	25	15	20	25	30	20	20	20	30	20	20	15	10	10
à 2000m	↓	↙	↓	↑	↗	↗	↗	↑	↓	↙	↓	↻	→	↗	↘	↘	→	↗	↘	↓	↓	↘	↘	↓	↘	↗	↘	↙
Vent (km/h)	15	10	15	5	10	10	5	5	5	5	5	5	10	15	20	10	10	15	20	10	10	15	20	10	10	10	5	5
à 1500m	↓	↓	↓	↻	↙	↑	↻	↻	↙	↙	↓	↻	↑	→	→	↗	↑	↘	↘	↓	↓	↓	↓	↓	↙	↻	↘	↓

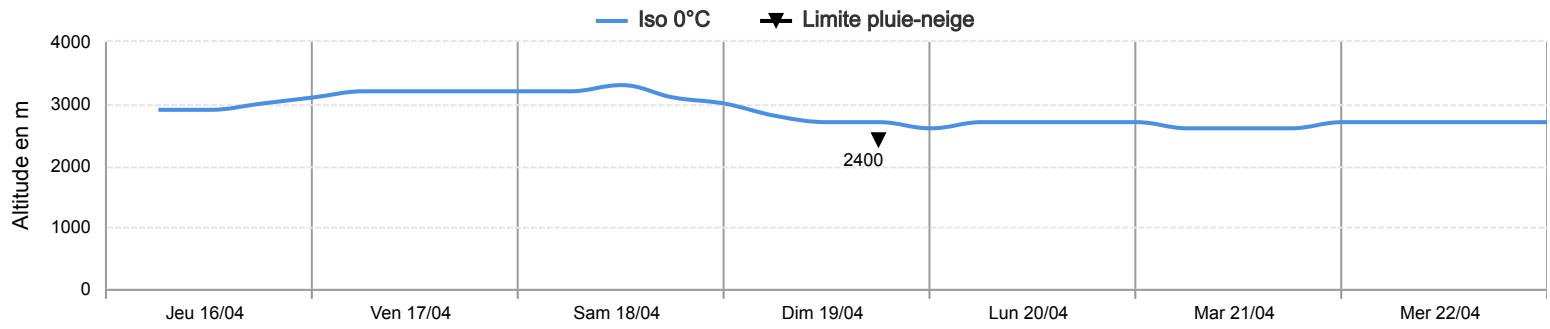

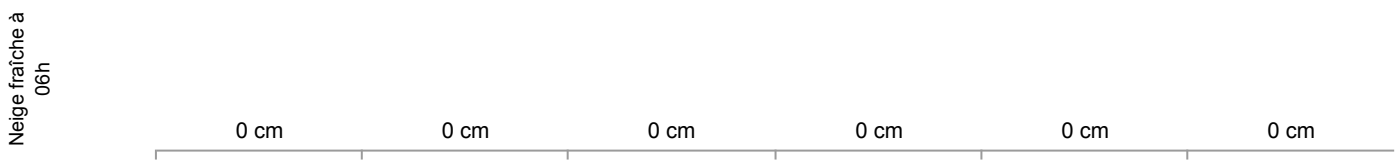

Risque d'avalanche	jeu. 16/04	ven. 17/04	sam. 18/04	dim. 19/04	lun. 20/04	mar. 21/04	mer. 22/04
	2	2	1	1	1	1	1

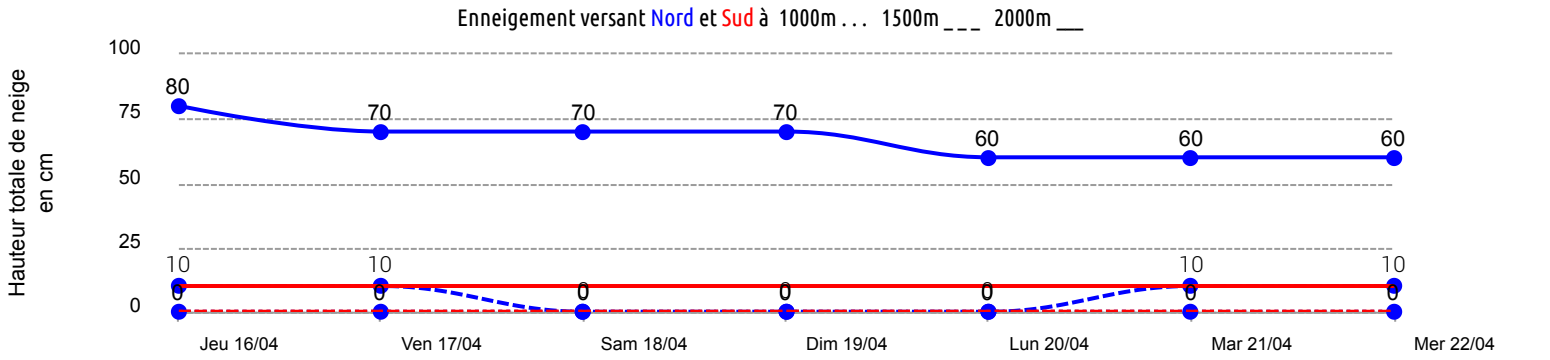

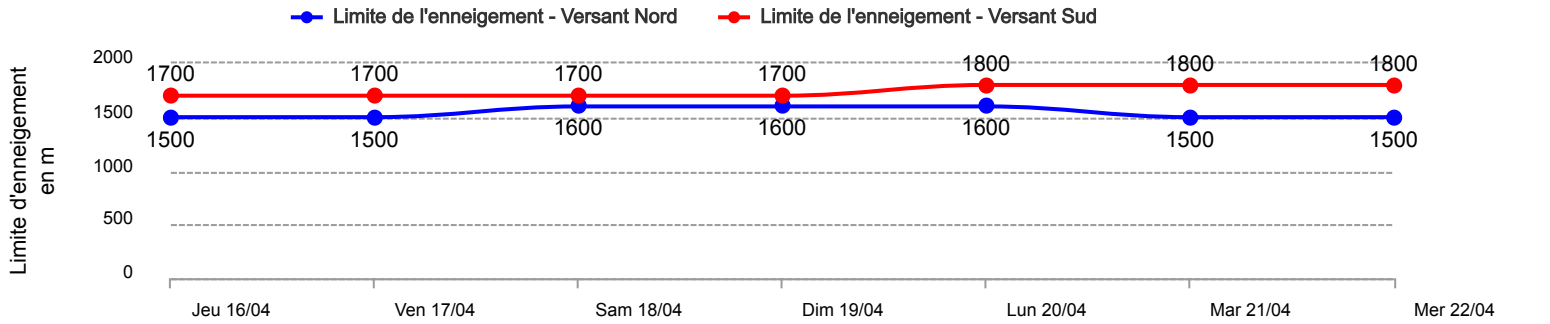

Pour consulter la vigilance en cours, veuillez vous rendre sur le site https://vigilance.meteofrance.fr/fr

Météo-France - 73 avenue de Paris, 94165 Saint-Mandé cedex - Contact : contact@meteo.fr

Rédigé par Météo-France avec la contribution des observateurs du réseau nivo-météorologiques. Partenariat : ANMSM (Maires de Stations de Montagne), DSF (Domaines Skiables de France), ADSP (Directeurs de Pistes et de la Sécurité des Stations de Sports d'Hiver) et autres acteurs de la montagne.

Bulletin neige & avalanches par téléphone au
0 892 68 10 20 Service 0,35 € / min + prix appel