Bulletin d'estimation du risque d'avalanche
(valable en dehors des pistes balisées et ouvertes)

MASSIF : Chablais

Rédigé le mercredi 22 avril 2026 à 16h

Estimation des risques pour le : JEUDI 23 AVRIL

POURSUITE DE L'HUMIDIFICATION DU MANTEAU NEIGEUX.

2

1 → 2

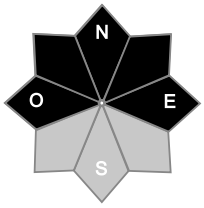

Indice de risque faible évoluant en limité.

Départs spontanés : rares avalanches de neige humide

Déclenchements provoqués : rares avalanches de neige humide

Indices de risque : 5 très fort - 4 fort - 3 marqué - 2 limité - 1 faible -- En noir : les pentes les plus dangereuses

Stabilité du manteau neigeux

Situation avalancheuse typique : neige humide — avalanches de fond

Départs spontanés :
* avalanches de neige humide, au fil du réchauffement par le soleil. Possibles toutes orientations et altitudes, mais plus probables en versants E et W bien réchauffés et raides, où il reste encore beaucoup de neige. Taille 1 à 2 (petite à moyenne).
* plaques de fond, plutôt rares mais encore possibles. En pentes raides herbeuses. Avec ou sans fissure préalable (gueule de baleine) Taille 1 à 2.
* rare mais pas impossible, la combinaison des deux types d'avalanches, dans une longue pente encore bien chargée, pourrait terminer en taille 3 (grande).

Déclenchements provoqués :
* avalanches de neige humide : un skieur, en coupant une pente raide aux heures suffisamment chaudes, peut déclencher une coulée de neige humide, pouvant atteindre la taille 2+.

Observables : enfoncement piéton important.

Qualité de la neige

Enneigement :
Pour la saison, l'enneigement est correct au-dessus de 2000 m, en dessous, il est déficitaire.
On peut chausser les skis au-dessus de 1800 m en S, 1500 m en N.

Qualité de la neige ce jeudi :
* manteau neigeux printanier à toutes les altitudes. Durant la nuit, le bon regel durcit la neige. Elle ramollit et s'humidifie rapidement en journée.
* les crêtes et les arêtes sont souvent décapées.
* encore quelques corniches molles à surveiller.

Aperçu météo pour le jeudi 23 avril

	nuit	matin	après-midi	soir

Ensoleillé, rares cumulus l'après-midi. Températures à 2000 m : 1/9°C.

Pluie-Neige				
Iso 0 °C	2 600 m	2 700 m	3 000 m	3 100 m
Vent 2000 m	5 km/h	15 km/h	10 km/h	10 km/h
Vent 2500 m	10 km/h	20 km/h	20 km/h	20 km/h

Épaisseur de neige hors-piste

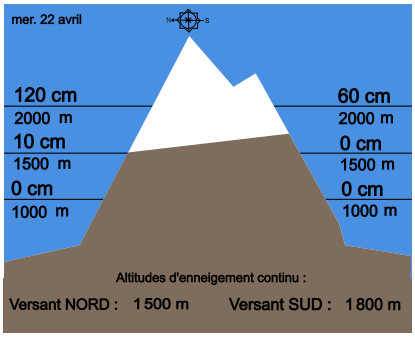

Précipitations à 1800 m

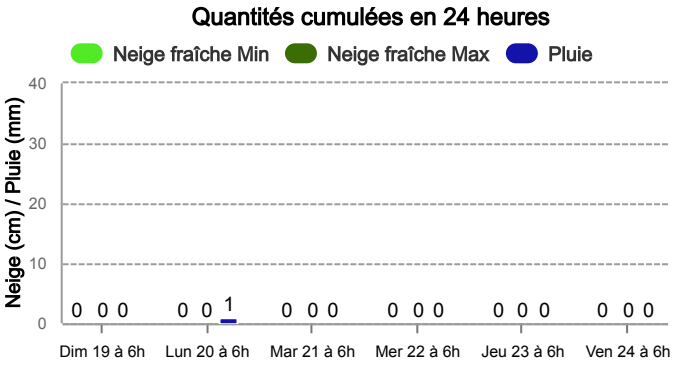

Tendance du vendredi 24 avril

2

Indice de risque limité

Ensoleillé, températures en hausse.
Poursuite de l'humidification du manteau neigeux.

Pour consulter la vigilance en cours, veuillez vous rendre sur le site https://vigilance.meteofrance.fr/fr

Météo-France - 73 avenue de Paris, 94165 Saint-Mandé cedex - Contact : contact@meteo.fr

Rédigé par Météo-France avec la contribution des observateurs du réseau nivo-météorologiques. Partenariat : ANMSM (Maires de Stations de Montagne), DSF (Domaines Skiables de France), ADSP (Directeurs de Pistes et de la Sécurité des Stations de Sports d'Hiver) et autres acteurs de la montagne.

Bulletin neige & avalanches par téléphone au
0 892 68 10 20 Service 0,35 € / min + prix appel

RÉPUBLIQUE FRANÇAISE
Liberté Égalité Fraternité

METEO FRANCE
À VOS CÔTÉS, DANS UN CLIMAT QUI CHANGE

Bulletin d'estimation du risque d'avalanche

(valable en dehors des pistes balisées et ouvertes)

MASSIF : Chablais

Rédigé le mercredi 22 avril 2026 à 16h

Conditions nivo-météo des 7 derniers jours

	jeu. 16/04				ven. 17/04				sam. 18/04				dim. 19/04				lun. 20/04				mar. 21/04				mer. 22/04			
	03h	09h	15h	21h	03h	09h	15h	21h	03h	09h	15h	21h	03h	09h	15h	21h	03h	09h	15h	21h	03h	09h	15h	21h	03h	09h	15h	21h
Météo																												
Vent (km/h)	15	15	10	15	20	20	20	20	10	10	15	15	20	25	25	30	30	25	20	20	20	20	30	20	20	20	10	10
à 2500m																												
Vent (km/h)	10	10	5	10	10	10	10	10	5	5	10	10	15	20	15	20	15	15	15	10	10	15	20	10	15	10	5	5
à 2000m																												

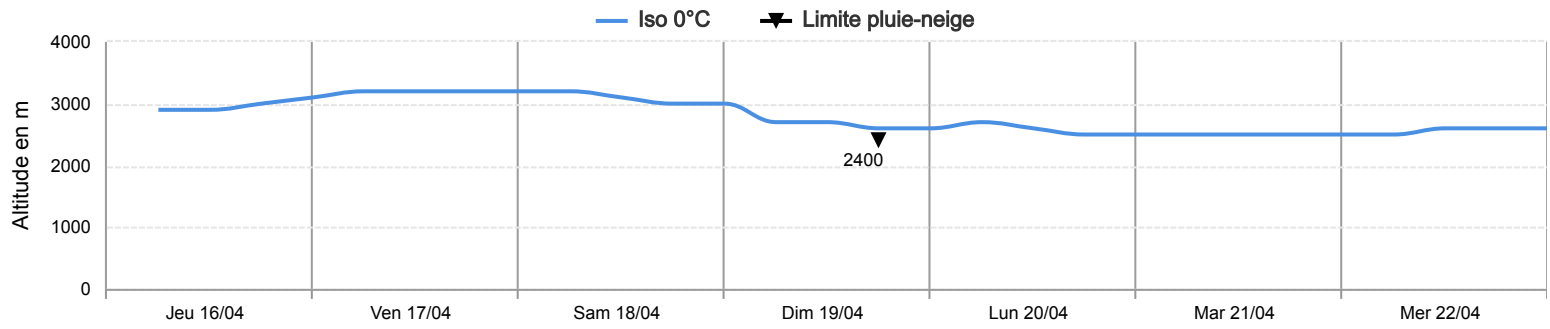

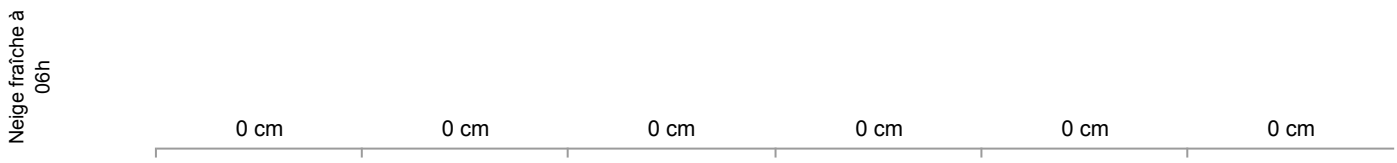

Risque d'avalanche	jeu. 16/04	ven. 17/04	sam. 18/04	dim. 19/04	lun. 20/04	mar. 21/04	mer. 22/04
	2	2	2	2	2	2	2

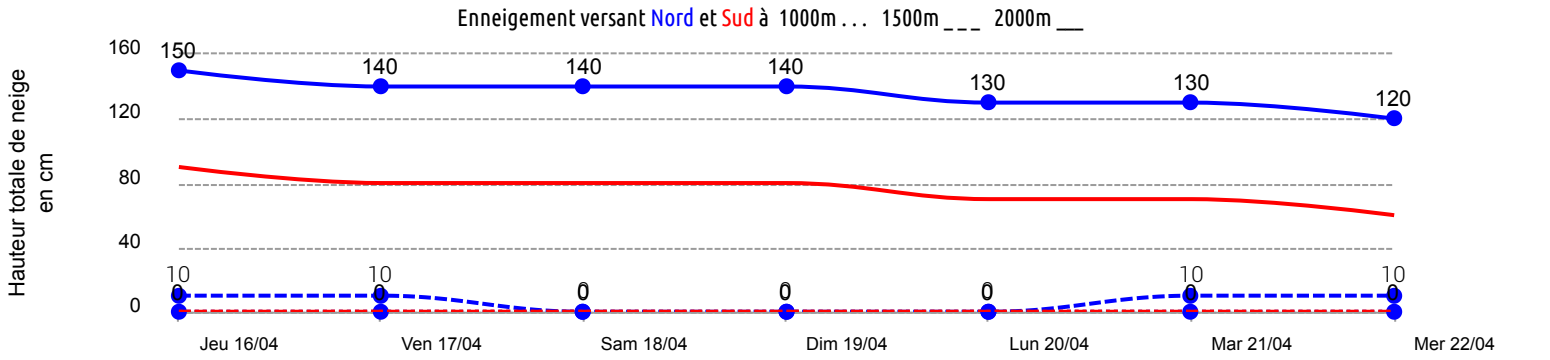

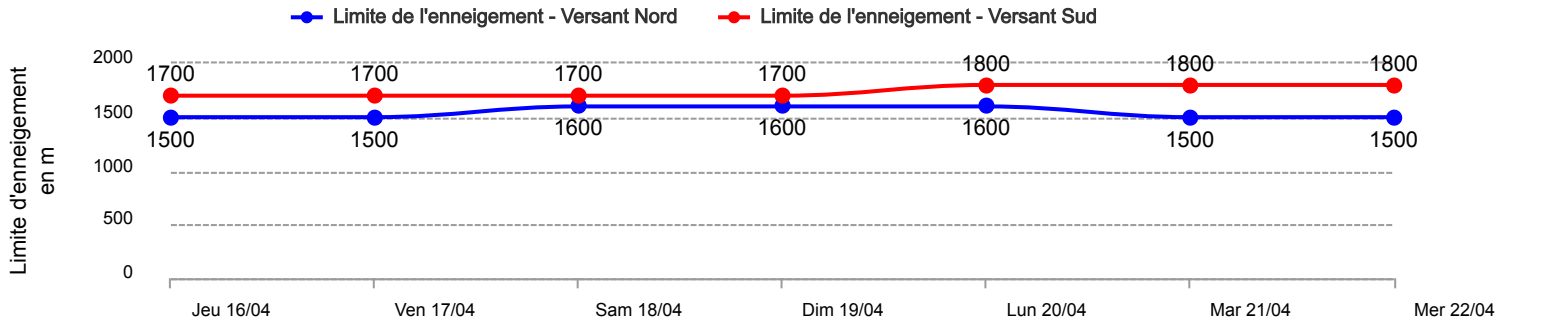

Pour consulter la vigilance en cours, veuillez vous rendre sur le site https://vigilance.meteofrance.fr/fr

Météo-France - 73 avenue de Paris, 94165 Saint-Mandé cedex - Contact : contact@meteo.fr

Rédigé par Météo-France avec la contribution des observateurs du réseau nivo-météorologiques. Partenariat : ANMSM (Maires de Stations de Montagne), DSF (Domaines Skiables de France), ADSP (Directeurs de Pistes et de la Sécurité des Stations de Sports d'Hiver) et autres acteurs de la montagne.

Bulletin neige & avalanches par téléphone au
0 892 68 10 20 Service 0,35 € / min + prix appel