Bulletin d'estimation du risque d'avalanche

(valable en dehors des pistes balisées et ouvertes)

MASSIF : Champsaur

Rédigé le mercredi 22 avril 2026 à 16h

Estimation des risques pour le : JEUDI 23 AVRIL

MANTEAU NEIGEUX PRINTANIER - REPRISE DE L'ACTIVITÉ EN NEIGE HUMIDE

2

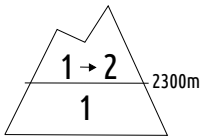

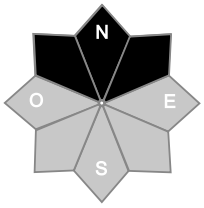

Au-dessus de 2300m indice de risque faible évoluant en limité, plus bas indice faible.

Départs spontanés : en neige humide en altitude.

Déclenchements provoqués : en neige humide en altitude.

Indices de risque : 5 très fort - 4 fort - 3 marqué - 2 limité - 1 faible -- En noir : les pentes les plus dangereuses

Stabilité du manteau neigeux

Situation avalancheuse typique : neige humide

Départs spontanés : peu probables en tout début de journée après le regel nocturne, puis reprise de l'humidification au fil de la course du soleil avec la hausse de l'isotherme 0 degré. Quelques départs superficiels sont alors possibles en journée, avalanches de petite taille (taille 1) en général. Néanmoins, un départ de plus grande ampleur est possible dans les pentes nord-ouest à nord-est au-dessus de 2300/2400 m environ, emportant la totalité du manteau neigeux. Avalanches de taille moyenne à grande (taille 2 à 3), dans le cas où l'humidification atteint des couches fragiles persistantes enfouies dans le manteau neigeux.

Déclenchements provoqués : un skieur coupant une pente raide trop tardivement peut initier un départ de neige humide sous ses skis, plutôt dans les versants nord d'altitude comprise entre 2200 et 2600 m, et en versants nord-ouest à nord-est entre 2600 et 3000 m. Départs ponctuels engendrant des avalanches de petite taille (taille 1), plus rarement moyenne (taille 2), voire exceptionnellement grande (taille 3). Une première avalanche superficielle de neige humide déclenchée par un skieur peut dans de rares cas provoquer un second départ linéaire plus volumineux en venant solliciter une couche fragile persistante plus profondément enfouie dans le manteau neigeux.

Qualité de la neige

Enneigement désormais déficitaire, notamment en adrets.
Hauteurs de neige observées : 112 cm au-dessus de Prapic à 2500 m, 60 cm à la nivôse d'Orcières à 2300 m.

Limite d'enneigement skiable : très localement vers 1600/1700 m en fond de vallée en cœur de massif, 2200/2400 m en adrets.

État de la neige de surface : manteau neigeux printanier, voire de névé en toute orientation sous 2200 m environ et en adrets jusqu'à 3000 m d'altitude. On trouve encore de la neige froide en versants nord de haute altitude au delà de 2900/3000 m. Regel nocturne correct, puis reprise de l'humidification avec le retour du soleil et la hausse de l'isotherme 0 degré.

Aperçu météo pour le jeudi 23 avril

nuit	matin	après-midi	soir

Bien ensoleillé et températures en hausse. Vent d'est à nord-est faible en altitude.

Pluie-Neige				
Iso 0 °C	2 400 m	2 600 m	2 800 m	3 100 m
Vent 2000 m	← 5 km/h	← 10 km/h	→ 15 km/h	← 10 km/h
Vent 3000 m	→ 20 km/h	← 15 km/h	↖ 15 km/h	↙ 15 km/h

Épaisseur de neige hors-piste

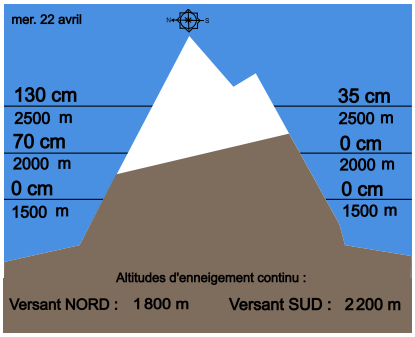

Précipitations à 1800 m

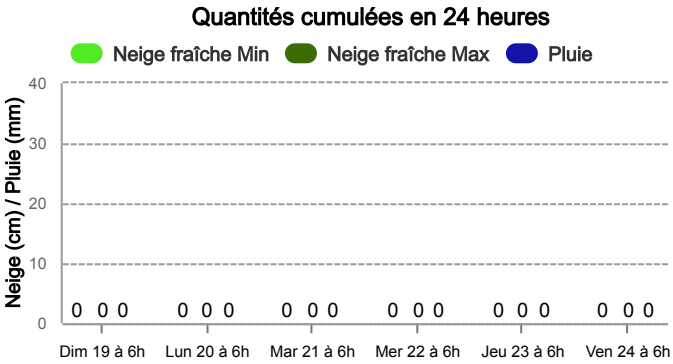

Tendance du vendredi 24 avril

2

Indice de risque limité

Maintien d'un risque limité avec l'activité en neige humide qui est en hausse en cours de journée.

Pour consulter la vigilance en cours, veuillez vous rendre sur le site https://vigilance.meteofrance.fr/fr

Météo-France - 73 avenue de Paris, 94165 Saint-Mandé cedex - Contact : contact@meteo.fr

Rédigé par Météo-France avec la contribution des observateurs du réseau nivo-météorologiques. Partenariat : ANMSM (Maires de Stations de Montagne), DSF (Domaines Skiables de France), ADSP (Directeurs de Pistes et de la Sécurité des Stations de Sports d'Hiver) et autres acteurs de la montagne.

Bulletin neige & avalanches par téléphone au 0 892 68 10 20 Service 0,35 € / min + prix appel

RÉPUBLIQUE FRANÇAISE
Liberté Égalité Fraternité

METEO FRANCE
À VOS CÔTÉS, DANS UN CLIMAT QUI CHANGE

Bulletin d'estimation du risque d'avalanche
(valable en dehors des pistes balisées et ouvertes)

MASSIF : Champsaur

Rédigé le mercredi 22 avril 2026 à 16h

Conditions nivo-météo des 7 derniers jours

	jeu. 16/04				ven. 17/04				sam. 18/04				dim. 19/04				lun. 20/04				mar. 21/04				mer. 22/04			
	03h	09h	15h	21h	03h	09h	15h	21h	03h	09h	15h	21h	03h	09h	15h	21h	03h	09h	15h	21h	03h	09h	15h	21h	03h	09h	15h	21h
Météo																												
Vent (km/h)	10	10	10	10	5	10	10	10	10	10	15	10	15	20	25	20	20	20	25	20	20	20	25	20	20	25	25	15
à 3000m																												
Vent (km/h)	10	10	10	5	5	10	10	5	5	5	15	10	10	10	25	10	10	15	25	10	10	10	25	10	15	15	25	10
à 2000m																												

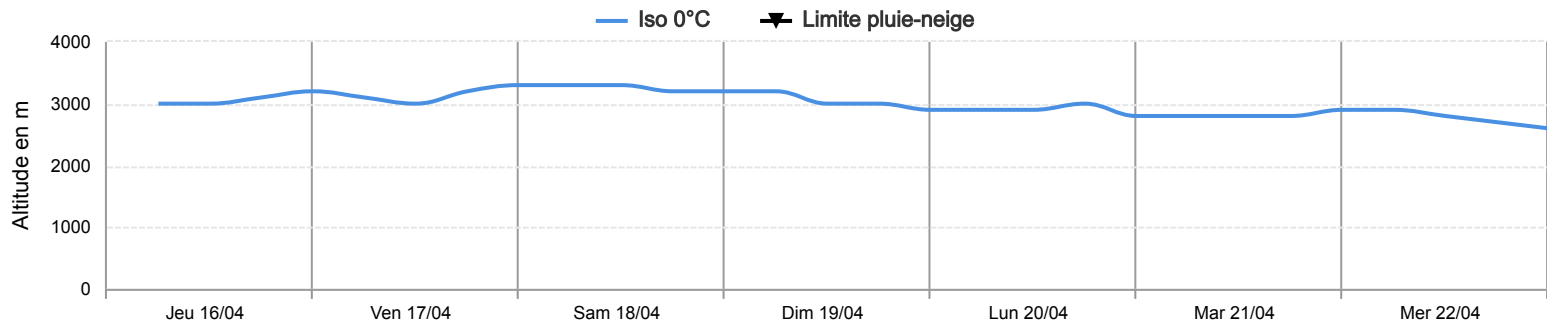

Neige fraîche à 06h

jeu. 16/04	ven. 17/04	sam. 18/04	dim. 19/04	lun. 20/04	mar. 21/04	mer. 22/04
0 cm	0 cm	0 cm	0 cm	0 cm	0 cm	

Risque d'avalanche	jeu. 16/04	ven. 17/04	sam. 18/04	dim. 19/04	lun. 20/04	mar. 21/04	mer. 22/04
	2	2	2	2	2	2	1

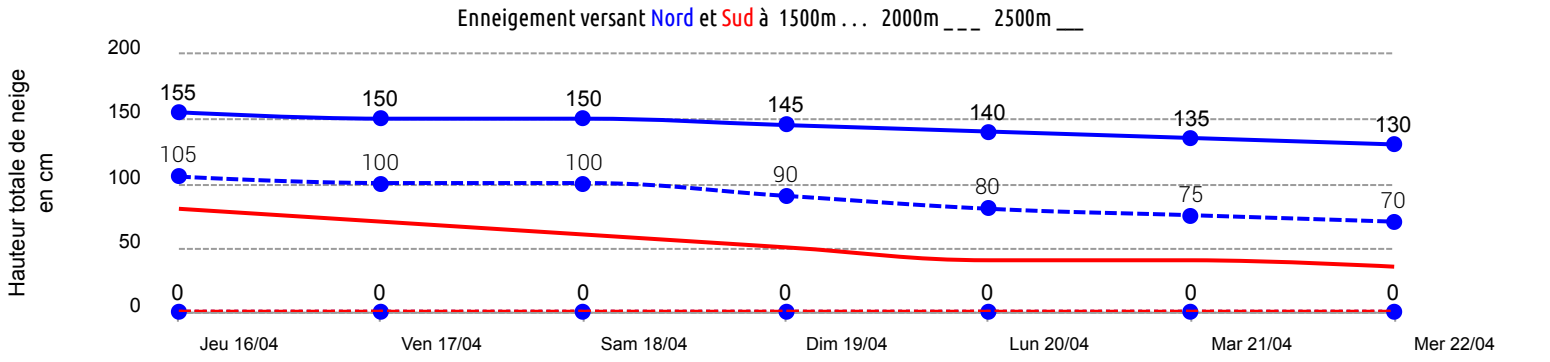

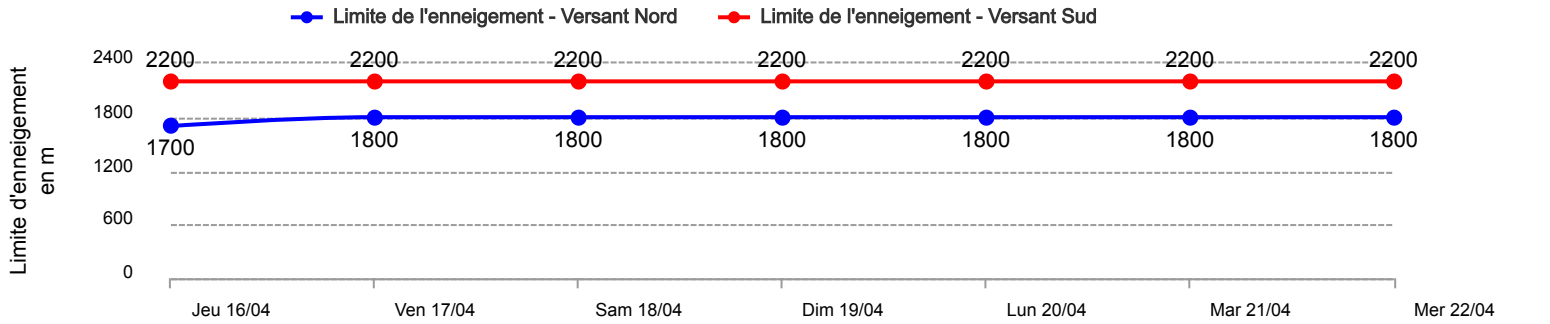

Pour consulter la vigilance en cours, veuillez vous rendre sur le site https://vigilance.meteofrance.fr/fr

Météo-France - 73 avenue de Paris, 94165 Saint-Mandé cedex - Contact : contact@meteo.fr

Rédigé par Météo-France avec la contribution des observateurs du réseau nivo-météorologiques. Partenariat : ANMSM (Maires de Stations de Montagne), DSF (Domaines Skiables de France), ADSP (Directeurs de Pistes et de la Sécurité des Stations de Sports d'Hiver) et autres acteurs de la montagne.

Bulletin neige & avalanches par téléphone au
0 892 68 10 20 Service 0,35 € / min + prix appel