Bulletin d'estimation du risque d'avalanche
(valable en dehors des pistes balisées et ouvertes)

MASSIF : Haut-Var Haut-Verdon

Rédigé le mercredi 22 avril 2026 à 16h

Estimation des risques pour le : JEUDI 23 AVRIL

MANTEAU NEIGEUX PRINTANIER - UN PEU D'ACTIVITÉ EN NEIGE HUMIDE

2

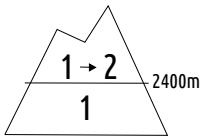

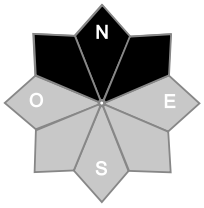

Au-dessus de 2400m indice de risque faible évoluant en limité, plus bas indice faible.

Départs spontanés : avalanches en neige humide. Rares, mais possiblement volumineuses en ubacs d'altitude.

Déclenchements provoqués : en neige humide sous les skis.

Indices de risque : 5 très fort - 4 fort - 3 marqué - 2 limité - 1 faible -- En noir : les pentes les plus dangereuses

Stabilité du manteau neigeux

Situation avalancheuse typique : neige humide

Départs spontanés : avalanches en neige humide restant rares mais pouvant être volumineuse en cas de départ linéaire. Taille moyenne, grande non exclue, dans les pentes nord-ouest / nord / nord-est au-dessus de 2400 m environ, pouvant emporter la totalité du manteau neigeux en place. Peu probables en début de journée, puis risque en augmentation au fil du réchauffement au soleil. Dans les autres orientations / altitudes, le manteau neigeux printanier, dense est bien stabilisé. Le risque de départ en neige humide est peu probable ou se limite à quelques départs ponctuels superficiels en pente raide près des rochers, de la petite couche de neige fraiche en altitude.

Déclenchements provoqués : un skieur coupant une pente raide trop tardivement peut initier un départ de neige humide sous ses skis. Dans les ubacs d'altitude supérieure à 2400 m environ, une première avalanche superficielle de neige humide déclenchée par un skieur peut dans de très rares cas provoquer un second départ linéaire plus volumineux.

Qualité de la neige

Enneigement nettement déficitaire pour la période, avec une fonte qui se poursuit à un rythme élevé. Absence de précipitations significatives depuis plus d'1 mois et grande douceur en place depuis début avril.
Hauteurs de neige observées : vers 2000 m, 85 cm dans le vallon de Valdemars dans le Haut-Verdon, 9 cm à la Sanguinière dans le Haut-Var.

Enneigement skiable généralement à partir de 1900/2000 m en ubacs sur terrain favorable (routes forestières, terrains herbeux) et 2400 m en adrets peu pentus.

État de la neige en surface : un peu de neige fraiche au-dessus de 2500 m environ, s'humidifiant en journée. Manteau neigeux printanier sous 2400 m environ ou en adrets d'altitude. Dense. Regel aléatoire. Manteau neigeux pas totalement transformé en ubac au dessus de 2400 m environ.

Aperçu météo pour le jeudi 23 avril

	nuit	matin	après-midi	soir
Retour du soleil				
Pluie-Neige				
Iso 0 °C	2 300 m	2 400 m	2 700 m	2 900 m
Vent 2000 m	10 km/h	15 km/h	20 km/h	10 km/h
Vent 3000 m	20 km/h	20 km/h	20 km/h	20 km/h

Épaisseur de neige hors-piste

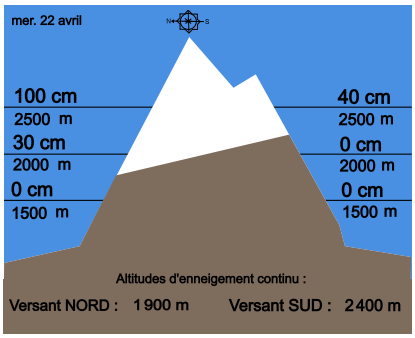

Précipitations à 1800 m

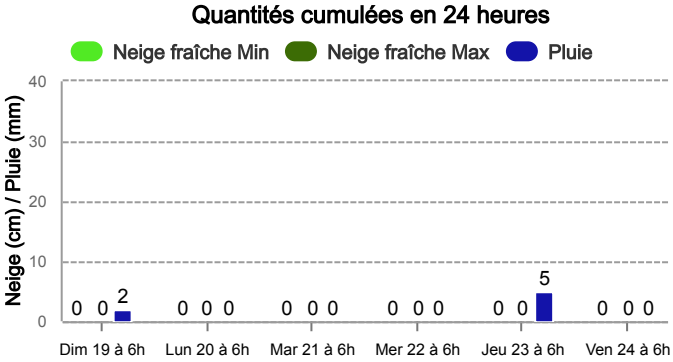

Tendance du vendredi 24 avril

2

Indice de risque limité

La situation nivologique reste pilotée par l'activité en neige humide au cours de la journée. Rares départs linéaires volumineux dans les ubacs d'altitude.

Pour consulter la vigilance en cours, veuillez vous rendre sur le site https://vigilance.meteofrance.fr/fr

Météo-France - 73 avenue de Paris, 94165 Saint-Mandé cedex - Contact : contact@meteo.fr

Rédigé par Météo-France avec la contribution des observateurs du réseau nivo-météorologiques. Partenariat : ANMSM (Maires de Stations de Montagne), DSF (Domaines Skiables de France), ADSP (Directeurs de Pistes et de la Sécurité des Stations de Sports d'Hiver) et autres acteurs de la montagne.

Bulletin neige & avalanches par téléphone au 0 892 68 10 20 Service 0,35 € / min + prix appel

RÉPUBLIQUE FRANÇAISE
Liberté Égalité Fraternité

METEO FRANCE
À VOS CÔTÉS, DANS UN CLIMAT QUI CHANGE

Bulletin d'estimation du risque d'avalanche

(valable en dehors des pistes balisées et ouvertes)

MASSIF : Haut-Var Haut-Verdon

Rédigé le mercredi 22 avril 2026 à 16h

Conditions nivo-météo des 7 derniers jours

	jeu. 16/04				ven. 17/04				sam. 18/04				dim. 19/04				lun. 20/04				mar. 21/04				mer. 22/04			
	03h	09h	15h	21h	03h	09h	15h	21h	03h	09h	15h	21h	03h	09h	15h	21h	03h	09h	15h	21h	03h	09h	15h	21h	03h	09h	15h	21h
Météo																												
Vent (km/h)	15	10	15	10	10	10	15	15	15	15	20	20	20	30	35	25	25	30	35	25	30	30	40	40	35	30	30	25
à 3000m																												
Vent (km/h)	10	10	20	5	5	10	20	10	10	10	20	10	15	20	30	20	20	20	30	20	20	20	30	15	15	20	25	10
à 2000m																												

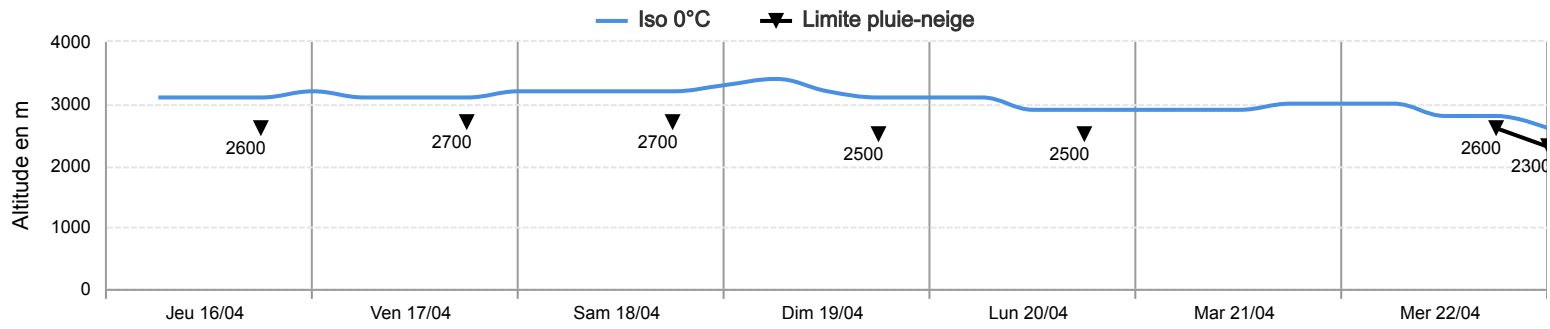

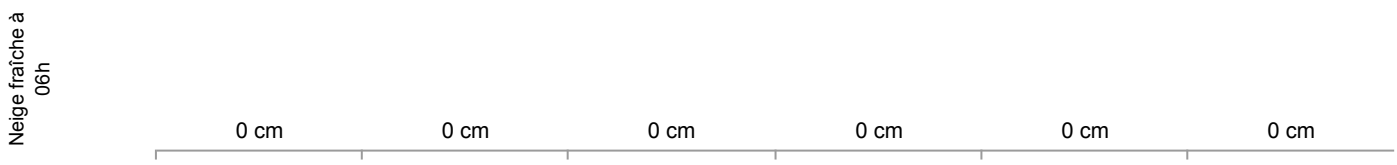

Risque d'avalanche	jeu. 16/04	ven. 17/04	sam. 18/04	dim. 19/04	lun. 20/04	mar. 21/04	mer. 22/04
	2	2	2	2	2	2	2

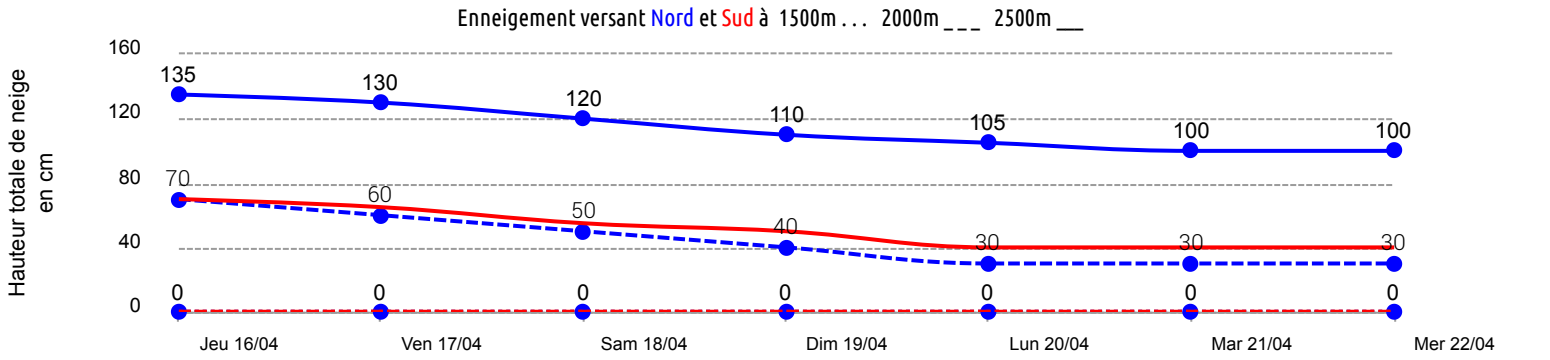

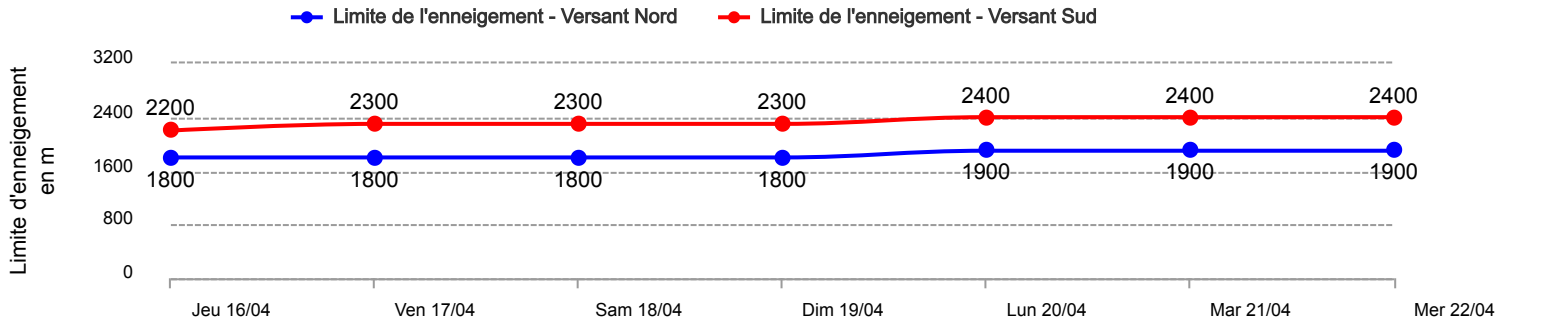

Pour consulter la vigilance en cours, veuillez vous rendre sur le site https://vigilance.meteofrance.fr/fr

Météo-France - 73 avenue de Paris, 94165 Saint-Mandé cedex - Contact : contact@meteo.fr

Bulletin neige & avalanches par téléphone au

0 892 68 10 20 Service 0,35 € / min + prix appel

Rédigé par Météo-France avec la contribution des observateurs du réseau nivo-météorologiques. Partenariat : ANMSM (Maires de Stations de Montagne), DSF (Domaines Skiables de France), ADSP (Directeurs de Pistes et de la Sécurité des Stations de Sports d'Hiver) et autres acteurs de la montagne.