# Bulletin d'estimation du risque d'avalanche
(valable en dehors des pistes balisées et ouvertes)

# MASSIF : Haute-Maurienne

Rédigé le mercredi 22 avril 2026 à 16h

## Estimation des risques pour le : JEUDI 23 AVRIL

**CONDITIONS DE PRINTEMPS AVANCÉES**

2

1 → 2

N O E S

Indice de risque faible évoluant en limité.

**Départs spontanés :** rares mais possiblement gros départs en neige humide.

**Déclenchements provoqués :** neige humide sous les skis.

Indices de risque : 5 très fort - 4 fort - 3 marqué - 2 limité - 1 faible -- En noir : les pentes les plus dangereuses

## Stabilité du manteau neigeux

**Situation avalancheuse typique :** neige humide

**Départs spontanés** :
- **Rares avalanches de neige humide** dans les **pentes ensoleillées** au fil de la journée. Les départs ponctuels (en poire) se font désormais petits et rares. Avec l'avancée dans la saison, les pentes Sud deviennent relativement inertes avec une neige transformée sur toute l'épaisseur du manteau jusqu'à haute altitude (type névé). Par contre, dans les versants Est, Nord et Ouest, l'humidification gagne des couches plus profondes. Ainsi, lorsqu'une couche fragile est atteinte, **un départ linéaire est possible**. On peut alors s'attendre à de **rares grandes avalanches (taille 3).**
- En plein Nord de haute altitude (sup ~3000 m), une très rare plaque en neige froide peut subsister. Une couche enfouie moins dense qu'en surface doit alerter.

**Déclenchements provoqués :** avalanche de neige humide (pourrie) sous les skis en coupant une pente trop humidifiée.

**Autres :** chutes de corniches signalées.

## Qualité de la neige

**Enneigement :** déficitaire pour la saison, la montagne subit les assauts répétés de la chaleur excessive et la neige fond à vue d'œil.

**Limite skiable :** vers 1600 m en Nord, 2000 m en Sud en pente douce, bien plus haut en pente sud raide.

**Qualité de la neige** : neige de printemps après un très bon regel nocturne. Neige dure aux premières heures du jour puis moquette aux bonnes heures (milieu de matinée à la mi journée suivant orientations et altitude). Comme les jours précédents, les pentes Est chauffent très vite le matin. Neige pourrie à partir de l'après midi. Neige froide souvent poudreuse au-dessus de 3000 m en plein Nord.

## Aperçu météo pour le jeudi 23 avril

| nuit | matin | après-midi | soir |
|---|---|---|---|

Grand beau, rares cumulus sur les sommets. Chaud.

| Pluie-Neige | | | | |
|---|---|---|---|---|
| Iso 0 °C | 2 500 m | 2 700 m | 3 000 m | 3 100 m |
| Vent 2500 m | 10 km/h | 15 km/h | 15 km/h | 10 km/h |
| Vent 3500 m | 15 km/h | 25 km/h | 25 km/h | 15 km/h |

## Épaisseur de neige hors-piste

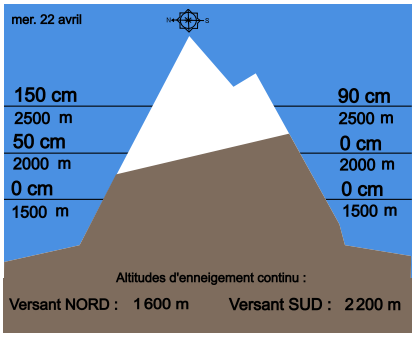


## Précipitations à 1800 m

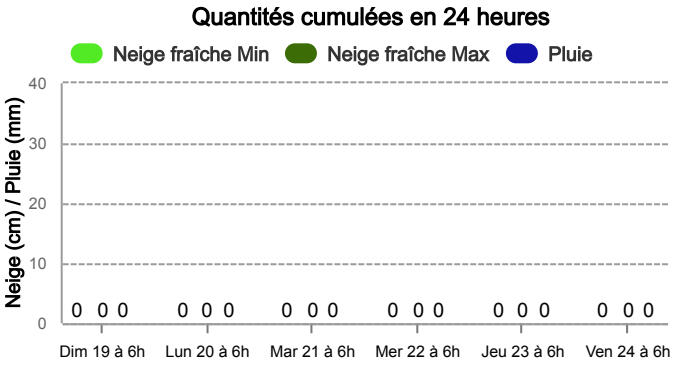


## Tendance du vendredi 24 avril

2

**Indice de risque limité**

Poursuite de conditions printanières, donc même schéma : risque croissant avec le réchauffement en journée.

Pour consulter la vigilance en cours, veuillez vous rendre sur le site https://vigilance.meteofrance.fr/fr

Météo-France - 73 avenue de Paris, 94165 Saint-Mandé cedex - Contact : contact@meteo.fr

Rédigé par Météo-France avec la contribution des observateurs du réseau nivo-météorologiques. Partenariat : ANMSM (Maires de Stations de Montagne), DSF (Domaines Skiables de France), ADSP (Directeurs de Pistes et de la Sécurité des Stations de Sports d'Hiver) et autres acteurs de la montagne.

Bulletin neige & avalanches par téléphone au 0 892 68 10 20 Service 0,35 € / min + prix appel

RÉPUBLIQUE FRANÇAISE
*Liberté Égalité Fraternité*

METEO FRANCE
À VOS CÔTÉS, DANS UN CLIMAT QUI CHANGE

# Bulletin d'estimation du risque d'avalanche

## (valable en dehors des pistes balisées et ouvertes)

# MASSIF : Haute-Maurienne

Rédigé le mercredi 22 avril 2026 à 16h

## Conditions nivo-météo des 7 derniers jours

| | jeu. 16/04 | | | | ven. 17/04 | | | | sam. 18/04 | | | | dim. 19/04 | | | | lun. 20/04 | | | | mar. 21/04 | | | | mer. 22/04 | | | |
|---|---|---|---|---|---|---|---|---|---|---|---|---|---|---|---|---|---|---|---|---|---|---|---|---|---|---|---|---|
| | 03h | 09h | 15h | 21h | 03h | 09h | 15h | 21h | 03h | 09h | 15h | 21h | 03h | 09h | 15h | 21h | 03h | 09h | 15h | 21h | 03h | 09h | 15h | 21h | 03h | 09h | 15h | 21h |
| Météo | | | | | | | | | | | | | | | | | | | | | | | | | | | | |
| Vent (km/h) | 15 | 15 | 15 | 10 | 10 | 15 | 15 | 15 | 20 | 15 | 15 | 15 | 20 | 30 | 30 | 25 | 25 | 40 | 40 | 40 | 40 | 30 | 35 | 30 | 35 | 35 | 20 | 15 |
| à 3500m | | | | | | | | | | | | | | | | | | | | | | | | | | | | |
| Vent (km/h) | 10 | 10 | 10 | 5 | 5 | 10 | 10 | 10 | 15 | 10 | 10 | 10 | 15 | 20 | 25 | 20 | 20 | 25 | 20 | 25 | 20 | 20 | 20 | 15 | 20 | 25 | 15 | 10 |
| à 2500m | | | | | | | | | | | | | | | | | | | | | | | | | | | | |

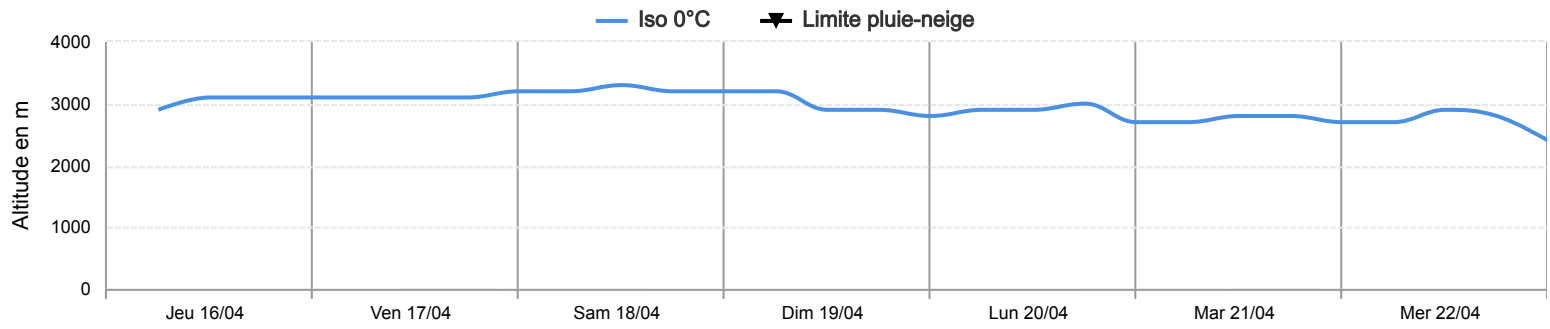


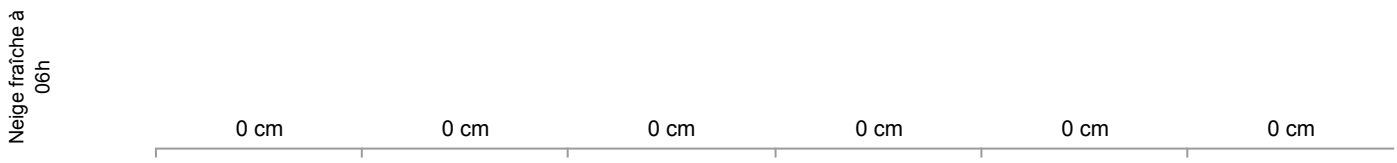


| Risque d'avalanche | jeu. 16/04 | ven. 17/04 | sam. 18/04 | dim. 19/04 | lun. 20/04 | mar. 21/04 | mer. 22/04 |
|---|---|---|---|---|---|---|---|
| | 2 | 2 | 2 | 2 | 2 | 2 | 2 |

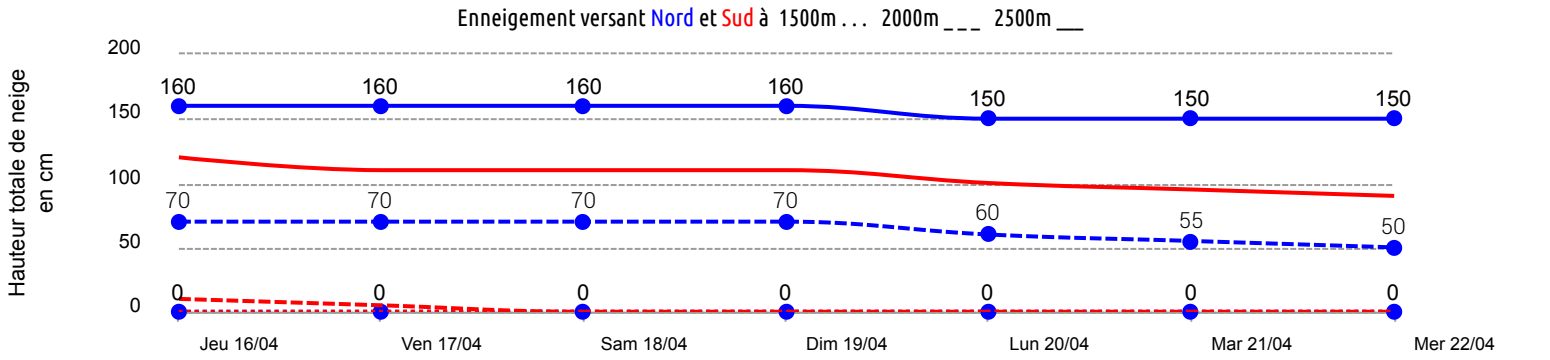


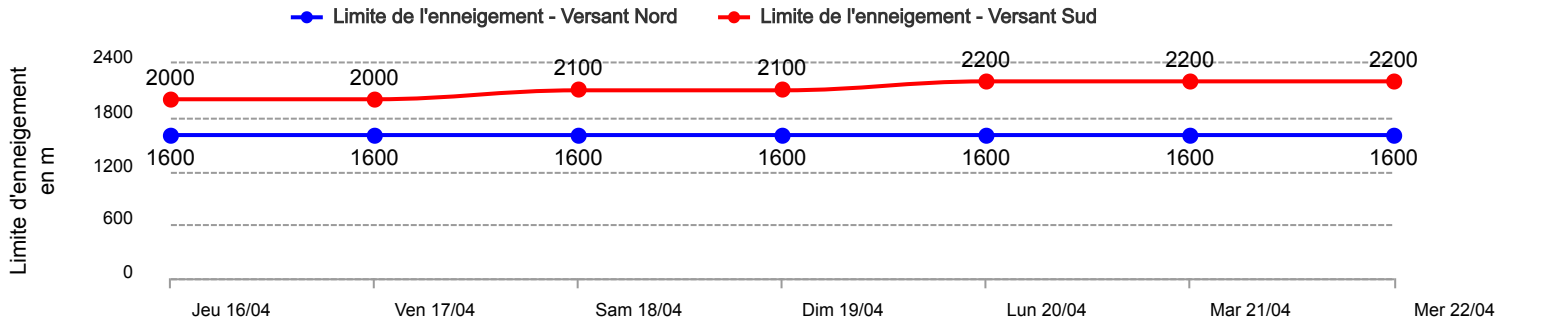


Pour consulter la vigilance en cours, veuillez vous rendre sur le site https://vigilance.meteofrance.fr/fr


**Météo-France - 73 avenue de Paris, 94165 Saint-Mandé cedex - Contact : contact@meteo.fr**



Rédigé par Météo-France avec la contribution des observateurs du réseau nivo-météorologiques. Partenariat : ANMSM (Maires de Stations de Montagne), DSF (Domaines Skiables de France), ADSP (Directeurs de Pistes et de la Sécurité des Stations de Sports d'Hiver) et autres acteurs de la montagne.



Bulletin neige & avalanches par téléphone au
**0 892 68 10 20** Service 0,35 € / min + prix appel