Bulletin d'estimation du risque d'avalanche
(valable en dehors des pistes balisées et ouvertes)

MASSIF : Luchonnais

Rédigé le mercredi 22 avril 2026 à 16h

Estimation des risques pour le : JEUDI 23 AVRIL

PEU DE REGEL, ACTIVITÉ POSSIBLE DÈS LE MATIN, GRANDES AVALANCHES POSSIBLES

3

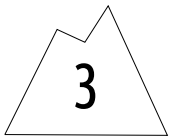

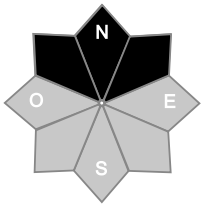

Rares mais grandes

Indice de risque marqué.

Départs spontanés : En neige humide, grandes à très grandes rares mais possibles

Déclenchements provoqués : En neige humide sous les skis

Indices de risque : 5 très fort - 4 fort - 3 marqué - 2 limité - 1 faible -- En noir : les pentes les plus dangereuses

Stabilité du manteau neigeux

Situation avalancheuse typique : neige humide avalanches de fond

Départs spontanés :
Avec un manteau intégralement humidifié, regelant à peine en surface, des départs ponctuels de taille petite à moyenne sont déjà attendus le matin et deviennent nombreux au cours de la journée. Des avalanches de fond sont aussi possibles, à tout moment, partant en général d'une des nombreuses fissures déjà ouvertes. Elles restent rares, mais peuvent atteindre une grande voire très grande taille, les fissures ouvertes dépassant le mètre d'épaisseur, en particulier en expositions nord-ouest à nord-est. Dans les autres expositions, les accumulations sont moindres et le manteau est plus tassé, moins instable.
Les zones de départ se situent plutôt au sud du Luchonnais, au-dessus de 2000m mais ces avalanches de fond peuvent parcourir des dénivelés importants et atteindre des sentiers à des altitudes inférieures à la limite d'enneigement dans les couloirs d'avalanche habituels.

Déclenchements provoqués :
Le passage d'un skieur ou randonneur dans une pente en neige très humide peut favoriser un départ ponctuel de taille petite à moyenne, en particulier en expositions nord moins stabilisées par tassement.

Autres : corniches et ponts de neige encore en place extrêmement peu résistants, pouvant céder dès le matin sous le poids d'une seule personne.

Qualité de la neige

Enneigement : plutôt bon pour la saison et débutant encore vers 1700m en nord, 2000m en sud.
Les limites de cet enneigement remontent progressivement dans la douceur ambiante, sous les éclaircies matinales et les quelques averses de l'après-midi.
État de la neige : Le manteau neigeux subit la longue période de douceur. En expositions ensoleillées, et sur la neige ocre, le manteau est printanier à tous niveaux, sans regel mais assez portant. En expositions nord, plutôt au-dessus de 2300m, une petite croûte est présente au petit matin, mais disparaît rapidement. Les enfoncements y deviennent alors importants, dans une neige sans consistance.

Aperçu météo pour le jeudi 23 avril

	nuit	matin	après-midi	soir

Matinée ensoleillée, après-midi plus nuageuse, finissant par quelques averses orageuses.

Pluie-Neige				
Iso 0 °C	3 300 m	3 200 m	3 200 m	3 400 m
Vent 2000 m	↑ 15 km/h	↑ 15 km/h	↑ 20 km/h	↑ 10 km/h
Vent 3000 m	↗ 35 km/h	↗ 20 km/h	↗ 30 km/h	↘ 15 km/h

Épaisseur de neige hors-piste

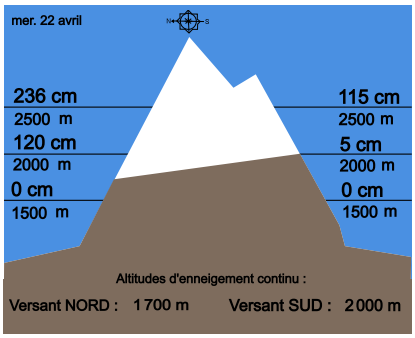

Précipitations à 1800 m

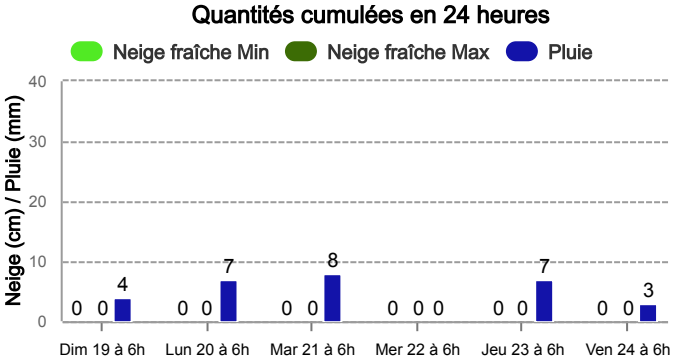

Tendance du vendredi 24 avril

3

Indice de risque marqué

Peu d'évolution avec la douceur persistante

Pour consulter la vigilance en cours, veuillez vous rendre sur le site https://vigilance.meteofrance.fr/fr

Météo-France - 73 avenue de Paris, 94165 Saint-Mandé cedex - Contact : contact@meteo.fr

Rédigé par Météo-France avec la contribution des observateurs du réseau nivo-météorologiques. Partenariat : ANMSM (Maires de Stations de Montagne), DSF (Domaines Skiables de France), ADSP (Directeurs de Pistes et de la Sécurité des Stations de Sports d'Hiver) et autres acteurs de la montagne.

Bulletin neige & avalanches par téléphone au
0 892 68 10 20 Service 0,35 € / min + prix appel

RÉPUBLIQUE FRANÇAISE
Liberté Égalité Fraternité

METEO FRANCE
À VOS CÔTÉS, DANS UN CLIMAT QUI CHANGE

Bulletin d'estimation du risque d'avalanche

(valable en dehors des pistes balisées et ouvertes)

MASSIF : Luchonnais

Rédigé le mercredi 22 avril 2026 à 16h

Conditions nivo-météo des 7 derniers jours

	jeu. 16/04				ven. 17/04				sam. 18/04				dim. 19/04				lun. 20/04				mar. 21/04				mer. 22/04			
	03h	09h	15h	21h	03h	09h	15h	21h	03h	09h	15h	21h	03h	09h	15h	21h	03h	09h	15h	21h	03h	09h	15h	21h	03h	09h	15h	21h
Météo																												
Vent (km/h)	20	15	15	20	20	15	10	10	10	10	25	20	20	20	30	25	25	20	55	25	20	25	30	45	35	40	25	30
à 3000m																												
Vent (km/h)	5	5	5	5	5	5	5	5	5	5	15	10	15	15	20	10	5	10	15	5	5	10	10	15	35	25	20	10
à 2000m																												

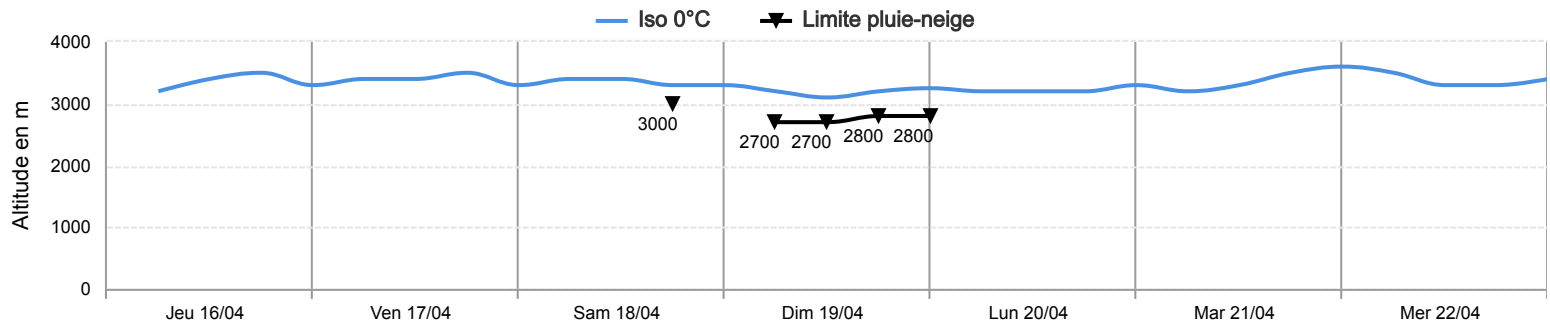

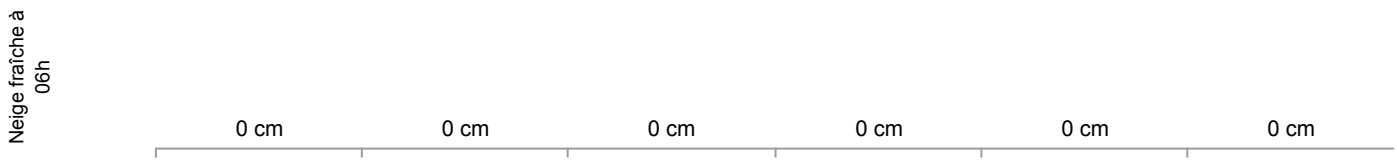

Risque d'avalanche	jeu. 16/04	ven. 17/04	sam. 18/04	dim. 19/04	lun. 20/04	mar. 21/04	mer. 22/04
	2	2	2	2	2	2	3

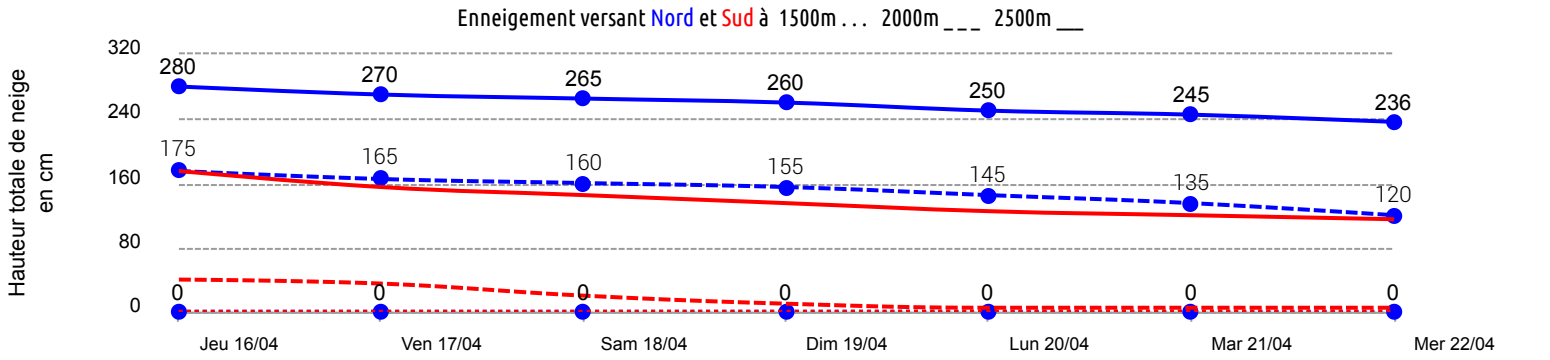

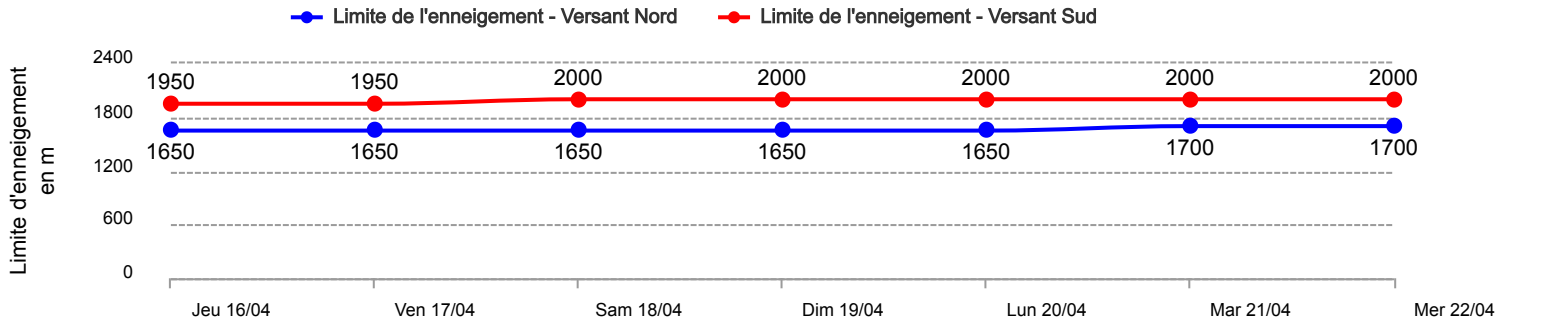

Pour consulter la vigilance en cours, veuillez vous rendre sur le site https://vigilance.meteofrance.fr/fr

Météo-France - 73 avenue de Paris, 94165 Saint-Mandé cedex - Contact : contact@meteo.fr

Bulletin neige & avalanches par téléphone au

0 892 68 10 20 Service 0,35 € / min + prix appel

Rédigé par Météo-France avec la contribution des observateurs du réseau nivo-météorologiques. Partenariat : ANMSM (Maires de Stations de Montagne), DSF (Domaines Skiables de France), ADSP (Directeurs de Pistes et de la Sécurité des Stations de Sports d'Hiver) et autres acteurs de la montagne.