# Bulletin d'estimation du risque d'avalanche

(valable en dehors des pistes balisées et ouvertes)

# MASSIF : Cinto Rotondo

Rédigé le mercredi 22 avril 2026 à 17h

## Estimation des risques pour le : JEUDI 23 AVRIL

**MANTEAU NEIGEUX PRINTANIER**

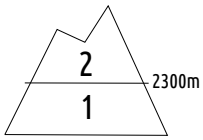


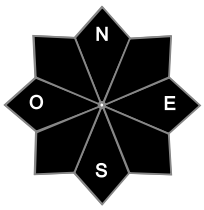


Au-dessus de 2300m indice de risque limité, plus bas indice faible.

**Départs spontanés :** Coulées et avalanches de neige humide dans les pentes raides, ce mercredi soir puis jeudi en journée

**Déclenchements provoqués :** Peu probables

Indices de risque : 5 très fort - 4 fort - 3 marqué - 2 limité - 1 faible -- En noir : les pentes les plus dangereuses

## Stabilité du manteau neigeux

**Situation avalancheuse typique :** neige humide

**Départs spontanés :** Le manteau neigeux est bien humidifié et bien tassé jusqu'à 2300 m d'altitude. Ce mercredi soir sous la pluie, ou jeudi en journée sous l'effet de la douceur et de l'ensoleillement, des coulées ou avalanches de neige humide sont attendues dans les pentes raides. Elles peuvent être de taille moyenne au-dessus de 2300 m, notamment dans les pentes orientées Nord. À noter également qu'une avalanche de fond n'est pas exclue sur les dalles rocheuses.

**Déclenchements provoqués** : Dans la plupart des secteurs, il est difficile de provoquer une avalanche dans ce manteau neigeux humide et tassé. Un skieur peut éventuellement favoriser un départ ponctuel en coupant une pente raide en neige très humide.

**Autres :** Prendre garde également aux effondrements de corniches et ponts de neige qui peuvent céder.

## Qualité de la neige

**Qualification de l'enneigement :** La fonte est importante depuis début avril. Malgré tout, l'enneigement est encore bon pour la saison. Sur la Maniccia, à 2400 m d'altitude dans le massif du Rotondo, on relève près de 2m50 de hauteur de neige totale.

**Limite d'enneigement skiable :** vers 1600 à 1700 m en Nord, 1800 à 1900 m en Sud, mais cette limite progresse chaque jour avec la fonte.

**État de la neige :** Faible regel en altitude. Neige dense et portante le matin au plus haut du massif, parfois croûtée, devenant vite printanière, très humide. Sans regel, la neige reste plus lourde voire pourrie en dessous de 2000 m. La surface du manteau est majoritairement constituée de neige colorée, chargée en poussières sahariennes. Les cols et crêtes ouest se dégarnissent en neige ou sont parfois "pelés". Nombreuses fissures en place.

## Aperçu météo pour le jeudi 23 avril

| nuit | matin | après-midi | soir |
|---|---|---|---|

Faibles précipitations ce mercredi soir, limite pluie-neige vers 2400 à 2500 m.

| Pluie-Neige | | | | |
|---|---|---|---|---|
| Iso 0 °C | 2 300 m | 2 100 m | 2 400 m | 2 900 m |
| Vent 1500 m | 30 km/h | 40 km/h | 25 km/h | 20 km/h |
| Vent 3000 m | 30 km/h | 30 km/h | 40 km/h | 40 km/h |

## Épaisseur de neige hors-piste

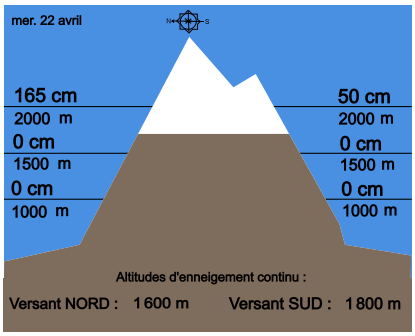


## Précipitations à 1800 m

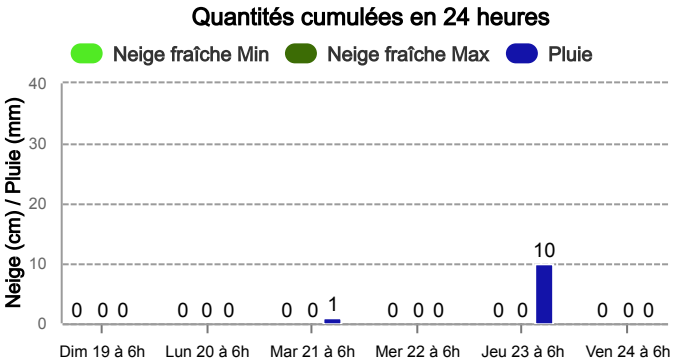


## Tendance du vendredi 24 avril

**Indice de risque limité**

Tendance stationnaire ou en légère baisse.

Pour consulter la vigilance en cours, veuillez vous rendre sur le site https://vigilance.meteofrance.fr/fr

Météo-France - 73 avenue de Paris, 94165 Saint-Mandé cedex - Contact : contact@meteo.fr

Rédigé par Météo-France avec la contribution des observateurs du réseau nivo-météorologiques. Partenariat : ANMSM (Maires de Stations de Montagne), DSF (Domaines Skiables de France), ADSP (Directeurs de Pistes et de la Sécurité des Stations de Sports d'Hiver) et autres acteurs de la montagne.

Bulletin neige & avalanches par téléphone au 0 892 68 10 20 Service 0,35 € / min + prix appel

# Bulletin d'estimation du risque d'avalanche

(valable en dehors des pistes balisées et ouvertes)

# MASSIF : Cinto Rotondo

Rédigé le mercredi 22 avril 2026 à 17h

## Conditions nivo-météo des 7 derniers jours

| | jeu. 16/04 | | | | ven. 17/04 | | | | sam. 18/04 | | | | dim. 19/04 | | | | lun. 20/04 | | | | mar. 21/04 | | | | mer. 22/04 | | | |
|---|---|---|---|---|---|---|---|---|---|---|---|---|---|---|---|---|---|---|---|---|---|---|---|---|---|---|---|---|
| | 03h | 09h | 15h | 21h | 03h | 09h | 15h | 21h | 03h | 09h | 15h | 21h | 03h | 09h | 15h | 21h | 03h | 09h | 15h | 21h | 03h | 09h | 15h | 21h | 03h | 09h | 15h | 21h |
| Météo | | | | | | | | | | | | | | | | | | | | | | | | | | | | |
| Vent (km/h) | 30 | 20 | 20 | 20 | 20 | 15 | 15 | 20 | 15 | 15 | 15 | 20 | 10 | 20 | 30 | 30 | 35 | 45 | 60 | 60 | 50 | 40 | 55 | 50 | 55 | 55 | 50 | 30 |
| à 3000m | | | | | | | | | | | | | | | | | | | | | | | | | | | | |
| Vent (km/h) | 20 | 15 | 10 | 20 | 15 | 15 | 10 | 15 | 10 | 15 | 10 | 5 | 5 | 20 | 30 | 25 | 25 | 30 | 35 | 35 | 25 | 30 | 30 | 15 | 15 | 15 | 10 | 20 |
| à 1500m | | | | | | | | | | | | | | | | | | | | | | | | | | | | |

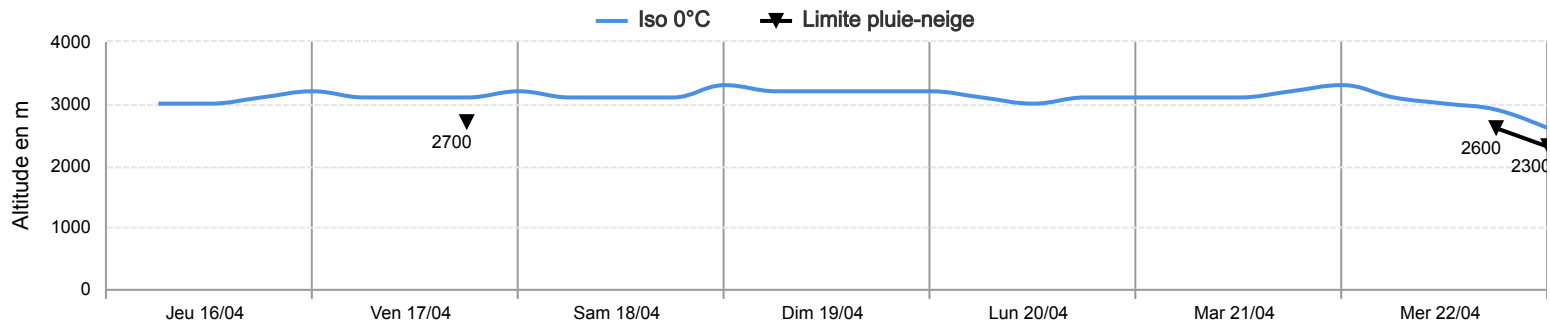


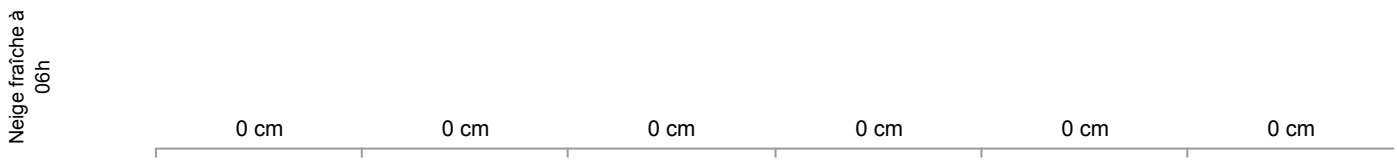


| Risque d'avalanche | jeu. 16/04 | ven. 17/04 | sam. 18/04 | dim. 19/04 | lun. 20/04 | mar. 21/04 | mer. 22/04 |
|---|---|---|---|---|---|---|---|
| | 2 | 2 | 2 | 2 | 2 | 2 | 2 |

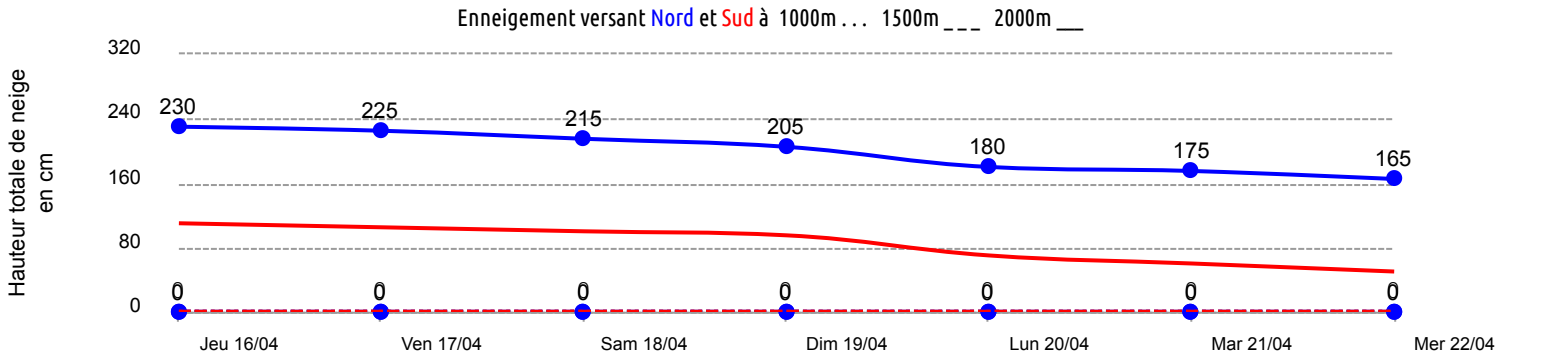


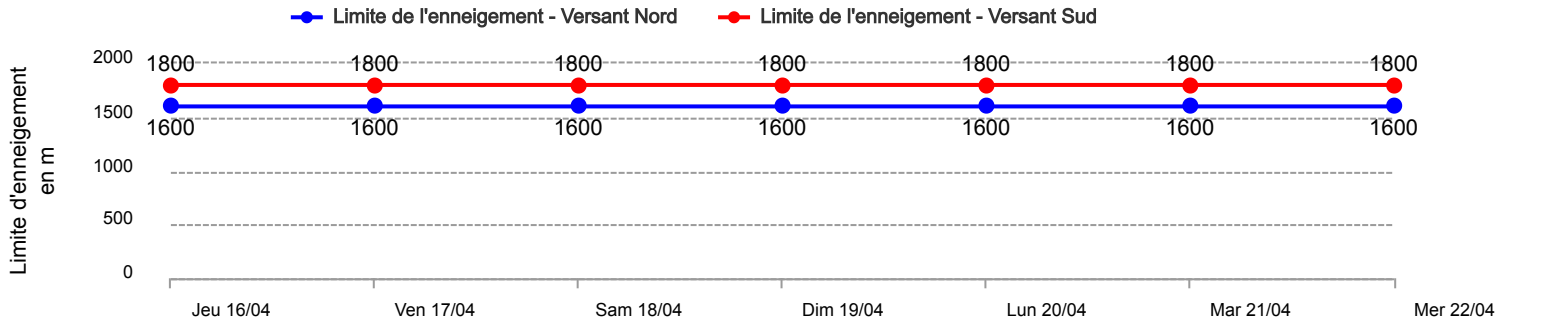


Pour consulter la vigilance en cours, veuillez vous rendre sur le site https://vigilance.meteofrance.fr/fr


Météo-France - 73 avenue de Paris, 94165 Saint-Mandé cedex - Contact : contact@meteo.fr


Bulletin neige & avalanches par téléphone au

0 892 68 10 20 Service 0,35 € / min + prix appel


Rédigé par Météo-France avec la contribution des observateurs du réseau nivo-météorologiques. Partenariat : ANMSM (Maires de Stations de Montagne), DSF (Domaines Skiables de France), ADSP (Directeurs de Pistes et de la Sécurité des Stations de Sports d'Hiver) et autres acteurs de la montagne.