GOBIERNO DE ESPAÑA
VICEPRESIDENCIA TERCERA DEL GOBIERNO
MINISTERIO PARA LA TRANSICIÓN ECOLÓGICA Y EL RETO DEMOGRÁFICO

Boletín de información nivológica y de peligro de aludes

Pirineo Navarro y Aragonés

aemet Agencia Estatal de Meteorología

jueves, 23 de abril de 2026

Pronóstico hasta las 24 horas del viernes, día 24 de abril

(Válido fuera de pistas de esquí balizadas y abiertas)

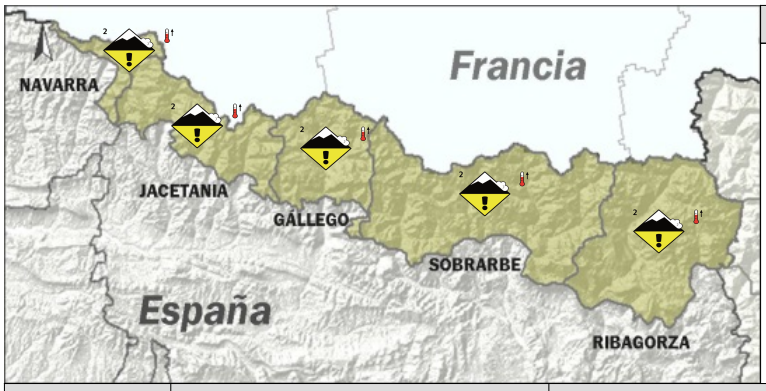

Problemas de aludes

Nieve húmeda

Deslizamientos basales

Macizo	Peligro	Problemas de aludes, cota, orientación, tamaño	Innivación observada (m)
Navarra	2 — 2 — Limitado	Nieve húmeda: 2 — N, O, E, S — 2 Deslizamientos basales: 2 — N, O, E, S — 2	2026-04-23 N / S Cota más baja caras N
Jacetania	2 — 2 — Limitado	Nieve húmeda: 2 — N, O, E, S — 2 Deslizamientos basales: 2 — N, O, E, S — 2	2026-04-23 N / S Cota más baja caras N
Gállego	2 — 2 — Limitado	Nieve húmeda: 2 — N, O, E, S — 2 Deslizamientos basales: 2 — N, O, E, S — 2	2026-04-23 N / S Cota más baja caras N

AEMET. Se autoriza la reproducción de su contenido citando la fuente.

Boletín de información nivológica y de peligro de aludes

Pirineo Navarro y Aragonés

Sobrarbe	2 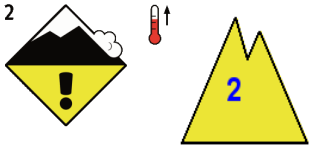 **Limitado**	**Nieve húmeda** 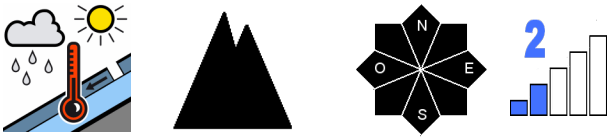 **Deslizamientos basales** 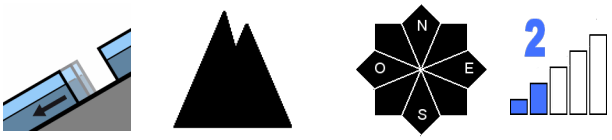	2026-04-23 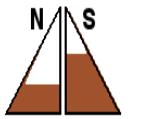 Cota más baja caras N
Ribagorza	2 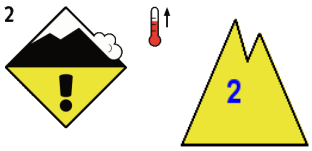 **Limitado**	**Nieve húmeda** **Deslizamientos basales** 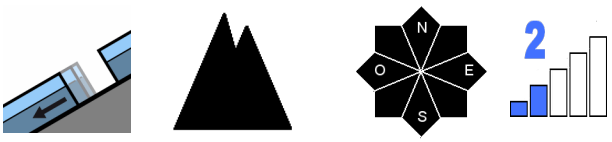	2026-04-23 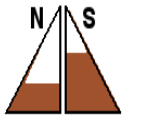 Cota más baja caras N

Estado del manto y observaciones recientes

Continúa el proceso de fusión y humidificación como consecuencia de las altas temperaturas, la insolación y los chubascos que se van produciendo cada tarde, en forma de lluvia hasta altitudes de unos 2800 metros, con menguas de varios cm al día en los diferentes puntos de observación. El manto es más o menos continuo a partir de unos 1900-2000 metros en umbrías y 2200-2300 metros en solanas aproximadamente, aunque los afloramientos rocosos y las calvas son cada vez más extensas. En la red de observación, a 2200 metros hay espesores en solanas que rondan los 20cm y, en umbrías, aún se puede superar el metro de nieve, aún más en ventisqueros y otras áreas propensas a la acumulación. La nieve es típicamente primaveral, muy humedecida y con predominio de grano redondo, con rehielo nocturno débil, poco efectivo y prácticamente restringido a la alta montaña.

Evolución del manto y peligro de aludes para el viernes, día 24

Problema de nieve húmeda. Problema de deslizamientos basales.

Seguirá el ambiente cálido y la previsión de chubascos durante la segunda mitad del día, que continuarán propiciando la fusión y la humidificación del manto. Además, el rehielo nocturno estará generalmente restringido a las zonas de mayor altitud de la cordillera. En consecuencia, desde media mañana se pueden producir purgas de nieve húmeda en laderas de cualquier orientación, con preferencia en las solanas y áreas afectadas por la lluvia, que podrán ser de tamaño pequeño (riesgo de caída) o localmente mediano (capaz de enterrar a una persona). También podrán darse algunos aludes de deslizamiento basal en laderas herbosas o de roca lisa con la suficiente inclinación, normalmente de tamaño mediano, aunque podrían adquirir dimensiones incluso grandes, magnitud suficiente como para arrastrar a un grupo de personas.

AEMET. Se autoriza la reproducción de su contenido citando la fuente.

Predicción meteorológica para el viernes, día 24

Intervalos nubosos, con nubes altas, bajas y, sobre todo por la tarde, de evolución diurna. Probables chubascos dispersos y ocasionales durante la segunda mitad del día, con cota de nieve en torno a 2800 metros. Las tormentas podrán acompañar ocasionalmente a los chubascos. Temperaturas mínimas en ligero descenso. Temperaturas máximas en ligero o moderado ascenso. Alguna helada débil en la alta montaña. Soplarán vientos generalmente flojos de componente sur.

Datos en la atmósfera libre:

Altitud de la isoterma de 0 ºC: 3300 m
Altitud de la isoterma de -10 ºC: 4900 m

Viento a 1500 m: S 10 km/h
Viento a 3000 m: SE 20 km/h

Evolución para el sábado día 25

Con pocos cambios.

(Información elaborada a partir de los datos recibidos de los refugios de Linza, Lizara, Respomuso, Panticosa, Bachimaña, Pineta, Estós y Angel Orús y de las estaciones de esquí de Astún, Formigal y Panticosa (lagos))

Escala europea de peligro de aludes

Débil Limitado Notable Fuerte Muy Fuerte

Problemas de aludes

Nieve reciente Placas de viento Capas débiles persistentes Nieve húmeda Deslizamientos basales Sin problema evidente

Nota1: Se recuerda que, siempre que haya nieve, la ausencia total de peligro no existe. Hay que tener presente que en circunstancias desfavorables, con aludes de tamaño 1 (alud pequeño o colada) y tamaño 2 (alud mediano), se pueden sufrir severos daños personales.

Nota2: Los BPA se elaboran en base a información meteorológica así como al estado del manto nivoso a través de sondeos puntuales. Se advierte a los usuarios de la variabilidad de esta información al extrapolarla a zonas extensas de montaña. Por ello, AEMET no se hace responsable de su uso para la toma de decisiones que conciernen a la seguridad personal, ni de los riesgos físicos o materiales de ellas derivadas.

AEMET. Se autoriza la reproducción de su contenido citando la fuente.