# BUTLLETÍ DEL PERILL D'ALLAUS DEL PRINCIPAT D'ANDORRA

Préparé le 23/04/2026 16:00
Prochaine mise à jour le 24/04/2026 à 16h

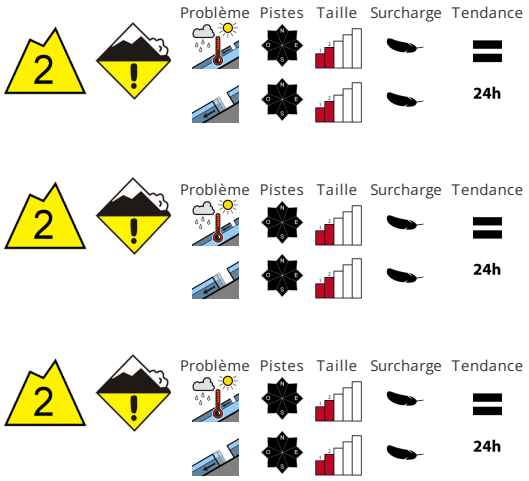


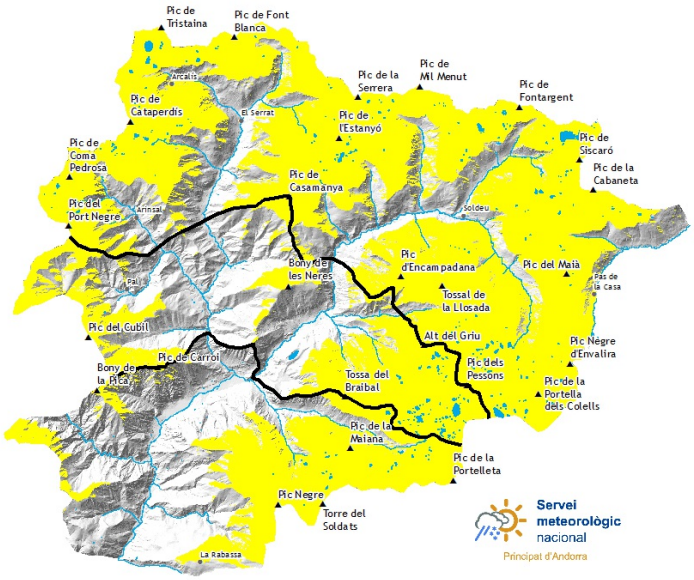


## STABILITÉ DU MANTEAU NEIGEUX

Le matin il fait doux. À partir de midi il tombera de la pluie jusqu'à haute altitude. Des avalanches humides et mouillées de moyenne et rarement grande taille sont ils sont possibles avec l'humidification. Prudence en présence de fissures de glissement.. Elles peuvent se déclencher à tout moment du jour et de la nuit. À toutes les expositions le danger d'avalanches mouillées et de glissement augmente au sein du degré de danger en cours de journée au grade 1 (faible). Des avalanches récentes et les observations sur le terrain confirment cette situation.

## QUALITÈ DE LA NEIGE

Le rayonnement nocturne est généralement réduit.. Les conditions météorologiques entraînent le matin une humidification croissante du manteau neigeux. La pluie entraîne à partir de midi partiellement une perte de solidité au sein du manteau neigeux. Les zones présentant des fissures de glissement doivent être évitées.. Les randonnées devraient être commencées et terminées très tôt..

## EPAISSEUR DE NEIGE HORS PISTE

| Zone nord | | Epaisseur de neige | | |
|---|---|---|---|---|
| **Nival manteau** | | 1500m | 2000m | 2500m |
| N | 1800 m | 0 cm | 150 cm | 250 cm |
| S | 2200 m | 0 cm | 0 cm | 180 cm |

| Zone centre | | Epaisseur de neige | | |
|---|---|---|---|---|
| **Nival manteau** | | 1500m | 2000m | 2500m |
| N | 1800 m | 0 cm | 120 cm | 160 cm |
| S | 2200 m | 0 cm | 0 cm | 120 cm |

| Zone sud | | Epaisseur de neige | | |
|---|---|---|---|---|
| **Nival manteau** | | 1500m | 2000m | 2500m |
| N | 1800 m | 0 cm | 120 cm | 160 cm |
| S | 2200 m | 0 cm | 0 cm | 120 cm |

Govern d'Andorra

EAWS EUROPEAN AVALANCHE WARNING SERVICES

Aquest butlletí ha estat elaborat seguint les normes i recomanacions de l'**European Avalanche Warning Services**, del qual el **Servei meteorològic Nacional** n'és membre

# BUTLLETÍ DEL PERILL D'ALLAUS DEL PRINCIPAT D'ANDORRA

Servei meteorològic nacional
Principat d'Andorra

## Des informations détaillées par espace naturel protégé

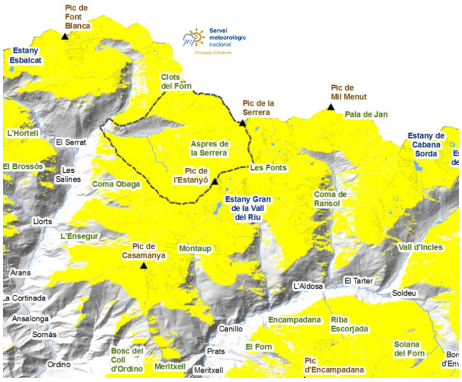


### SORTENY

Les faibles gelées des dernières nuits et les pluies de l'après-midi ont laissé un manteau neigeux plus précaire que la semaine dernière. La glace n'est pas aussi bonne ni efficace, il est donc plus difficile de circuler dans la neige qui n'a pas été compactée tout au long de la saison. , , ,

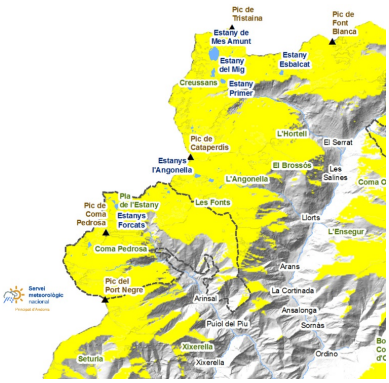


### COMAPEDROSA

La neige est plus humide que la semaine dernière. Faites attention aux ponts de glace au-dessus des torrents, car ils seront fragilisés par l'augmentation des températures et l'augmentation du débit des rivières. , , ,

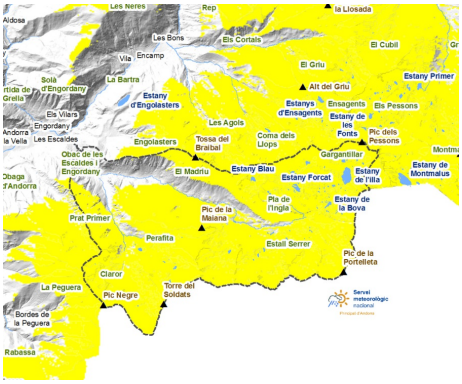


### MADRIU-PERAFITA-CLAROR

La pénétration de l'humidité favorisera un cycle d'avalanches naturelles de neige mouillée et de glissements basaux. Depuis l'Estall Serrer en aval, il ne reste plus de neige continue. , , ,

Govern d'Andorra

EAWS
EUROPEAN AVALANCHE WARNING SERVICES

Aquest butlletí ha estat elaborat seguint les normes i recomanacions de l'**European Avalanche Warning Services**, del qual el **Servei meteorològic Nacional** n'és membre

# BUTLLETÍ DEL PERILL D'ALLAUS DEL PRINCIPAT D'ANDORRA

Servei meteorològic nacional
Principat d'Andorra

## Couche de neige fraiche des derniers jours (De 24 h mesurée à 06:00 h UTC)

| | 19/04/2026 | 20/04/2026 | 21/04/2026 | 22/04/2026 |
|---|---|---|---|---|
| **FEDA (Central)** | 0 cm | 0 cm | 0 cm | 0 cm |
| **Aixàs** | 0 cm | 0 cm | 0 cm | 0 cm |
| **Engolasters - FEDA** | 0 cm | 0 cm | 0 cm | 0 cm |
| **Ransol - FEDA** | 0 cm | 0 cm | 0 cm | 0 cm |
| **Fontverd** | 0 cm | 0 cm | 0 cm | 0 cm |
| **Setúria** | 0 cm | 0 cm | 0 cm | 0 cm |
| **Coll Ordino** | 0 cm | 0 cm | 0 cm | 0 cm |
| **Bony de les Neres** | 0 cm | 0 cm | 0 cm | 0 cm |
| **Grau Roig - FEDA** | 0 cm | 0 cm | 0 cm | 0 cm |
| **Caborreu** | 0 cm | 0 cm | 0 cm | 4 cm |
| **Sorteny** | 0 cm | 0 cm | 0 cm | 0 cm |
| **Coll Pa** | 0 cm | 0 cm | 0 cm | 0 cm |
| **Perafita** | 0 cm | 0 cm | 0 cm | 0 cm |
| **Tossa Espiolets** | 0 cm | 0 cm | 0 cm | 0 cm |
| **La Solana** | 0 cm | 0 cm | 0 cm | 0 cm |
| **Vall del Riu FEDA** | 0 cm | 0 cm | 0 cm | 0 cm |
| **Envalira Antenes** | 0 cm | 0 cm | 0 cm | 0 cm |
| **Les Fonts d'Arinsal** | 0 cm | 0 cm | 0 cm | 0 cm |