GRAN SASSO EST - LAGA EST

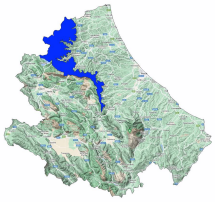

Bollettino Valanghe N. 401/2026 del 22/04/2026 ore 14.00
Validità 48 ore prossima emissione 23/04/2026

A cura del Servizio METEOMONT dell'ARMA dei CARABINIERI
In collaborazione con Servizio Meteorologico dell'Aeronautica militare

SITUAZIONE alle 14:00 del 22/04/2026

SITUAZIONE TIPO: situazione primaverile.

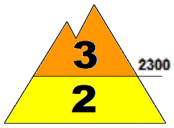



SITUAZIONE TIPO: pioggia su neve.

Quota neve (mslm)	Nord	Sud
	1600	1700 - 1900

Altezza Neve (cm)	Neve al suolo	Neve Fresca	Quota (mslm)
	000	000	1380
	000	000	1355

VALANGHE OSSERVATE: Nessuna valanga.

PREVISIONI 23/04/2026

GRADO DI PERICOLO: MODERATO 2

SITUAZIONE TIPO: situazione primaverile.

MANTO NEVOSO: La stabilità del manto nevoso è scarsa su pochi punti (aree) per tutte le esposizioni, possibili valanghe di dimensioni grandi.

AVVERTENZE

Il rialzo termico diurno richiede un'attenta valutazione temporale dell'escursione che eviti l'attraversamento di pendii ripidi nelle ore più calde della giornata.

SCALA EUROPEA DEL GRADO DI PERICOLO VALANGHE

LEGENDA PROBLEMA

Bollettino realizzato su scala sinottica-regionale (standard EAWS). La sua valutazione non può escludere in alcun modo la necessità di una seria e capace valutazione locale del pericolo (singolo pendio) che può essere anche sensibilmente diverso. Le previsioni meteorologiche sono relative all'orario UTC (per l'Italia +1 in inverno e +2 in estate).

MINISTERO DELLA DIFESA

meteomont
Servizio Nazionale di previsione neve e valanghe

EAWS EUROPEAN AVALANCHE WARNING SERVICES

CARABINIERI

AERONAUTICA MILITARE SERVIZIO METEOROLOGICO

GRAN SASSO EST - LAGA EST

PREVISIONE METEO

Quota		23/04/2026 h6:00	23/04/2026 h12:00	23/04/2026 h18:00
1000	Venti	04 Nodi da N-Est	05 Nodi da N-Est	04 Nodi da N-Est
	Temperature	+01 °C	+05 °C	+03 °C
	Temp.percepita	-1 °C	3 °C	1 °C
2000	Venti	10 Nodi da Est	09 Nodi da N-Est	11 Nodi da N-Est
	Temperature	-03 °C	-01 °C	+02 °C
	Temp.percepita	-9 °C	-6 °C	-3 °C
3000	Venti	13 Nodi da N-Est	14 Nodi da N-Est	14 Nodi da N-Est
	Temperature	-06 °C	-05 °C	-01 °C
	Temp.percepita	-13 °C	-12 °C	-7 °C
Zero termico		1500-1700 m.	1800-2000 m.	2700-2900 m.
Fenomeno		—	—	—
Stato del cielo				

LEGENDA FENOMENI

— Assenza Fenomeni · Nebbia · Foschia · Pioggia debole · Pioggia moderata · Pioggia forte · Temporali

Nevicata debole · Nevicata moderata · Nevicata forte

STATO DEL CIELO

Sereno · Poco nuvoloso · Nuvoloso · Molto nuvoloso · Coperto

Parametri meteonivometrici registrati presso i campi di rilevamento il 22/04/2026.

Località	Comune	Quota (m.s.l.m.)	Altezza neve (cm)	Neve caduta nelle 24 ore (cm)	Temp. Min (°C)	Temp. Max (°C)	Condizioni del tempo
FAVACCHIOLE	Crognaleto (TE)	1016	0	0	+6	+15	Pioggia debole intermittente
PRATO SELVA	Fano Adriano (TE)	1355	0	0	+4	+13	Pioggia moderata
PIANO SAN PIETRO	Isola del Gran Sasso d'Italia (TE)	950	0	0	N.P.	N.P.	Pioggia moderata
PRATI DI TIVO	Pietracamela (TE)	1380	0	0	+3	+13	Pioggia debole continua
CEPPO	Rocca Santa Maria (TE)	1349	0	0	+4	+10	Pioggia debole intermittente
SAN PAOLO	Acquasanta Terme (AP)	960	0	0	+3	+15	Pioggia moderata

(*) Rilievi fuori campo

L'INFORMAZIONE E' PREVENZIONE - LEGGI L'ATTUALE GRADO DI PERICOLO VALANGHE!

IL CAPO DEL CENTRO NAZIONALE METEOMONT
(Ten. Col. RFI Emanuela Gini)
FIRMA AUTOGRAFA OMESSA AI SENSI
DELL'ART.3 DEL D.LGS N.39/1993

Bollettino realizzato su scala sinottica-regionale (standard EAWS). La sua valutazione non può escludere in alcun modo la necessità di una seria e capace valutazione locale del pericolo (singolo pendio) che può essere anche sensibilmente diverso. Le previsioni meteorologiche sono relative all'orario UTC (per l'Italia +1 in inverno e +2 in estate).