Bulletin d'estimation du risque d'avalanche
(valable en dehors des pistes balisées et ouvertes)

MASSIF : Champsaur

Rédigé le jeudi 23 avril 2026 à 16h

Estimation des risques pour le : VENDREDI 24 AVRIL

MANTEAU NEIGEUX PRINTANIER - ACTIVITÉ EN NEIGE HUMIDE

2

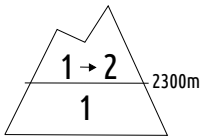

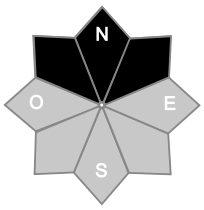

Au-dessus de 2300m indice de risque faible évoluant en limité, plus bas indice faible.

Départs spontanés : en neige humide en altitude.

Déclenchements provoqués : en neige humide en altitude.

Indices de risque : 5 très fort - 4 fort - 3 marqué - 2 limité - 1 faible -- En noir : les pentes les plus dangereuses

Stabilité du manteau neigeux

Situation avalancheuse typique : neige humide

Départs spontanés : peu probables en tout début de journée après bon le regel nocturne, puis reprise de l'humidification au fil de la course du soleil. Quelques départs superficiels sont alors possibles en journée, avalanches de petite taille (taille 1) en général. Néanmoins, un départ de plus grande ampleur est possible dans les pentes nord-ouest à nord-est au-dessus de 2300/2400 m environ, emportant la totalité du manteau neigeux. Avalanches de taille moyenne à grande (taille 2 à 3), dans le cas où l'humidification atteint des couches fragiles persistantes enfouies dans le manteau neigeux. En effet, l'activité en neige humide s'accentue avec la mise en place d'un temps ensoleillé et très doux pour une fin avril.

Déclenchements provoqués : un skieur coupant une pente raide trop tardivement peut initier un départ de neige humide sous ses skis. Départs ponctuels engendrant des avalanches de petite taille (taille 1), plus rarement moyenne (taille 2). Dans les orientation nord-ouest, nord et nord-est au-dessus de 2300/2400 m environ, Une première avalanche superficielle de neige humide déclenchée par un skieur peut dans de rares cas provoquer un second départ linéaire plus volumineux en venant solliciter une couche fragile persistante plus profondément enfouie dans le manteau neigeux. Avalanches de taille moyenne à grande (taille 2 à 3).

Qualité de la neige

Enneigement désormais déficitaire, notamment en adrets.
Hauteurs de neige observées : 112 cm au-dessus de Prapic à 2500 m, 60 cm à la nivôse d'Orcières à 2300 m.

Limite d'enneigement skiable : très localement vers 1600/1700 m en fond de vallée en cœur de massif, 2200/2400 m en adrets.

État de la neige de surface : manteau neigeux printanier, voire de névé en toute orientation sous 2200 m environ et en adrets jusqu'à 3000 m d'altitude. On trouve encore de la neige froide en versants nord de haute altitude au delà de 2900/3000 m. Bon regel nocturne, puis reprise de l'humidification avec le retour du soleil et la hausse de l'isotherme 0 degré.

Aperçu météo pour le vendredi 24 avril

	nuit	matin	après-midi	soir

Bien ensoleillé et de plus en plus doux. Vent faible et variable en altitude.

Pluie-Neige				
Iso 0 °C	3 100 m	3 100 m	3 200 m	3 200 m
Vent 2000 m	↓ 10 km/h	↑ 5 km/h	→ 15 km/h	← 10 km/h
Vent 3000 m	↙ 15 km/h	↗ 10 km/h	→ 10 km/h	↘ 10 km/h

Épaisseur de neige hors-piste

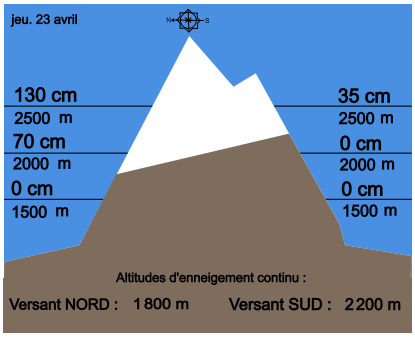

Précipitations à 1800 m

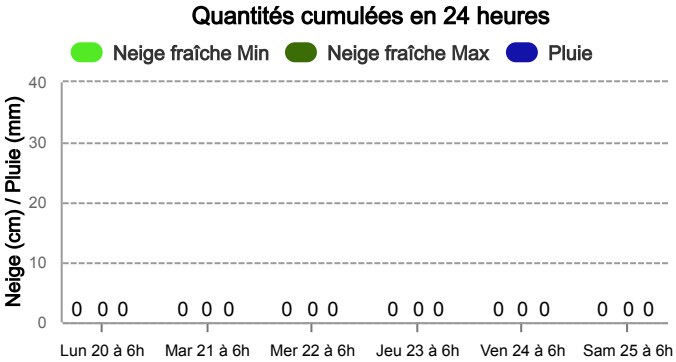

Tendance du samedi 25 avril

2

Indice de risque limité

Maintien d'un risque limité avec toujours des avalanches de neige humide en cours de journée. Une rare grande avalanche reste possible dans les ubacs de haute altitude.

Pour consulter la vigilance en cours, veuillez vous rendre sur le site https://vigilance.meteofrance.fr/fr

Météo-France - 73 avenue de Paris, 94165 Saint-Mandé cedex - Contact : contact@meteo.fr

Rédigé par Météo-France avec la contribution des observateurs du réseau nivo-météorologiques. Partenariat : ANMSM (Maires de Stations de Montagne), DSF (Domaines Skiables de France), ADSP (Directeurs de Pistes et de la Sécurité des Stations de Sports d'Hiver) et autres acteurs de la montagne.

Bulletin neige & avalanches par téléphone au
0 892 68 10 20 Service 0,35 € / min + prix appel

RÉPUBLIQUE FRANÇAISE
Liberté Égalité Fraternité

METEO FRANCE
À VOS CÔTÉS, DANS UN CLIMAT QUI CHANGE

Bulletin d'estimation du risque d'avalanche

(valable en dehors des pistes balisées et ouvertes)

MASSIF : Champsaur

Rédigé le jeudi 23 avril 2026 à 16h

Conditions nivo-météo des 7 derniers jours

	ven. 17/04				sam. 18/04				dim. 19/04				lun. 20/04				mar. 21/04				mer. 22/04				jeu. 23/04			
	03h	09h	15h	21h	03h	09h	15h	21h	03h	09h	15h	21h	03h	09h	15h	21h	03h	09h	15h	21h	03h	09h	15h	21h	03h	09h	15h	21h
Météo																												
Vent (km/h)	5	10	10	10	10	10	15	10	15	20	25	20	20	20	25	20	20	20	25	20	20	25	25	15	20	15	15	15
à 3000m																												
Vent (km/h)	5	10	10	5	5	5	15	10	10	10	25	10	10	15	25	10	10	10	25	10	15	15	25	10	5	10	15	10
à 2000m																												

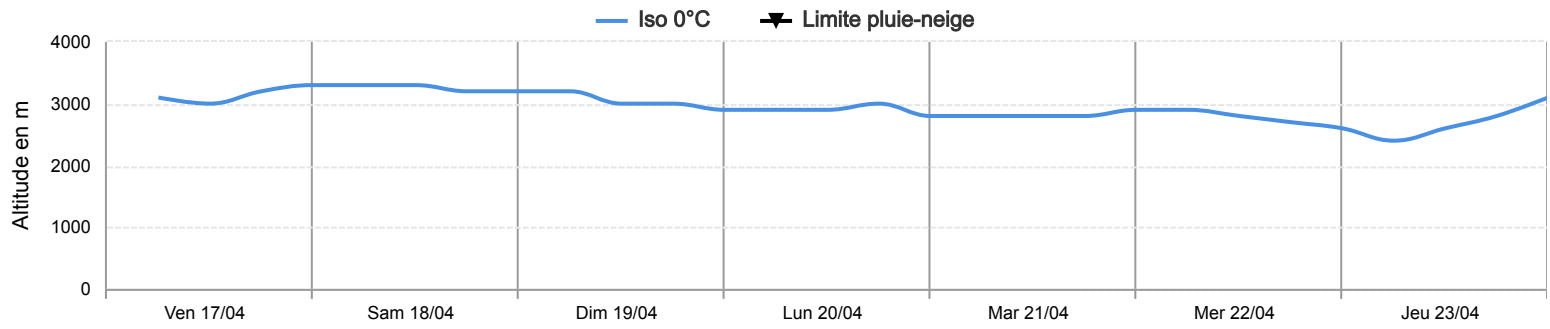

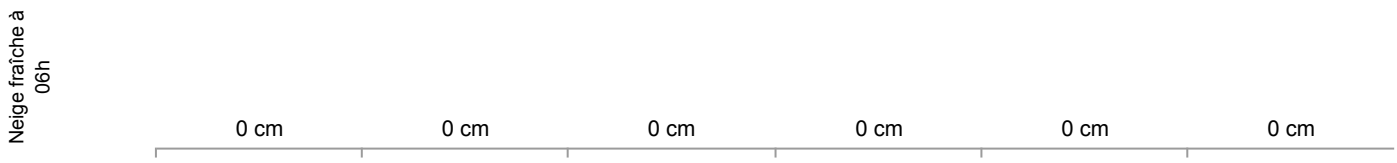

Risque d'avalanche	ven. 17/04	sam. 18/04	dim. 19/04	lun. 20/04	mar. 21/04	mer. 22/04	jeu. 23/04
	2	2	2	2	2	1	2

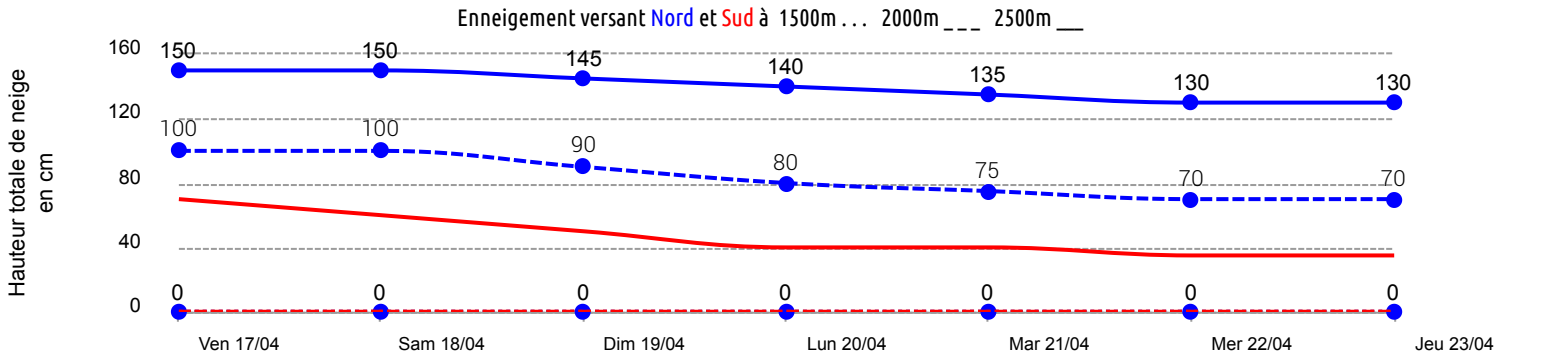

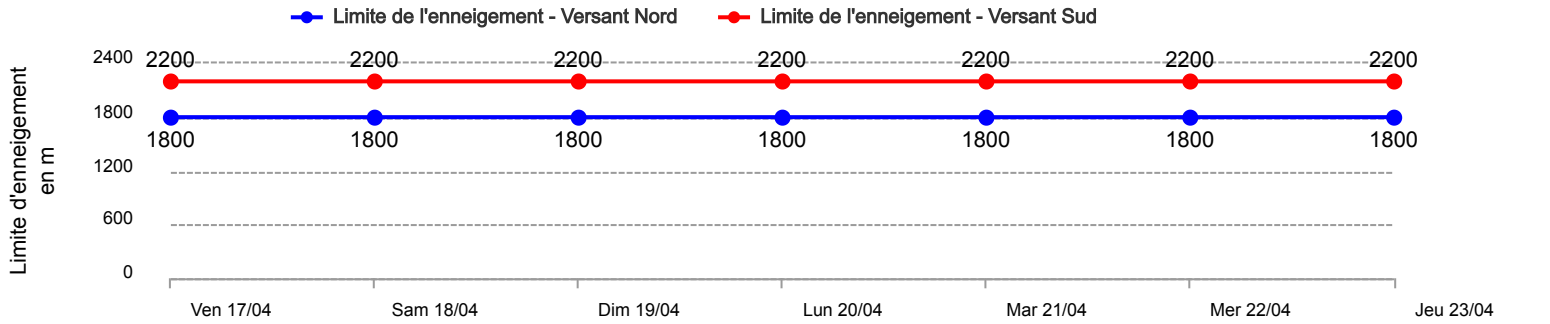

Pour consulter la vigilance en cours, veuillez vous rendre sur le site https://vigilance.meteofrance.fr/fr

Météo-France - 73 avenue de Paris, 94165 Saint-Mandé cedex - Contact : contact@meteo.fr

Rédigé par Météo-France avec la contribution des observateurs du réseau nivo-météorologiques. Partenariat : ANMSM (Maires de Stations de Montagne), DSF (Domaines Skiables de France), ADSP (Directeurs de Pistes et de la Sécurité des Stations de Sports d'Hiver) et autres acteurs de la montagne.

Bulletin neige & avalanches par téléphone au

0 892 68 10 20 Service 0,35 € / min + prix appel