RÉPUBLIQUE FRANÇAISE
Liberté Égalité Fraternité

METEO FRANCE
À VOS CÔTÉS, DANS UN CLIMAT QUI CHANGE

Bulletin d'estimation du risque d'avalanche
(valable en dehors des pistes balisées et ouvertes)
MASSIF : Couserans

Rédigé le jeudi 23 avril 2026 à 16h

Estimation des risques pour le : VENDREDI 24 AVRIL

POURSUITE DE L'HUMIDIFICATION, GRANDES AVALANCHES DE FOND POSSIBLES.

3

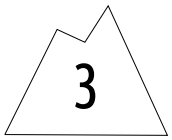

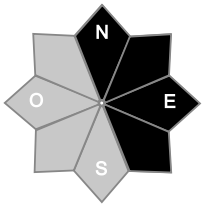

Indice de risque marqué.

Départs spontanés : Avalanches de surface et avalanches de fond en neige humide

Déclenchements provoqués : Départs ponctuels en neige humide favorisés par le passage d'un randonneur

Indices de risque : 5 très fort - 4 fort - 3 marqué - 2 limité - 1 faible -- En noir : les pentes les plus dangereuses

Stabilité du manteau neigeux

Situation avalancheuse typique : avalanches de fond neige humide

Départs spontanés :
- En altitude, avec l'humidification qui gagne en profondeur, des **avalanches de glissement** emportant l'ensemble du manteau neigeux sont possibles en toutes orientations (fissures/reptations et avalanches de glissement signalées ces derniers jours). Elles seront de taille moyenne à grande, voire plus rarement très grandes dans les zones de plus fortes accumulations (pentes nord à sud-est). Les déclenchements sont rares en matinée et deviennent plus nombreux l'après-midi pouvant aussi être initiés par la rupture d'une corniches sommitale ou après une averse. Les cassures peuvent localement dépasser les 1 à 2m d'épaisseur. Ces avalanches peuvent alors parcourir de grands dénivelés dans les couloirs d'avalanche habituels, finissant leur course parfois beaucoup plus bas que la limite d'enneigement actuelle, pouvant aussi entrainer des chutes de pierres. D'autre part, la présence d'un dépôt plus ou moins ancien n'est pas forcément un gage de sécurité dans le cas d'une pente sus-jacente pas totalement purgée.
- Avec un manteau intégralement humidifié, regelant à peine en surface, des départs ponctuels d'**avalanches de neige humide**, de taille petite à moyenne sont déjà attendus dès le matin et deviennent plus nombreux au cours de la journée.

Déclenchements provoqués :
- Un skieur coupant une pente raide déjà bien humidifiée pourra favoriser un départ ponctuel de taille petite à plus rarement moyenne. Ces coulées peuvent emporter les skis et provoquer la chute. Les pentes orientées Est le matin puis Ouest en fin de journée (en passant par le Sud) sont les plus exposées à ce risque.

Autre : Des corniches encore imposantes sont en place et sont susceptibles de céder spontanément avec l'humidification, tout comme les ponts de neige sur les torrents bien alimentés par la fonte en cours.

Qualité de la neige

Enneigement :
L'enneigement dans nos massifs reste bon pour la saison, encore largement supérieur à celui des derniers hivers. Avec la douceur ambiante, le manteau perd une dizaine de cm par jour en deçà de 2300/2400 m, et la limite skiable remonte progressivement, surtout en sud (où les quantités sont moins importantes). Elle est encore au mieux vers 1600/1700 m en nord et 1900 à 2000 m en sud, localement plus haut dans des zones moins enneigées cet hiver. On trouve ensuite rapidement une bonne épaisseur de neige qui dépasse encore souvent les 1m à 2000 m en nord, et 2m50 à 2500m.

Qualité de la neige :
Au petit matin, seules les pentes les plus hautes devraient connaitre un regel en surface à la faveur des éclaircies de la nuit. Ailleurs, le regel est beaucoup plus aléatoire et bien souvent inexistant. L'humidification reprend rapidement en matinée, et se poursuit l'après-midi avec les nouvelles averses prévues. Exceptés les plus hauts sommets qui peuvent localement avoir été reblanchis par les averses, la surface du manteau est souvent constituée de neige ocre, chargée en poussières sahariennes qui contribuent à accélérer la fonte. L'après-midi, la neige et partout lourde, souvent non portante pour les piétons. Les cols et crêtes ouest à nord-ouest sont généralement moins garnis en neige voire pelés. Les pentes Sud et les plaques de neige résiduelles en dessous de 2000m sont souvent plus faciles à skier avec une neige plus dense, de type névé.

Aperçu météo pour le vendredi 24 avril

	nuit	matin	après-midi	soir
	Poursuite de la douceur avec des averses d'évolution diurne			
Pluie-Neige			2 900 m	2 800 m
Iso 0 °C	3 300 m	3 200 m	3 200 m	3 200 m
Vent 2000 m	↑ 20 km/h	↓ 15 km/h	↙ 20 km/h	↗ 10 km/h
Vent 3000 m	↑ 25 km/h	↙ 15 km/h	↓ 20 km/h	→ 15 km/h

Pour consulter la vigilance en cours, veuillez vous rendre sur le site https://vigilance.meteofrance.fr/fr

Météo-France - 73 avenue de Paris, 94165 Saint-Mandé cedex - Contact : contact@meteo.fr

Rédigé par Météo-France avec la contribution des observateurs du réseau nivo-météorologiques. Partenariat : ANMSM (Maires de Stations de Montagne), DSF (Domaines Skiables de France), ADSP (Directeurs de Pistes et de la Sécurité des Stations de Sports d'Hiver) et autres acteurs de la montagne.

Bulletin neige & avalanches par téléphone au
0 892 68 10 20 Service 0,35 € / min + prix appel

Bulletin d'estimation du risque d'avalanche

(valable en dehors des pistes balisées et ouvertes)

MASSIF : Couserans

Rédigé le jeudi 23 avril 2026 à 16h

Épaisseur de neige hors-piste

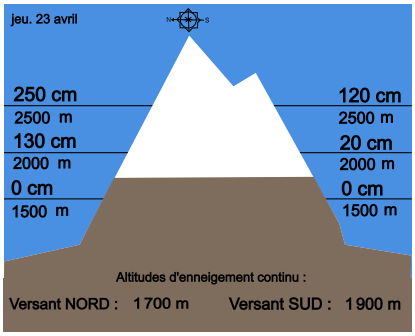

Précipitations à 1800 m

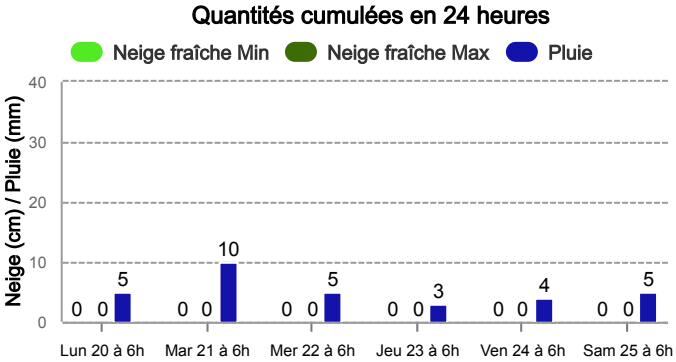

Tendance du samedi 25 avril

Indice de risque marqué

Peu d'évolution avec la douceur et de nouvelles averses

Pour consulter la vigilance en cours, veuillez vous rendre sur le site https://vigilance.meteofrance.fr/fr

Météo-France - 73 avenue de Paris, 94165 Saint-Mandé cedex - Contact : contact@meteo.fr

Rédigé par Météo-France avec la contribution des observateurs du réseau nivo-météorologiques. Partenariat : ANMSM (Maires de Stations de Montagne), DSF (Domaines Skiables de France), ADSP (Directeurs de Pistes et de la Sécurité des Stations de Sports d'Hiver) et autres acteurs de la montagne.

Bulletin neige & avalanches par téléphone au

0 892 68 10 20 Service 0,35 € / min + prix appel

RÉPUBLIQUE FRANÇAISE
Liberté Égalité Fraternité

METEO FRANCE
À VOS CÔTÉS, DANS UN CLIMAT QUI CHANGE

Bulletin d'estimation du risque d'avalanche

(valable en dehors des pistes balisées et ouvertes)

MASSIF : Couserans

Rédigé le jeudi 23 avril 2026 à 16h

Conditions nivo-météo des 7 derniers jours

	ven. 17/04				sam. 18/04				dim. 19/04				lun. 20/04				mar. 21/04				mer. 22/04				jeu. 23/04			
	03h	09h	15h	21h	03h	09h	15h	21h	03h	09h	15h	21h	03h	09h	15h	21h	03h	09h	15h	21h	03h	09h	15h	21h	03h	09h	15h	21h
Météo																												
Vent (km/h)	20	20	15	15	15	15	20	15	20	15	20	20	25	25	30	25	25	30	40	40	45	25	25	20	25	20	25	15
à 3000m																												
Vent (km/h)	10	10	10	10	10	10	15	10	15	10	15	15	20	20	20	15	15	20	25	35	40	20	20	15	15	15	20	15
à 2000m																												

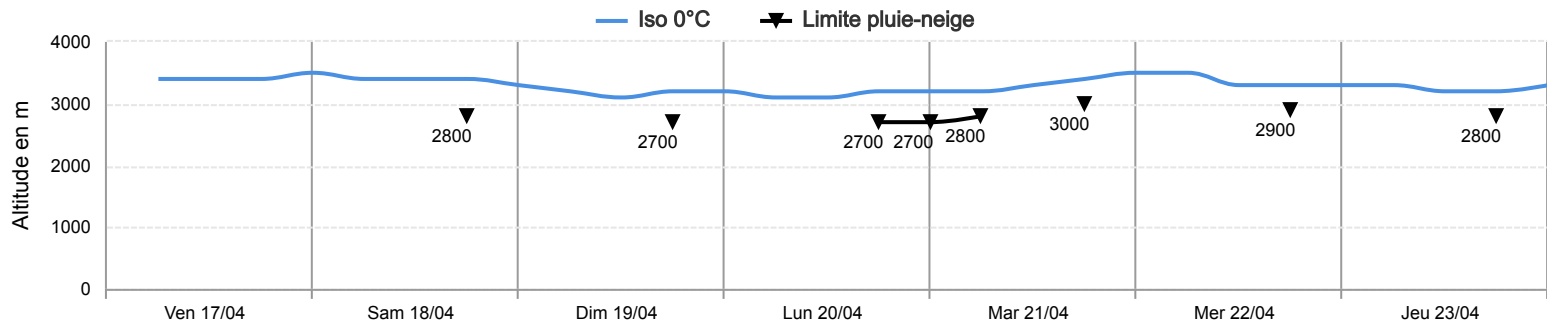

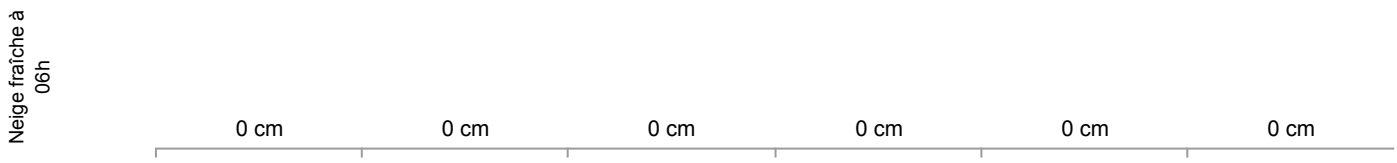

Risque d'avalanche							
	2	2	2	2	2	3	3
	ven. 17/04	sam. 18/04	dim. 19/04	lun. 20/04	mar. 21/04	mer. 22/04	jeu. 23/04

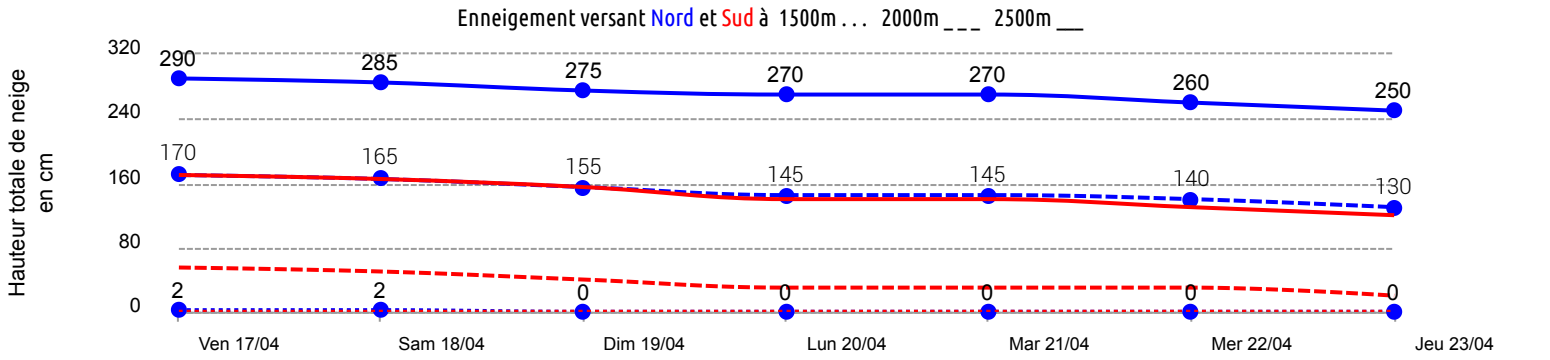

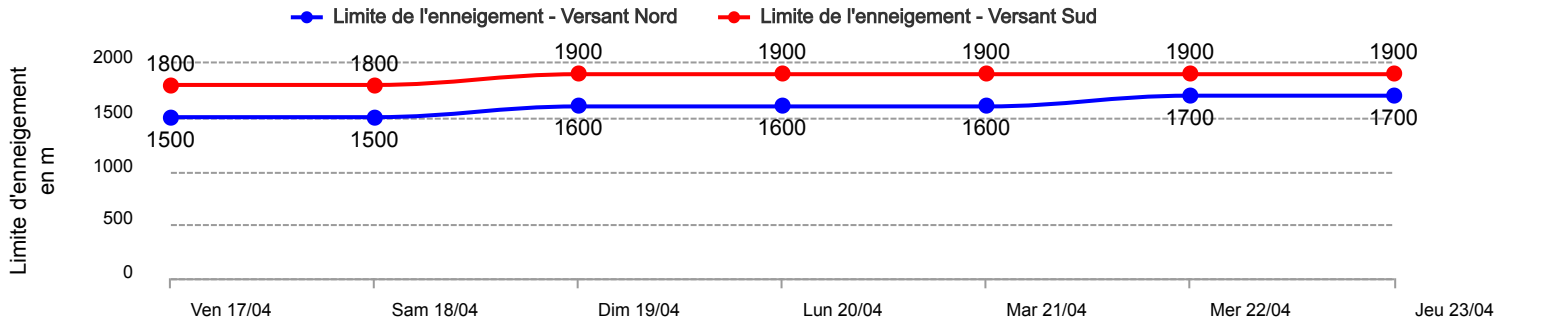

Pour consulter la vigilance en cours, veuillez vous rendre sur le site https://vigilance.meteofrance.fr/fr

Météo-France - 73 avenue de Paris, 94165 Saint-Mandé cedex - Contact : contact@meteo.fr

Bulletin neige & avalanches par téléphone au **0 892 68 10 20** Service 0,35 € / min + prix appel

Rédigé par Météo-France avec la contribution des observateurs du réseau nivo-météorologiques. Partenariat : ANMSM (Maires de Stations de Montagne), DSF (Domaines Skiables de France), ADSP (Directeurs de Pistes et de la Sécurité des Stations de Sports d'Hiver) et autres acteurs de la montagne.