Bulletin d'estimation du risque d'avalanche
(valable en dehors des pistes balisées et ouvertes)

MASSIF : Luchonnais

Rédigé le jeudi 23 avril 2026 à 16h

Estimation des risques pour le : VENDREDI 24 AVRIL

PEU DE REGEL, ACTIVITÉ POSSIBLE DÈS LE MATIN, GRANDES AVALANCHES POSSIBLES

3

3

N O E S

Rares mais grandes

Indices de risque : 5 très fort - 4 fort - 3 marqué - 2 limité - 1 faible -- En noir : les pentes les plus dangereuses

Indice de risque marqué.

Départs spontanés : En neige humide, grandes voire très grandes rares mais possibles

Déclenchements provoqués : En neige humide sous les skis.

Stabilité du manteau neigeux

Situation avalancheuse typique : neige humide — avalanches de fond

Départs spontanés :
Avec un manteau intégralement humidifié, regelant à peine en surface, des départs ponctuels de taille petite à moyenne sont attendus même tôt le matin et deviennent nombreux au cours de la journée.
Des **avalanches de fond** sont aussi possibles, à tout moment, partant en général d'une des nombreuses fissures déjà ouvertes. Elles restent rares, mais **peuvent atteindre une grande voire très grande taille en pente raide** et glisser sous forme de blocs rapides roulants se détachant ou en écoulement global plus lent. Les fissures ouvertes dépassent souvent le mètre d'épaisseur, en particulier en expositions nord-ouest à nord-est. Dans les autres expositions, les accumulations sont moindres et le manteau est plus tassé, moins instable.
Les zones de départ se situent plutôt au-dessus de 2000 m mais ces avalanches de fond **peuvent parcourir des dénivelés importants et atteindre des sentiers à des altitudes inférieures à la limite d'enneigement** dans les couloirs d'avalanche habituels. Ce risque est surtout présent en secteur frontalier, plus enneigé ou sur les hauts massifs.

Déclenchements provoqués :
Le passage d'un skieur ou randonneur dans une pente en neige très humide peut favoriser un départ ponctuel de surface de taille petite à moyenne, en particulier en expositions nord moins stabilisées par tassement.

Autres : **corniches et ponts de neige encore en place extrêmement peu résistants**, pouvant céder dès le matin sous le poids d'une seule personne. Une avalanche ancienne, même récente d'une heure précédemment, peut être suivie d'une autre coulée au même endroit, **suravalanches fréquentes**.

Qualité de la neige

Enneigement : plutôt bon pour la saison et débutant encore vers 1750 m en nord, au-dessus de 2000 m en sud.
Les limites de cet enneigement remontent progressivement dans la douceur ambiante, sous les éclaircies matinales et les quelques averses de l'après-midi.
État de la neige : Le manteau neigeux subit la longue période de douceur. En expositions ensoleillées, et sur la neige ocre, le manteau est printanier à tous niveaux, sans regel mais assez portant. En expositions nord, plutôt au-dessus de 2500 m, une petite croûte non portante peut être présente au petit matin, mais disparaît rapidement. En journée, les **enfoncements y deviennent importants, dans une neige sans consistance.**

Aperçu météo pour le vendredi 24 avril

Eclaircies le matin, des cumulus plus nombreux l'après-midi avec des averses possibles, orageuses parfois. Nuages bas la nuit suivante sous 1800 m.

	nuit	matin	après-midi	soir
Pluie-Neige		2 600 m	2 900 m	2 800 m
Iso 0 °C	3 400 m	3 300 m	3 200 m	3 200 m
Vent 2000 m	20 km/h	10 km/h	15 km/h	5 km/h
Vent 3000 m	30 km/h	25 km/h	30 km/h	15 km/h

Épaisseur de neige hors-piste

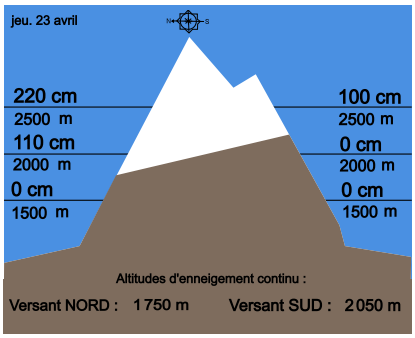

Précipitations à 1800 m

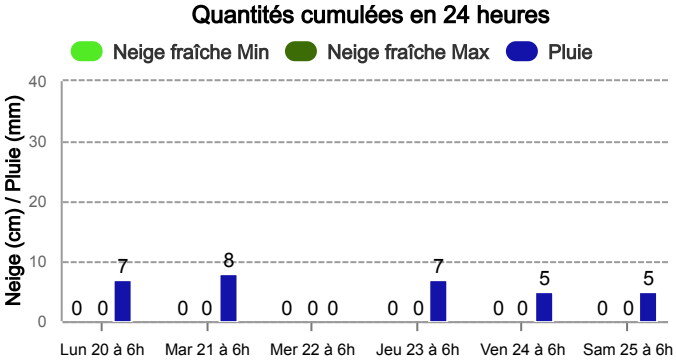

Tendance du samedi 25 avril

3

Indice de risque marqué

Risques maintenus en neige humide.

Pour consulter la vigilance en cours, veuillez vous rendre sur le site https://vigilance.meteofrance.fr/fr

Météo-France - 73 avenue de Paris, 94165 Saint-Mandé cedex - Contact : contact@meteo.fr

Rédigé par Météo-France avec la contribution des observateurs du réseau nivo-météorologiques. Partenariat : ANMSM (Maires de Stations de Montagne), DSF (Domaines Skiables de France), ADSP (Directeurs de Pistes et de la Sécurité des Stations de Sports d'Hiver) et autres acteurs de la montagne.

Bulletin neige & avalanches par téléphone au 0 892 68 10 20 Service 0,35 € / min + prix appel

RÉPUBLIQUE FRANÇAISE
Liberté Égalité Fraternité

METEO FRANCE
À VOS CÔTÉS, DANS UN CLIMAT QUI CHANGE

Bulletin d'estimation du risque d'avalanche

(valable en dehors des pistes balisées et ouvertes)

MASSIF : Luchonnais

Rédigé le jeudi 23 avril 2026 à 16h

Conditions nivo-météo des 7 derniers jours

	ven. 17/04				sam. 18/04				dim. 19/04				lun. 20/04				mar. 21/04				mer. 22/04				jeu. 23/04			
	03h	09h	15h	21h	03h	09h	15h	21h	03h	09h	15h	21h	03h	09h	15h	21h	03h	09h	15h	21h	03h	09h	15h	21h	03h	09h	15h	21h
Météo																												
Vent (km/h)	20	15	10	10	10	10	25	20	20	20	30	25	25	20	55	25	20	25	30	45	35	40	25	30	35	20	30	45
à 3000m																												
Vent (km/h)	5	5	5	5	5	5	15	10	15	15	20	10	5	10	15	5	5	10	10	15	35	25	20	10	15	15	20	25
à 2000m																												

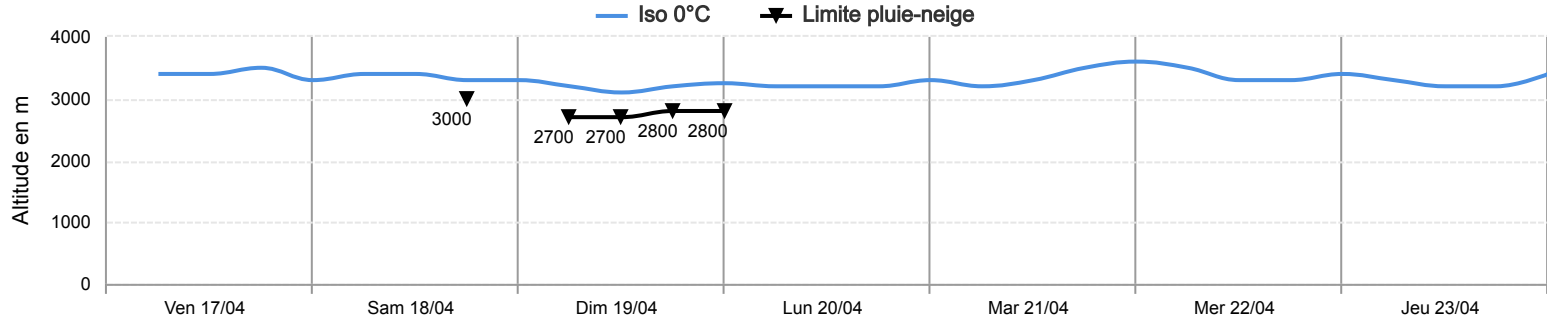

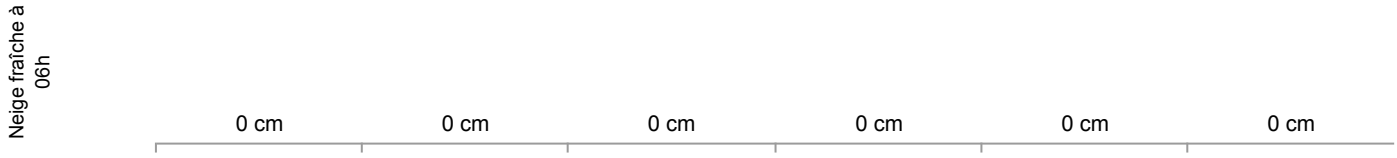

Risque d'avalanche	ven. 17/04	sam. 18/04	dim. 19/04	lun. 20/04	mar. 21/04	mer. 22/04	jeu. 23/04
	2	2	2	2	2	3	3

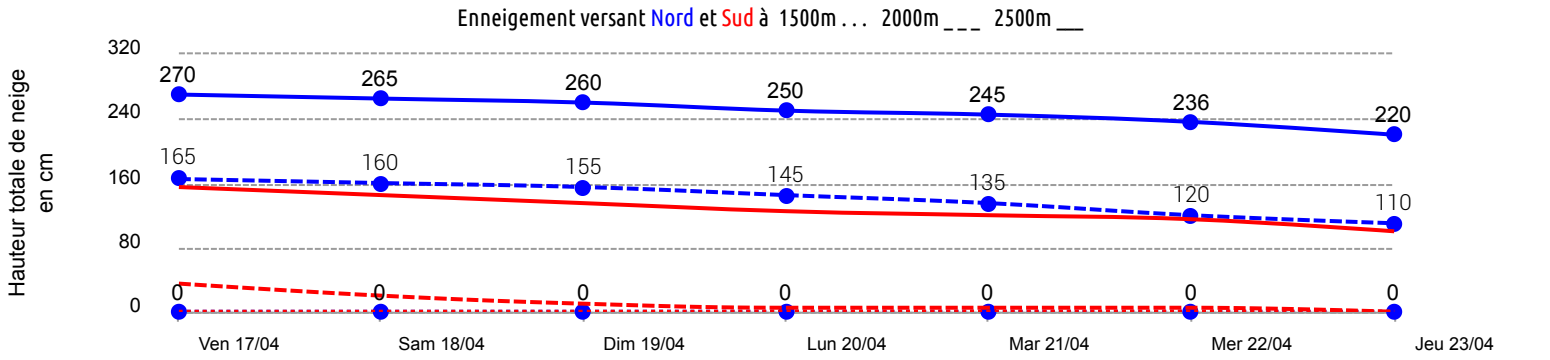

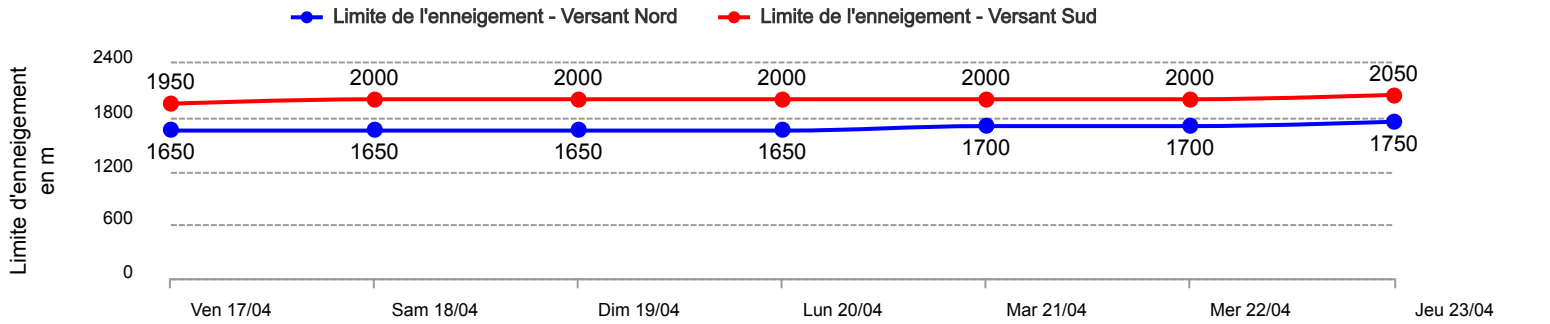

Pour consulter la vigilance en cours, veuillez vous rendre sur le site https://vigilance.meteofrance.fr/fr

Météo-France - 73 avenue de Paris, 94165 Saint-Mandé cedex - Contact : contact@meteo.fr

Rédigé par Météo-France avec la contribution des observateurs du réseau nivo-météorologiques. Partenariat : ANMSM (Maires de Stations de Montagne), DSF (Domaines Skiables de France), ADSP (Directeurs de Pistes et de la Sécurité des Stations de Sports d'Hiver) et autres acteurs de la montagne.

Bulletin neige & avalanches par téléphone au
0 892 68 10 20 Service 0,35 € / min + prix appel