Bulletin d'estimation du risque d'avalanche

(valable en dehors des pistes balisées et ouvertes)

MASSIF : Mercantour

Rédigé le jeudi 23 avril 2026 à 16h

Estimation des risques pour le : VENDREDI 24 AVRIL

MANTEAU NEIGEUX PRINTANIER - UN PEU D'ACTIVITÉ EN NEIGE HUMIDE

2

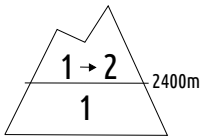

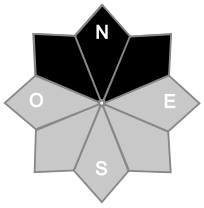

Au-dessus de 2400m indice de risque faible évoluant en limité, plus bas indice faible.

Départs spontanés : avalanches en neige humide aux heures chaudes de la journée

Déclenchements provoqués : en neige humide sous les skis

Indices de risque : 5 très fort - 4 fort - 3 marqué - 2 limité - 1 faible -- En noir : les pentes les plus dangereuses

Stabilité du manteau neigeux

Situation avalancheuse typique : neige humide

Départs spontanés : peu probables au petit matin avec le bon regel nocturne, puis risque en augmentation au fil du réchauffement au soleil. Rares avalanches en neige humide, de taille moyenne, grande non exclue, dans les pentes nord-ouest / nord / nord-est au-dessus de 2400 m environ, pouvant emporter la totalité du manteau neigeux en place. Dans les autres orientations / altitudes, le manteau neigeux printanier, dense, est bien stabilisé.

Déclenchements provoqués : un skieur coupant une pente raide trop tardivement peut initier un départ de neige humide sous ses skis. Dans les ubacs d'altitude supérieure à 2400 m environ, une première avalanche superficielle de neige humide déclenchée par un skieur peut dans de très rares cas provoquer un second départ linéaire plus volumineux.

Qualité de la neige

Enneigement nettement déficitaire pour la période, avec une fonte qui se poursuit à un rythme élevé. Absence de précipitations significatives depuis plus d'un mois et grande douceur en place depuis début avril.
Hauteurs de neige observées : 81 cm à la Nivose de Millefonts à 2430 m, 6 cm à Isola 2000 à 1900 m.

Enneigement skiable généralement à partir de 1900/2000 m en ubacs sur terrain favorable (routes forestières, terrains herbeux) et 2300/2400 m en adrets peu pentus.

État de la neige en surface : manteau neigeux printanier sous 2400 m environ ou en adrets d'altitude. Neige durcie par le regel le matin puis passage en neige pourrie dans l'après-midi. Manteau neigeux pas totalement transformé dans les versants plein nord au dessus de 2400/2500 m environ.

Aperçu météo pour le vendredi 24 avril

	nuit	matin	après-midi	soir
Temps sec et doux. +14° à 2000 m et +6° à 3000 m				
Pluie-Neige				
Iso 0 °C	3 000 m	3 100 m	3 200 m	3 400 m
Vent 2000 m	↙ 10 km/h	↑ 10 km/h	↗ 15 km/h	↘ 10 km/h
Vent 3000 m	↘ 20 km/h	→ 15 km/h	↗ 25 km/h	↘ 15 km/h

Épaisseur de neige hors-piste

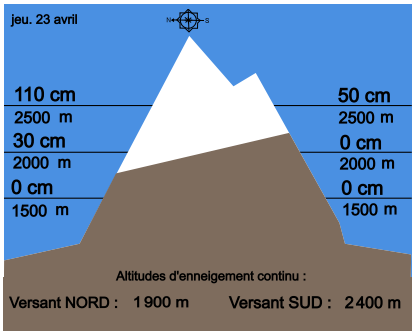

Précipitations à 1800 m

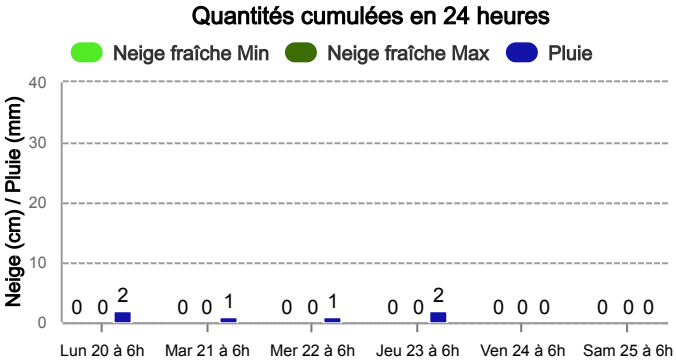

Tendance du samedi 25 avril

2

Indice de risque limité

La situation nivologique évolue peu avec le maintien d'un risque limité en altitude. Regel nocturne correct puis reprise de l'humidification en journée sous un doux soleil.

Pour consulter la vigilance en cours, veuillez vous rendre sur le site https://vigilance.meteofrance.fr/fr

Météo-France - 73 avenue de Paris, 94165 Saint-Mandé cedex - Contact : contact@meteo.fr

Rédigé par Météo-France avec la contribution des observateurs du réseau nivo-météorologiques. Partenariat : ANMSM (Maires de Stations de Montagne), DSF (Domaines Skiables de France), ADSP (Directeurs de Pistes et de la Sécurité des Stations de Sports d'Hiver) et autres acteurs de la montagne.

Bulletin neige & avalanches par téléphone au 0 892 68 10 20 Service 0,35 € / min + prix appel

RÉPUBLIQUE FRANÇAISE
Liberté Égalité Fraternité

METEO FRANCE
À VOS CÔTÉS, DANS UN CLIMAT QUI CHANGE

Bulletin d'estimation du risque d'avalanche
(valable en dehors des pistes balisées et ouvertes)

MASSIF : Mercantour

Rédigé le jeudi 23 avril 2026 à 16h

Conditions nivo-météo des 7 derniers jours

	ven. 17/04				sam. 18/04				dim. 19/04				lun. 20/04				mar. 21/04				mer. 22/04				jeu. 23/04			
	03h	09h	15h	21h	03h	09h	15h	21h	03h	09h	15h	21h	03h	09h	15h	21h	03h	09h	15h	21h	03h	09h	15h	21h	03h	09h	15h	21h
Météo																												
Vent (km/h)	10	15	20	10	15	10	25	20	20	30	40	30	30	35	35	30	35	40	40	40	35	35	35	15	15	20	30	20
à 3000m																												
Vent (km/h)	10	10	15	10	10	15	20	10	10	15	25	15	15	20	25	15	15	15	20	10	15	25	20	20	20	20	30	15
à 2000m																												

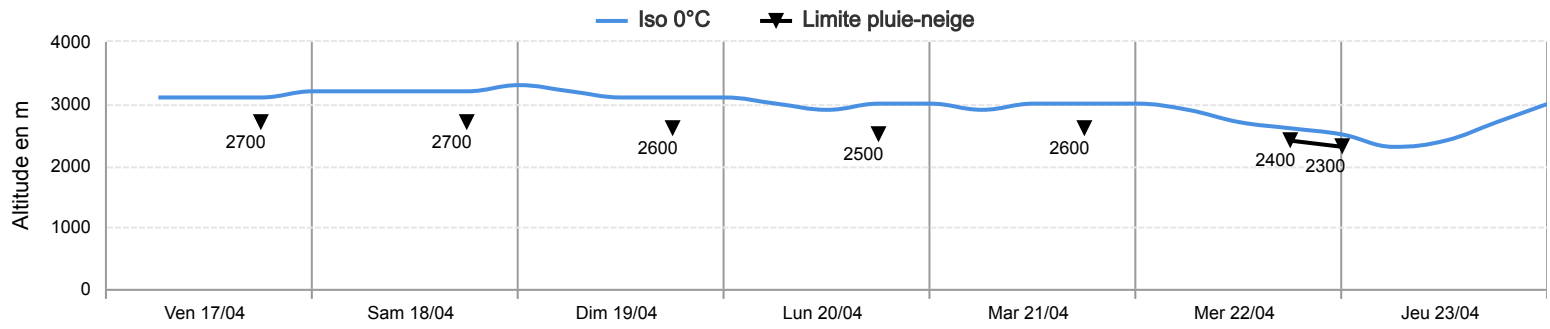

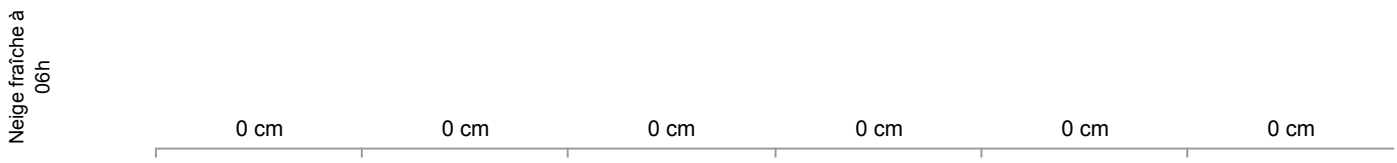

Risque d'avalanche	ven. 17/04	sam. 18/04	dim. 19/04	lun. 20/04	mar. 21/04	mer. 22/04	jeu. 23/04
	2	2	2	2	2	2	2

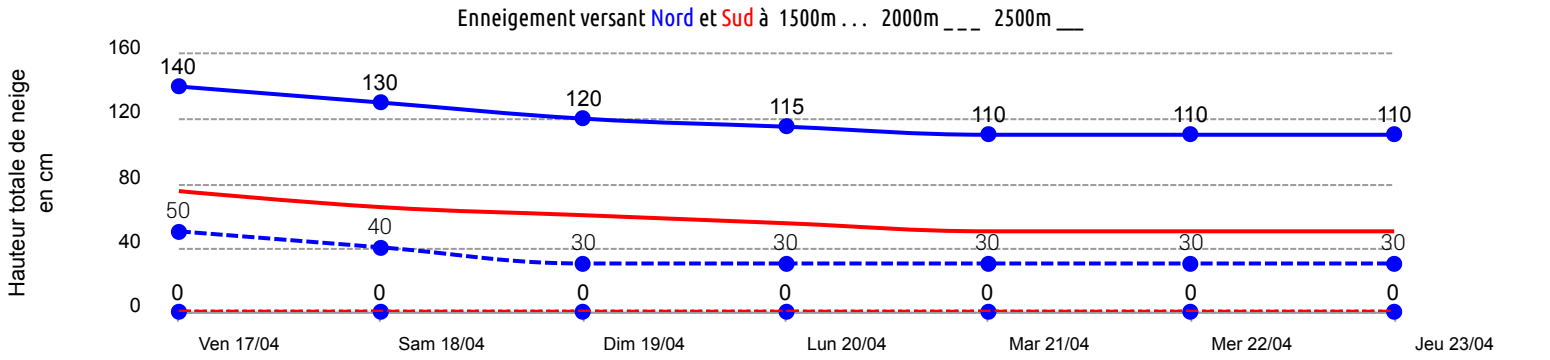

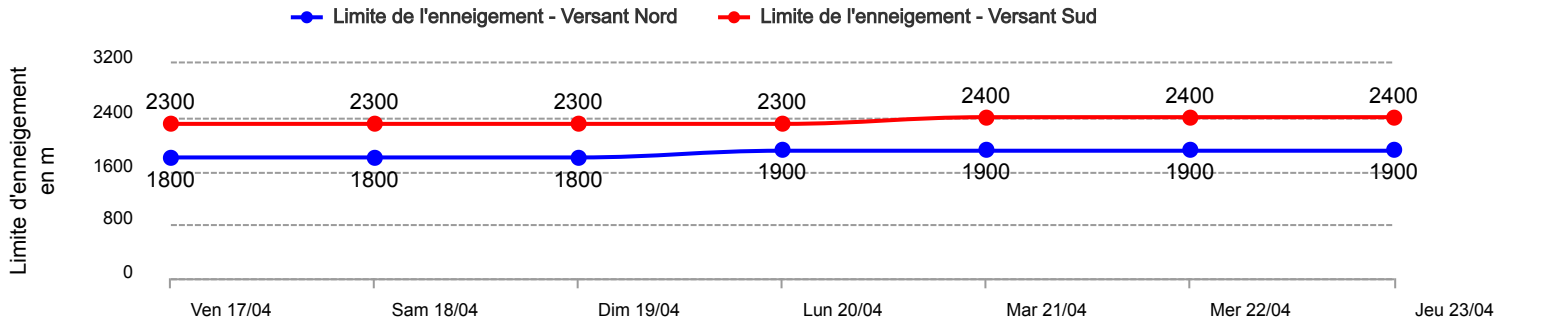

Pour consulter la vigilance en cours, veuillez vous rendre sur le site https://vigilance.meteofrance.fr/fr

Météo-France - 73 avenue de Paris, 94165 Saint-Mandé cedex - Contact : contact@meteo.fr

Bulletin neige & avalanches par téléphone au **0 892 68 10 20** Service 0,35 € / min + prix appel

Rédigé par Météo-France avec la contribution des observateurs du réseau nivo-météorologiques. Partenariat : ANMSM (Maires de Stations de Montagne), DSF (Domaines Skiables de France), ADSP (Directeurs de Pistes et de la Sécurité des Stations de Sports d'Hiver) et autres acteurs de la montagne.