Bulletin d'estimation du risque d'avalanche
(valable en dehors des pistes balisées et ouvertes)

MASSIF : Oisans

Rédigé le jeudi 23 avril 2026 à 16h

Estimation des risques pour le : VENDREDI 24 AVRIL

MANTEAU NEIGEUX PRINTANIER, BON REGEL NOCTURNE, HUMIDIFICATION EN JOURNEE

2

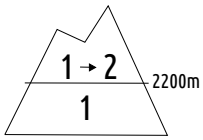

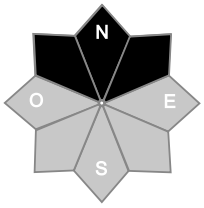

Au-dessus de 2200m indice de risque faible évoluant en limité, plus bas indice faible.

Départs spontanés : Rares coulées humides ou départs au terrain. Une cassure linéaire ne peut être totalement exclue en Nord.

Déclenchements provoqués : Coulées ponctuelles sous les skis en neige pourrie.

Indices de risque : 5 très fort - 4 fort - 3 marqué - 2 limité - 1 faible -- En noir : les pentes les plus dangereuses

Stabilité du manteau neigeux

Situation avalancheuse typique : neige humide

Départs spontanés : Rares avalanches humides aux heures chaudes de la journée. Dans les pentes Est, Nord et Ouest, l'humidification gagne en profondeur et pourrait atteindre une couche fragile persistante, dans quel cas une avalanche de grande taille serait possible, avec une cassure linéaire.
Dans les autres pentes et sous 2200m, le manteau est souvent déjà bien stabilisé par les trois dernières semaines printanières, limitant fortement le risque de coulées.

Déclenchements provoqués : En terrain raide et bien humidifié, risque limité de coulée ponctuelle sous les skis. Très rarement dans les pentes Est, Nord et Ouest, le départ d'une coulée ponctuelle pourrait créer une surcharge suffisante pour venir solliciter les couches fragiles enfouies, et faire partir en cascade une avalanche de plaque de grande taille.

Autres : Neige parfois durcie / croûtée par le regel en matinée. Risque de chutes de corniches...

Qualité de la neige

Qualification de l'enneigement : L'enneigement s'est bien réduit depuis 3 semaines, et devient progressivement déficitaire en Sud et en moyenne montagne. Il reste de saison dans les versants peu ensoleillés au-dessus de 2000m.

Limites skiables : Vers 1600/1800m en Nord à 1900/2300m suivant l'exposition au soleil, la raideur de la pente...

Qualité de la neige vendredi : Regel nocturne correct à très bon en altitude. Neige croûtée / durcie par le regel. L'humidification reprend rapidement au soleil, avec un créneau en "moquette", avant un passage en neige pourrie dans l'après-midi. Dans les versants plein Nord d'altitude, possibilité de trouver encore quelques pentes en poudreuse dense.

Aperçu météo pour le vendredi 24 avril

	nuit	matin	après-midi	soir
Pluie-Neige				
Iso 0 °C	3 000 m	3 200 m	3 200 m	3 300 m
Vent 2500 m	← 5 km/h	↘ 5 km/h	→ 10 km/h	→ 5 km/h
Vent 3500 m	← 10 km/h	↻ 5 km/h	↗ 10 km/h	← 10 km/h

Très belle journée ensoleillée, sous une grande douceur.

Épaisseur de neige hors-piste

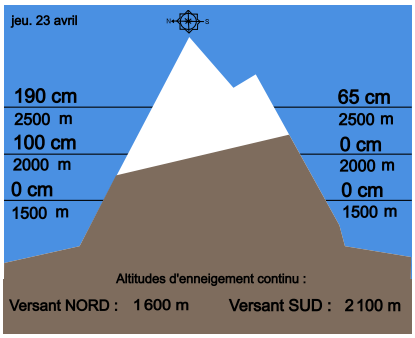

Précipitations à 1800 m

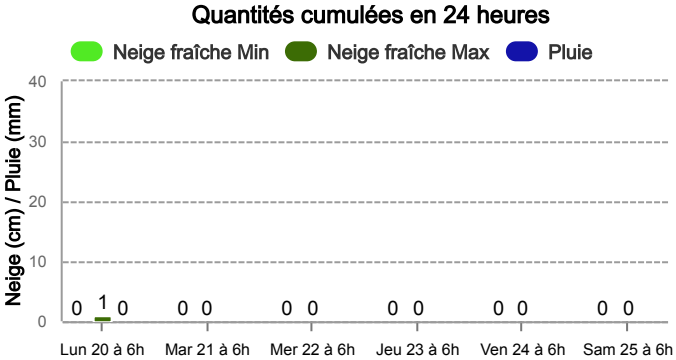

Tendance du samedi 25 avril

2

Indice de risque limité

Samedi, temps ensoleillé et doux. Pas d'évolution du risque.

Pour consulter la vigilance en cours, veuillez vous rendre sur le site https://vigilance.meteofrance.fr/fr

Météo-France - 73 avenue de Paris, 94165 Saint-Mandé cedex - Contact : contact@meteo.fr

Rédigé par Météo-France avec la contribution des observateurs du réseau nivo-météorologiques. Partenariat : ANMSM (Maires de Stations de Montagne), DSF (Domaines Skiables de France), ADSP (Directeurs de Pistes et de la Sécurité des Stations de Sports d'Hiver) et autres acteurs de la montagne.

Bulletin neige & avalanches par téléphone au 0 892 68 10 20 Service 0,35 € / min + prix appel

RÉPUBLIQUE FRANÇAISE
Liberté Égalité Fraternité

METEO FRANCE
À VOS CÔTÉS, DANS UN CLIMAT QUI CHANGE

Bulletin d'estimation du risque d'avalanche
(valable en dehors des pistes balisées et ouvertes)

MASSIF : Oisans

Rédigé le jeudi 23 avril 2026 à 16h

Conditions nivo-météo des 7 derniers jours

	ven. 17/04				sam. 18/04				dim. 19/04				lun. 20/04				mar. 21/04				mer. 22/04				jeu. 23/04			
	03h	09h	15h	21h	03h	09h	15h	21h	03h	09h	15h	21h	03h	09h	15h	21h	03h	09h	15h	21h	03h	09h	15h	21h	03h	09h	15h	21h
Météo																												
Vent (km/h)	5	5	5	10	20	20	15	20	20	25	30	35	25	25	30	35	45	45	40	40	30	30	30	20	15	20	15	10
à 3500m																												
Vent (km/h)	10	15	5	0	10	5	0	10	10	15	20	20	10	15	20	20	30	35	30	20	15	15	20	10	10	10	10	10
à 2500m																												

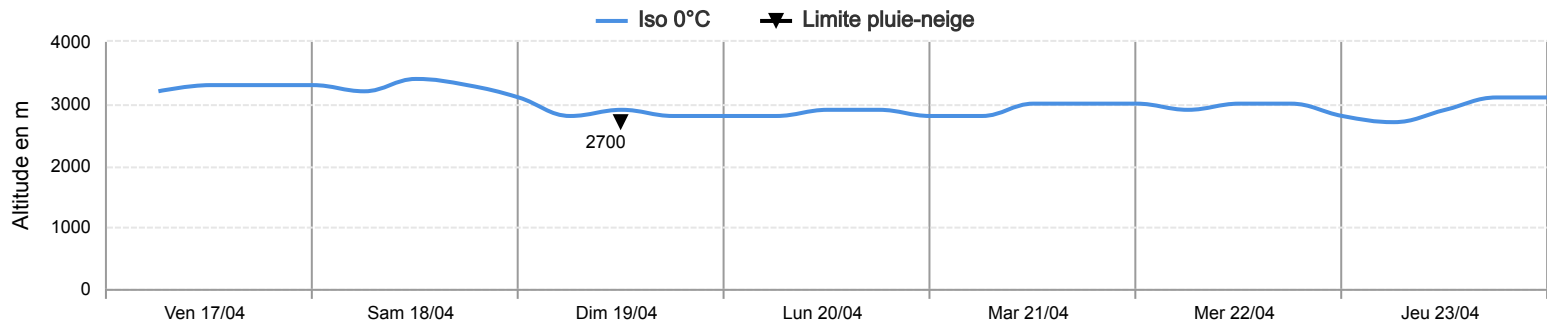

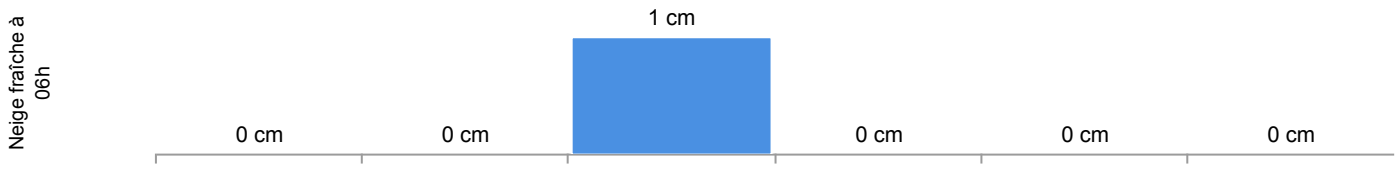

Risque d'avalanche	ven. 17/04	sam. 18/04	dim. 19/04	lun. 20/04	mar. 21/04	mer. 22/04	jeu. 23/04
	2	2	2	2	2	1	2

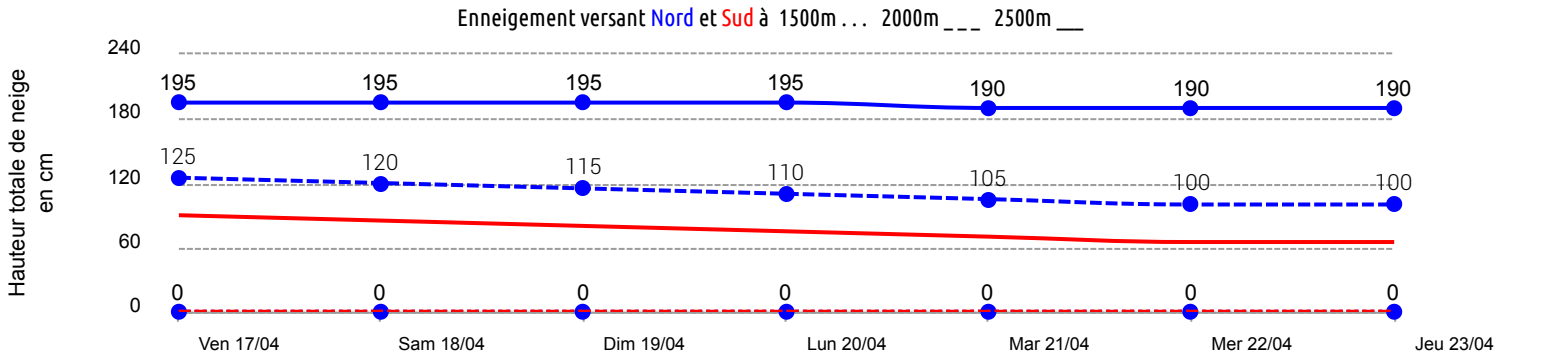

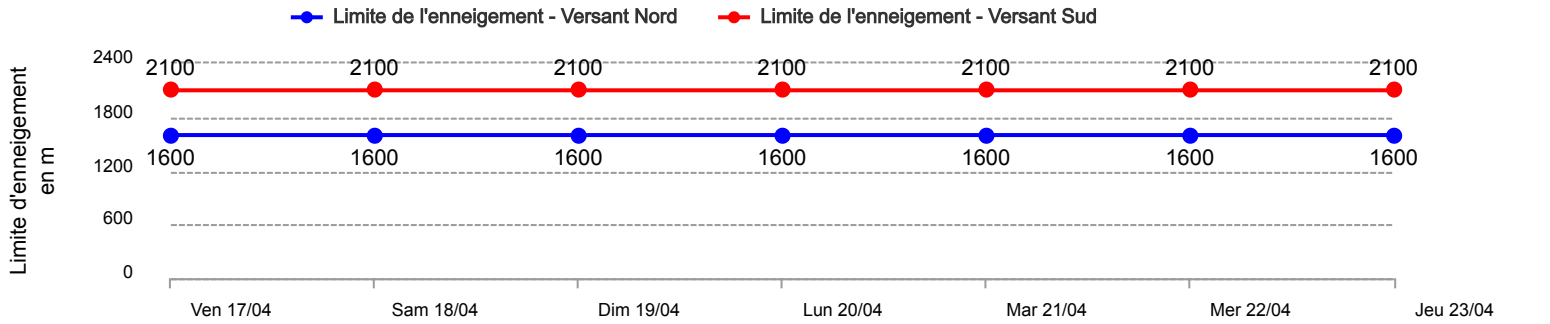

Pour consulter la vigilance en cours, veuillez vous rendre sur le site https://vigilance.meteofrance.fr/fr

Météo-France - 73 avenue de Paris, 94165 Saint-Mandé cedex - Contact : contact@meteo.fr

Rédigé par Météo-France avec la contribution des observateurs du réseau nivo-météorologiques. Partenariat : ANMSM (Maires de Stations de Montagne), DSF (Domaines Skiables de France), ADSP (Directeurs de Pistes et de la Sécurité des Stations de Sports d'Hiver) et autres acteurs de la montagne.

Bulletin neige & avalanches par téléphone au

0 892 68 10 20 Service 0,35 € / min + prix appel