Bulletin d'estimation du risque d'avalanche
(valable en dehors des pistes balisées et ouvertes)

MASSIF : Vercors

Rédigé le jeudi 23 avril 2026 à 16h

Estimation des risques pour le : VENDREDI 24 AVRIL

CONDITIONS PRINTANIERES, MANTEAU NEIGEUX STABLE

1

1

N O E S

Indice de risque faible.

Départs spontanés : Peu probables.

Déclenchements provoqués : Peu probables

Indices de risque : 5 très fort - 4 fort - 3 marqué - 2 limité - 1 faible -- En noir : les pentes les plus dangereuses

Stabilité du manteau neigeux

Situation avalancheuse typique : pas de situation prédominante

Déclenchements provoqués : Le manteau neigeux est dense et stable. Pas de risque de plaque. Risque éventuellement de faire partir une petite coulée ponctuelle de neige humide sous les skis, en pente raide ensoleillée.
Départs spontanés : Peu probables. Les conditions printanières des 3 dernières semaines ont purgé la plupart des pentes. Le risque de coulée humide ou de plaque de fond ne peut être totalement exclue mais devient franchement faible.

Qualité de la neige

Qualification de l'enneigement : L'enneigement s'est fortement réduit depuis 3 semaines et devient déficitaire pour la saison. Au Sud il ne reste plus que des névés...
Limites skiables : Vers 1400 à 1900m environ suivant l'exposition, la raideur de la pente...

Qualité de la neige vendredi : Manteau neigeux printanier. Regel nocturne correct. En journée l'humidification reprend, neige de névé, dense.

Aperçu météo pour le vendredi 24 avril

	nuit	matin	après-midi	soir
Pluie-Neige				
Iso 0 °C	2 900 m	3 100 m	3 100 m	3 200 m
Vent 1500 m	10 km/h	10 km/h	20 km/h	10 km/h
Vent 2000 m	15 km/h	20 km/h	20 km/h	10 km/h

Très belle journée ensoleillée, sous une grande douceur.

Épaisseur de neige hors-piste

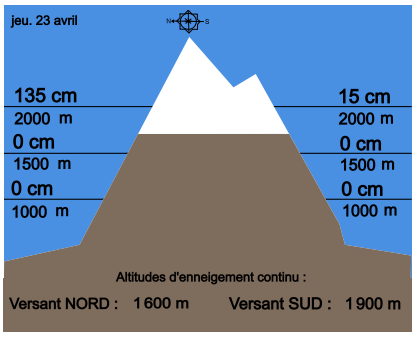

Précipitations à 1800 m

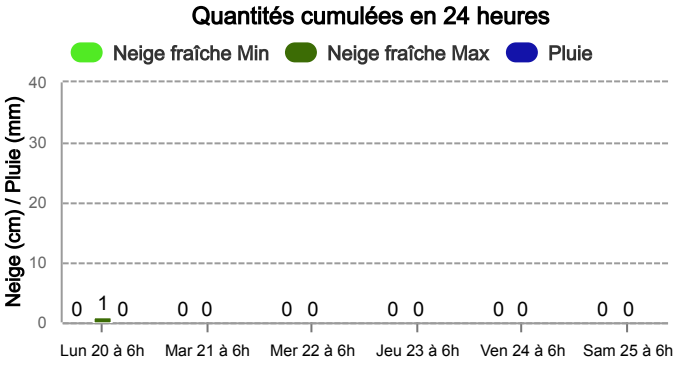

Tendance du samedi 25 avril

1

Indice de risque faible

Samedi, temps ensoleillé et doux. Pas d'évolution du risque.

Pour consulter la vigilance en cours, veuillez vous rendre sur le site https://vigilance.meteofrance.fr/fr

Météo-France - 73 avenue de Paris, 94165 Saint-Mandé cedex - Contact : contact@meteo.fr

Rédigé par Météo-France avec la contribution des observateurs du réseau nivo-météorologiques. Partenariat : ANMSM (Maires de Stations de Montagne), DSF (Domaines Skiables de France), ADSP (Directeurs de Pistes et de la Sécurité des Stations de Sports d'Hiver) et autres acteurs de la montagne.

Bulletin neige & avalanches par téléphone au 0 892 68 10 20 Service 0,35 € / min + prix appel

Bulletin d'estimation du risque d'avalanche

(valable en dehors des pistes balisées et ouvertes)

MASSIF : Vercors

Rédigé le jeudi 23 avril 2026 à 16h

Conditions nivo-météo des 7 derniers jours

	ven. 17/04				sam. 18/04				dim. 19/04				lun. 20/04				mar. 21/04				mer. 22/04				jeu. 23/04			
	03h	09h	15h	21h	03h	09h	15h	21h	03h	09h	15h	21h	03h	09h	15h	21h	03h	09h	15h	21h	03h	09h	15h	21h	03h	09h	15h	21h
Météo																												
Vent (km/h)	10	5	5	0	10	10	5	5	15	20	25	15	20	20	25	15	15	20	20	10	15	20	25	15	20	20	20	10
à 2000m																												
Vent (km/h)	5	5	5	5	5	5	10	0	15	20	20	10	10	20	25	10	10	20	25	10	10	15	20	10	10	15	20	10
à 1500m																												

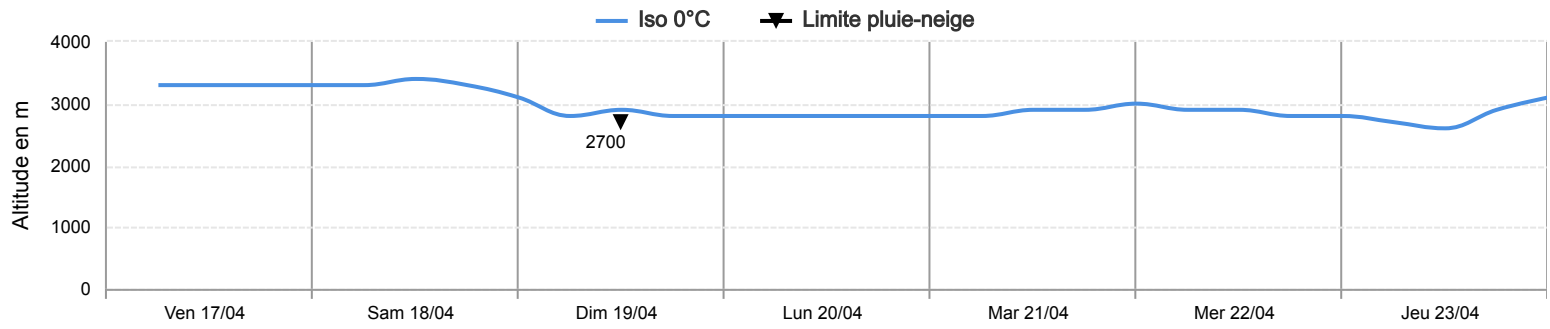

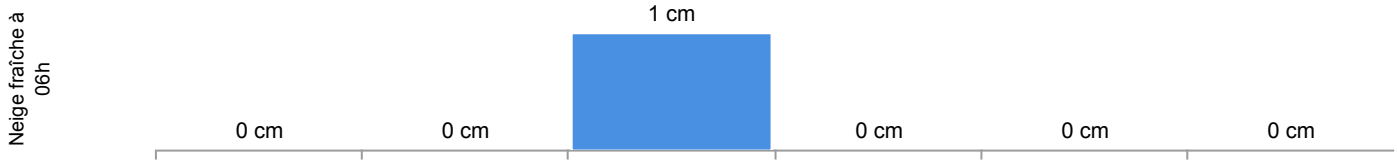

Risque d'avalanche	ven. 17/04	sam. 18/04	dim. 19/04	lun. 20/04	mar. 21/04	mer. 22/04	jeu. 23/04
	2	2	2	2	2	1	1

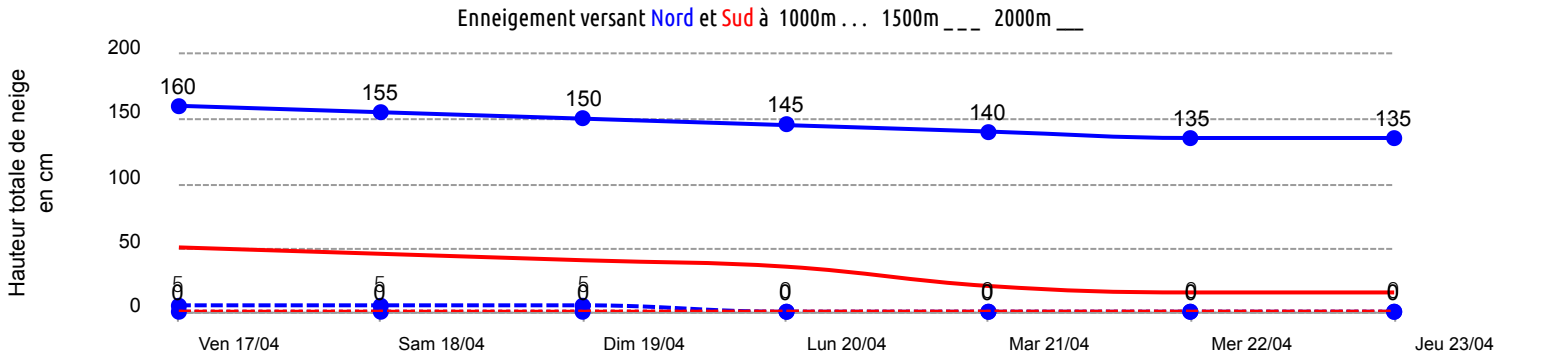

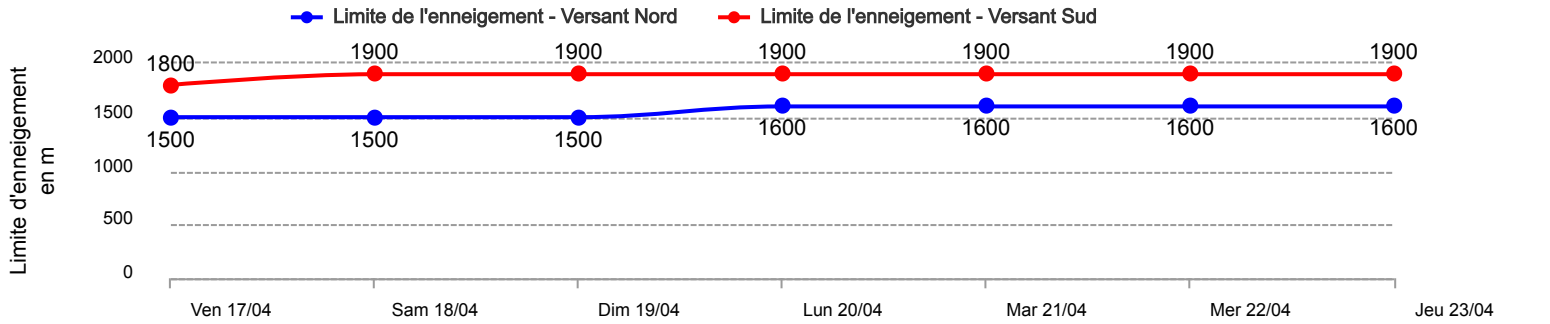

Pour consulter la vigilance en cours, veuillez vous rendre sur le site https://vigilance.meteofrance.fr/fr

Météo-France - 73 avenue de Paris, 94165 Saint-Mandé cedex - Contact : contact@meteo.fr

Rédigé par Météo-France avec la contribution des observateurs du réseau nivo-météorologiques. Partenariat : ANMSM (Maires de Stations de Montagne), DSF (Domaines Skiables de France), ADSP (Directeurs de Pistes et de la Sécurité des Stations de Sports d'Hiver) et autres acteurs de la montagne.

Bulletin neige & avalanches par téléphone au

0 892 68 10 20 Service 0,35 € / min + prix appel