GOBIERNO DE ESPAÑA
VICEPRESIDENCIA TERCERA DEL GOBIERNO
MINISTERIO PARA LA TRANSICIÓN ECOLÓGICA Y EL RETO DEMOGRÁFICO

Boletín de información nivológica y de peligro de aludes

Pirineo Navarro y Aragonés

aemet Agencia Estatal de Meteorología

viernes, 24 de abril de 2026

Pronóstico hasta las 24 horas del sábado, día 25 de abril

(Válido fuera de pistas de esquí balizadas y abiertas)

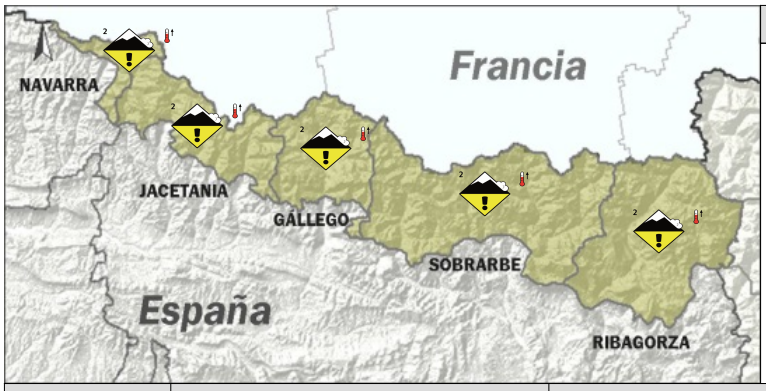

Problemas de aludes

Nieve húmeda

Deslizamientos basales

Macizo	Peligro	Problemas de aludes, cota, orientación, tamaño	Innivación observada (m)
Navarra	2 — 2 — Limitado	Nieve húmeda: 2 — N, O, E, S Deslizamientos basales: 2 — N, O, E, S	0000-00-00 N / S — Cota más baja caras N
Jacetania	2 — 2 — Limitado	Nieve húmeda: 2 — N, O, E, S Deslizamientos basales: 2 — N, O, E, S	0000-00-00 N / S — Cota más baja caras N
Gállego	2 — 2 — Limitado	Nieve húmeda: 2 — N, O, E, S Deslizamientos basales: 2 — N, O, E, S	0000-00-00 N / S — Cota más baja caras N

AEMET. Se autoriza la reproducción de su contenido citando la fuente.

Boletín de información nivológica y de peligro de aludes

Pirineo Navarro y Aragonés

Sobrarbe	2 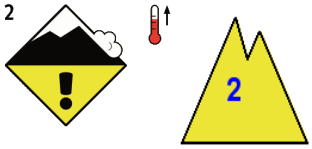 **Limitado**	**Nieve húmeda** 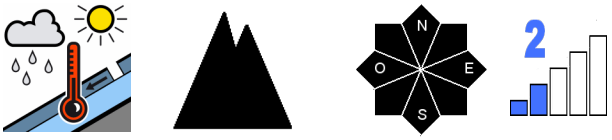 **Deslizamientos basales** 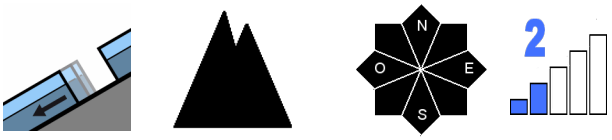	0000-00-00 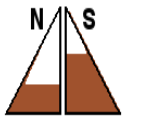 Cota más baja caras N
Ribagorza	2 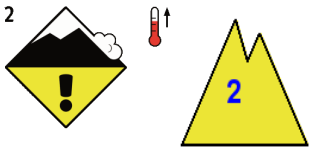 **Limitado**	**Nieve húmeda** **Deslizamientos basales** 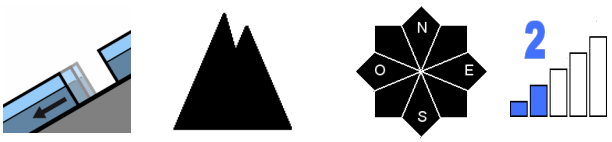	0000-00-00 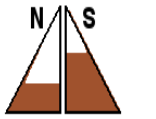 Cota más baja caras N

Estado del manto y observaciones recientes

Continúa el proceso de fusión y humidificación como consecuencia de las altas temperaturas, la insolación y los chubascos que se han ido produciendo cada tarde en forma de lluvia durante los últimos días, a excepción de ayer. Cada día se producen menguas de varios centímetros, y los afloramientos rocosos y las calvas son cada vez más extensas. El manto es discontinuo en solanas, aunque presenta cierta regularidad a partir de 2400 metros y, en umbrías, es continuo a partir de unos 2000-2100 metros. En la red de observación, a 2200 metros se puede superar el metro de espesor en algunas umbrías, mientras que en solanas aún puede haber algo de nieve en el suelo pero de manera muy dispersa. La nieve es típicamente primaveral, muy humedecida y con predominio de grano redondo, con rehielo nocturno débil, poco efectivo y prácticamente restringido a la alta montaña.

Evolución del manto y peligro de aludes para el sábado, día 25

Problema de nieve húmeda. Problema de deslizamientos basales.

Seguirá el ambiente cálido y la previsión de chubascos durante la segunda mitad del día, que continuarán propiciando la fusión y la humidificación del manto. Además, ascenderán algo más las temperaturas mínimas y apenas habrá rehielo nocturno efectivo en las zonas de mayor altitud de la cordillera. En consecuencia, desde media mañana se pueden producir purgas de nieve húmeda en laderas de cualquier orientación, con preferencia en las solanas y áreas afectadas por la lluvia, que podrán ser de tamaño pequeño (riesgo de caída) o localmente mediano (capaz de enterrar a una persona). También podrán darse algunos aludes de deslizamiento basal en laderas herbosas o de roca lisa con la suficiente inclinación, normalmente de tamaño mediano, aunque podrían adquirir dimensiones incluso grandes, magnitud suficiente como para arrastrar a un grupo de personas.

AEMET. Se autoriza la reproducción de su contenido citando la fuente.

Predicción meteorológica para el sábado, día 25

Poco nuboso o despejado por la mañana. A partir del mediodía, nuboso o con intervalos de nubosidad de evolución diurna. Chubascos durante la segunda mitad del día, acompañados de tormenta. Temperaturas mínimas en ascenso, ligero o moderado. Máximas sin apenas cambios. Soplarán vientos flojos de dirección variable, que podrán ser más intensos y racheados en áreas de chubascos o tormentas.

Datos en la atmósfera libre:

Altitud de la isoterma de 0 ºC: 3300 m
Altitud de la isoterma de -10 ºC: 4900 m

Viento a 1500 m: S 10 km/h
Viento a 3000 m: S 10 km/h

Evolución para el domingo día 26

Con pocos cambios.

(Información elaborada a partir de los datos recibidos de los refugios de Linza, Lizara, Respomuso, Panticosa, Bachimaña, Pineta, Estós y Angel Orús y de las estaciones de esquí de Astún, Formigal y Panticosa (lagos))

Escala europea de peligro de aludes

Débil | Limitado | Notable | Fuerte | Muy Fuerte

Problemas de aludes

Nieve reciente | Placas de viento | Capas débiles persistentes | Nieve húmeda | Deslizamientos basales | Sin problema evidente

Nota1: Se recuerda que, siempre que haya nieve, la ausencia total de peligro no existe. Hay que tener presente que en circunstancias desfavorables, con aludes de tamaño 1 (alud pequeño o colada) y tamaño 2 (alud mediano), se pueden sufrir severos daños personales.

Nota2: Los BPA se elaboran en base a información meteorológica así como al estado del manto nivoso a través de sondeos puntuales. Se advierte a los usuarios de la variabilidad de esta información al extrapolarla a zonas extensas de montaña. Por ello, AEMET no se hace responsable de su uso para la toma de decisiones que conciernen a la seguridad personal, ni de los riesgos físicos o materiales de ellas derivadas.

AEMET. Se autoriza la reproducción de su contenido citando la fuente.