Samstag 25.04.2026

Veröffentlicht am 24.04.2026 um 17:00

Vormittag

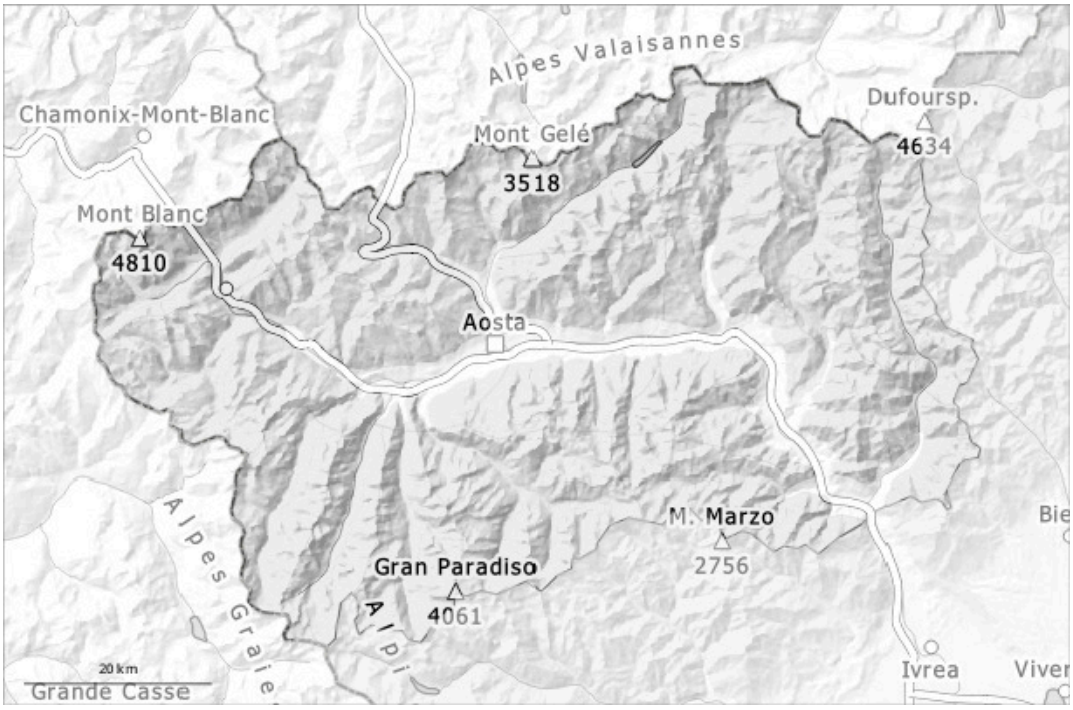

Nachmittag

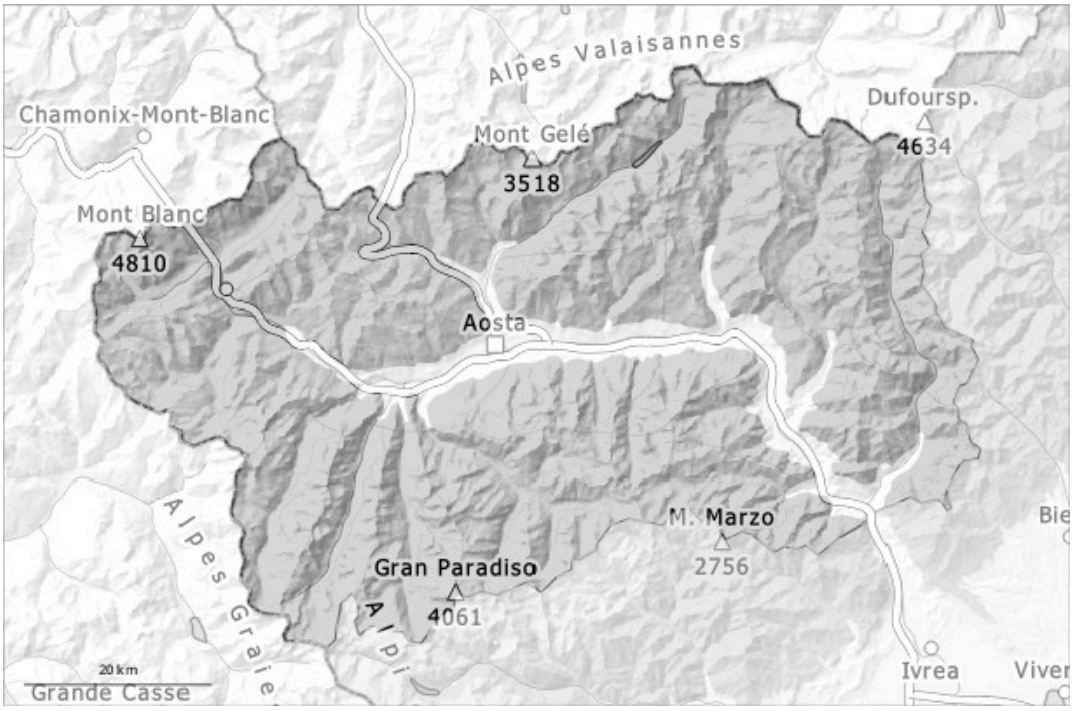

1	2	3	4	5
gering	mäßig	erheblich	groß	sehr groß

Gefahrenstufe 2 - Mäßig

AM:

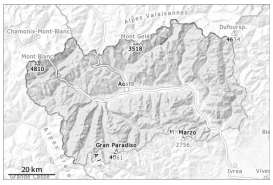

1

Tendenz: Lawinengefahr bleibt gleich
am Sonntag, den 26.04.2026

PM:

2

Tendenz: Lawinengefahr bleibt gleich
am Sonntag, den 26.04.2026

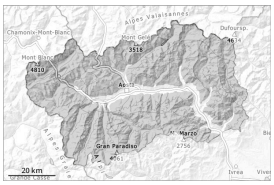

Nassschnee

2600m

Nassschnee

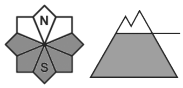

3300m

Die Gefahr von feuchten und nassen Lawinen steigt im Tagesverlauf rasch an.

Die Schneeoberfläche gefriert tragfähig und weicht rasch auf. Auf der harten Schneeoberfläche besteht im Steilgelände Absturzgefahr.
Mit der tageszeitlichen Erwärmung und der Sonneneinstrahlung steigt die Lawinengefahr im Tagesverlauf allmählich an. Es sind nasse Rutsche und Lawinen möglich, auch mittelgroße.
Dies vor allem an sehr steilen Nordhängen unterhalb von rund 2600 m und an sehr steilen Ost-, Süd- und Westhängen in der Höhe.
Touren und Hüttenaufstiege sollten früh gestartet und rechtzeitig beendet werden.

Schneedecke

Gefahrenmuster gm.10: frühjahrssituation

Mit starken Temperaturschwankungen verfestigte sich die Schneedecke. Dies vor allem an steilen Sonnenhängen in hohen Lagen und an allen Expositionen in mittleren Lagen.
Diese Situation führte unterhalb von rund 2700 m zu einer zunehmenden Anfeuchtung der Schneedecke.
Es liegen kleinräumig stark unterschiedliche Schneehöhen.
Besonders an Sonnenhängen unterhalb der Waldgrenze liegt kein Schnee. An Schattenhängen unterhalb der Waldgrenze liegt kaum Schnee.
Vor allem an den kälteren Hängen oberhalb der Baumgrenze, in den Talsen und auf den Landzungen, die in den letzten Wochen weniger von stürmischen Winden betroffen waren, herrscht eine ausgezeichnete Schneedecke.
Im unteren Teil der Schneedecke sind v.a. in hohen Lagen und im Hochgebirge Schwachschichten vorhanden.

Tendenz

Mit der tageszeitlichen Erwärmung sind unterhalb von rund 3300 m kleine und vereinzelt mittlere feuchte und nasse Lawinen möglich.