Bulletin d'estimation du risque d'avalanche
(valable en dehors des pistes balisées et ouvertes)

MASSIF : Beaufortain

Rédigé le vendredi 24 avril 2026 à 16h

Estimation des risques pour le : SAMEDI 25 AVRIL

L'HUMIDIFICATION EN PROFONDEUR CONTINUE.

2

1 → 2

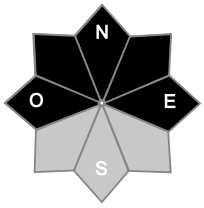

Indice de risque faible évoluant en limité.

Départs spontanés : rares départs en neige humide.

Déclenchements provoqués : peu probables sauf coulées humides sous les skis.

Indices de risque : 5 très fort - 4 fort - 3 marqué - 2 limité - 1 faible -- En noir : les pentes les plus dangereuses

Stabilité du manteau neigeux

Situation avalancheuse typique : neige humide

Départs spontanés :
- **Rares avalanches de neige humide** dans les **pentes ensoleillées**. Elles se produisent après quelques heures d'action du soleil, départs majoritairement ponctuels (coulées en "poires"), **petites à moyennes avalanches**. Les pentes sud sont d'avantage stabilisées en cette saison déjà bien avancée avec une neige dense de type névé sur toute l'épaisseur du manteau. En versants Est, Nord et Ouest, l'humidification gagne en profondeur. **Un rare départ linéaire est possible** si l'humidification atteint une couche fragile enfouie, exceptionnellement une grande avalanche.

Déclenchements provoqués : peu probables sauf avalanche de neige humide (pourrie) sous les skis en coupant une pente trop humidifiée.

Qualité de la neige

Enneigement : à peine correct pour la saison, la chaleur est durablement excessive et la neige fond à vue d'œil.

Limite skiable : vers 1500 m en nord, 1700/1800 m en sud en pente douce, bien plus haut en pente sud raide.

Qualité de la neige : neige de printemps après un bon regel nocturne. Neige dure aux premières heures du jour puis rapidement moquette de la matinée à la mi journée suivant orientations et altitudes. Neige pourrie rapidement le matin en versant Est et généralement partout après midi.

Aperçu météo pour le samedi 25 avril

	nuit	matin	après-midi	soir
Pluie-Neige				
Iso 0 °C	3 100 m	3 000 m	3 000 m	3 100 m
Vent 2000 m	5 km/h	15 km/h	20 km/h	5 km/h
Vent 3000 m	10 km/h	20 km/h	25 km/h	10 km/h

Largement ensoleillé, quelques petits cumulus et fin voile d'altitude dans l'après midi.

Épaisseur de neige hors-piste

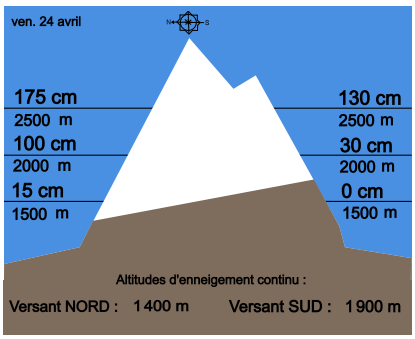

Précipitations à 1800 m

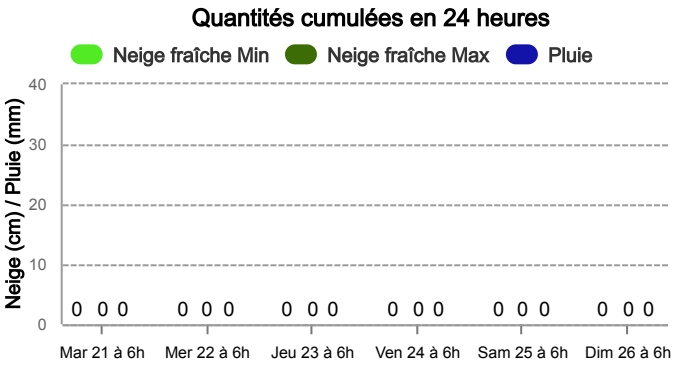

Tendance du dimanche 26 avril

2

Indice de risque limité

Conditions encore très printanières : risque croissant avec le réchauffement en journée.

Pour consulter la vigilance en cours, veuillez vous rendre sur le site https://vigilance.meteofrance.fr/fr

Météo-France - 73 avenue de Paris, 94165 Saint-Mandé cedex - Contact : contact@meteo.fr

Rédigé par Météo-France avec la contribution des observateurs du réseau nivo-météorologiques. Partenariat : ANMSM (Maires de Stations de Montagne), DSF (Domaines Skiables de France), ADSP (Directeurs de Pistes et de la Sécurité des Stations de Sports d'Hiver) et autres acteurs de la montagne.

Bulletin neige & avalanches par téléphone au 0 892 68 10 20 Service 0,35 € / min + prix appel

RÉPUBLIQUE FRANÇAISE
Liberté Égalité Fraternité

METEO FRANCE
À VOS CÔTÉS, DANS UN CLIMAT QUI CHANGE

Bulletin d'estimation du risque d'avalanche
(valable en dehors des pistes balisées et ouvertes)
MASSIF : Beaufortain

Rédigé le vendredi 24 avril 2026 à 16h

Conditions nivo-météo des 7 derniers jours

	sam. 18/04				dim. 19/04				lun. 20/04				mar. 21/04				mer. 22/04				jeu. 23/04				ven. 24/04			
	03h	09h	15h	21h	03h	09h	15h	21h	03h	09h	15h	21h	03h	09h	15h	21h	03h	09h	15h	21h	03h	09h	15h	21h	03h	09h	15h	21h
Météo																												
Vent (km/h)	20	15	15	15	20	20	20	20	30	25	25	25	25	15	15	20	25	25	15	10	10	20	15	10	5	15	20	10
à 3000m																												
Vent (km/h)	15	10	10	10	10	15	15	10	10	15	10	10	10	10	10	10	10	15	10	15	15	10	10	5	5	10	15	5
à 2000m																												

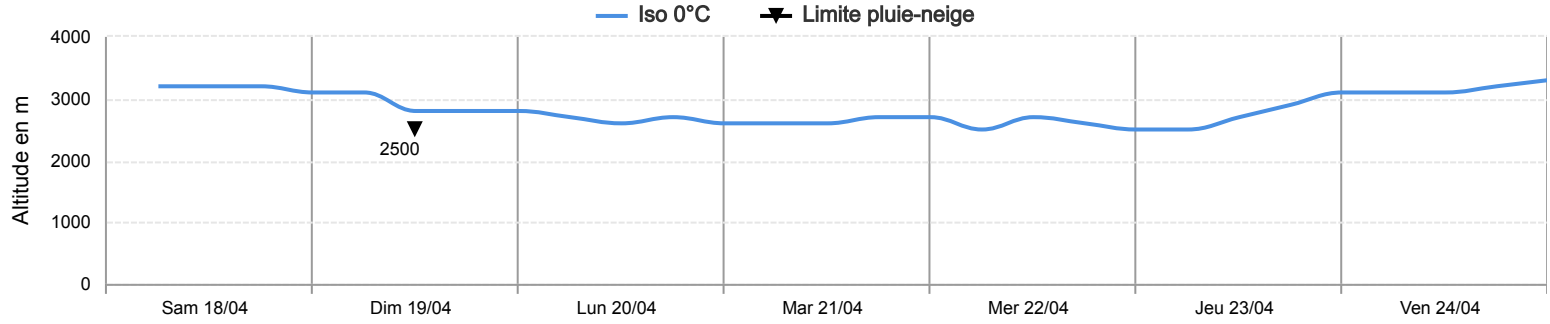

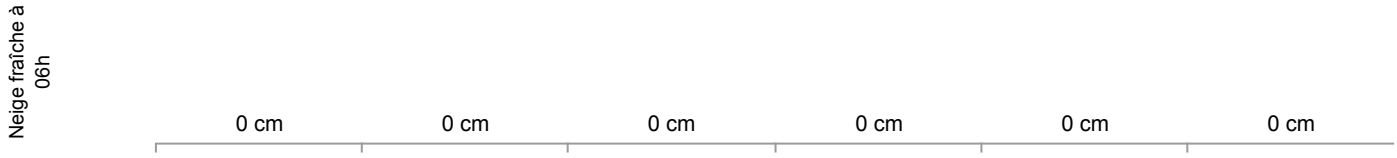

Risque d'avalanche	sam. 18/04	dim. 19/04	lun. 20/04	mar. 21/04	mer. 22/04	jeu. 23/04	ven. 24/04
	2	2	2	2	2	2	2

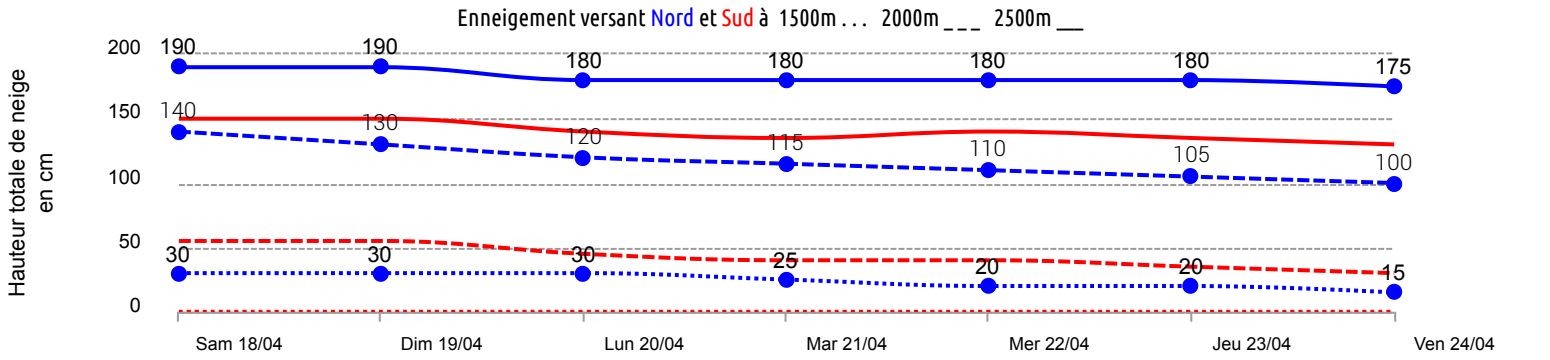

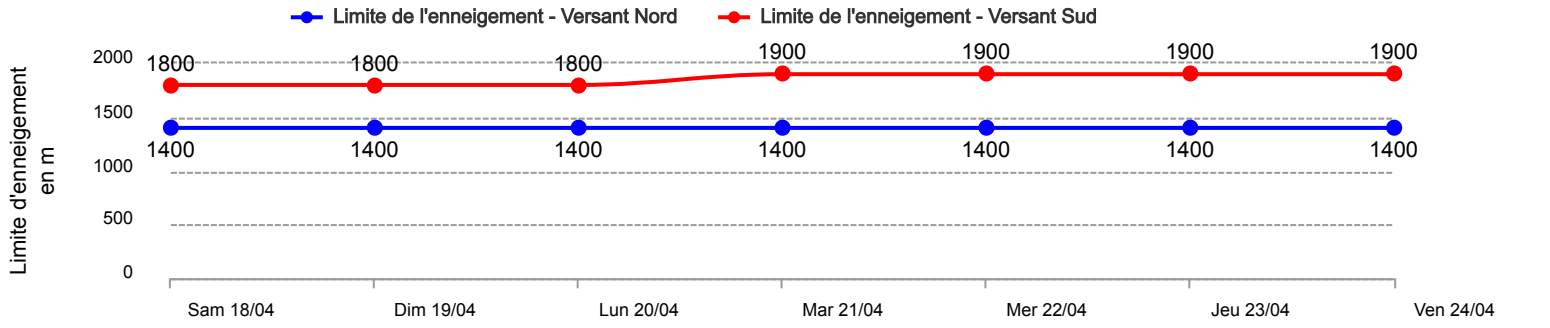

Pour consulter la vigilance en cours, veuillez vous rendre sur le site https://vigilance.meteofrance.fr/fr

Météo-France - 73 avenue de Paris, 94165 Saint-Mandé cedex - Contact : contact@meteo.fr

Rédigé par Météo-France avec la contribution des observateurs du réseau nivo-météorologiques. Partenariat : ANMSM (Maires de Stations de Montagne), DSF (Domaines Skiables de France), ADSP (Directeurs de Pistes et de la Sécurité des Stations de Sports d'Hiver) et autres acteurs de la montagne.

Bulletin neige & avalanches par téléphone au
0 892 68 10 20 Service 0,35 € / min + prix appel