RÉPUBLIQUE FRANÇAISE
Liberté Égalité Fraternité

METEO FRANCE
À VOS CÔTÉS, DANS UN CLIMAT QUI CHANGE

Bulletin d'estimation du risque d'avalanche
(valable en dehors des pistes balisées et ouvertes)

MASSIF : Champsaur

Rédigé le vendredi 24 avril 2026 à 16h

Estimation des risques pour le : SAMEDI 25 AVRIL

MANTEAU NEIGEUX PRINTANIER

2

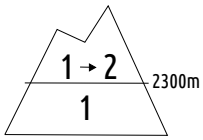

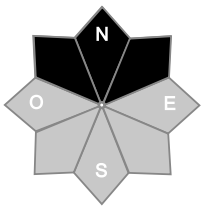

Au-dessus de 2300m indice de risque faible évoluant en limité, plus bas indice faible.

Départs spontanés : en neige humide.

Déclenchements provoqués : en neige humide.

Indices de risque : 5 très fort - 4 fort - 3 marqué - 2 limité - 1 faible -- En noir : les pentes les plus dangereuses

Stabilité du manteau neigeux

Situation avalancheuse typique : neige humide

Départs spontanés : peu probables en tout début de journée après un bon regel nocturne, puis quelques départs sont ensuite possibles avec la reprise de l'humidification sous l'effet de la chaleur et du bon ensoleillement. Départs ponctuels provoquant des avalanches de petite taille (taille 1) en général.
Une rare avalanche de taille moyenne à grande (taille 2 à 3) est possible sous forme de départ linéaire emportant la totalité du manteau neigeux, dans les pentes nord-ouest à nord-est au-dessus de 2300/2400 m environ, dans le cas où l'humidification atteint une couche fragile persistante enfouie dans le manteau neigeux.
En dessous de 2300 m environ, et dans les pentes sud jusqu'à haute altitude, le manteau neigeux printanier est désormais dense et bien stabilisé.

Déclenchements provoqués : un skieur coupant une pente raide tardivement peut initier un départ de neige humide sous les skis. Départ ponctuel engendrant une avalanche de petite taille (taille 1), plus rarement moyenne (taille 2).
Dans les orientation nord-ouest, nord et nord-est au-dessus de 2300/2400 m environ, une première avalanche superficielle de neige humide déclenchée par un skieur peut dans de rares cas provoquer un départ linéaire plus volumineux, en venant solliciter la couche fragile persistante enfouie dans le manteau neigeux, provoquant une avalanche de taille moyenne à grande (taille 2 à 3).

Qualité de la neige

Enneigement désormais déficitaire, notamment en adrets.
Hauteurs de neige observées : 57 cm à la nivôse d'Orcières à 2300 m.

Limite d'enneigement skiable : très localement vers 1600/1700 m en fond de vallée en cœur de massif, 2200/2400 m en adrets.

État de la neige de surface : manteau neigeux printanier, voire de névé en toute orientation sous 2300/2400 m environ et en adrets d'altitude. Bon regel nocturne, puis reprise de l'humidification avec le retour du soleil et de températures élevées.On trouve encore de la neige froide sur les glaciers ou en combes nord de haute altitude, au delà de 2900/3000 m.

Aperçu météo pour le samedi 25 avril

	nuit	matin	après-midi	soir
poursuite d'un temps calme, largement ensoleillé et chaud.				
Pluie-Neige				
Iso 0 °C	3 200 m	3 200 m	3 200 m	3 300 m
Vent 2000 m	5 km/h	5 km/h	20 km/h	5 km/h
Vent 3000 m	10 km/h	10 km/h	15 km/h	10 km/h

Épaisseur de neige hors-piste

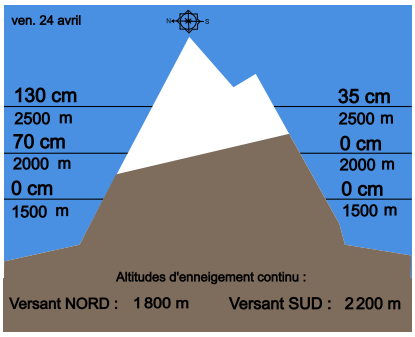

Précipitations à 1800 m

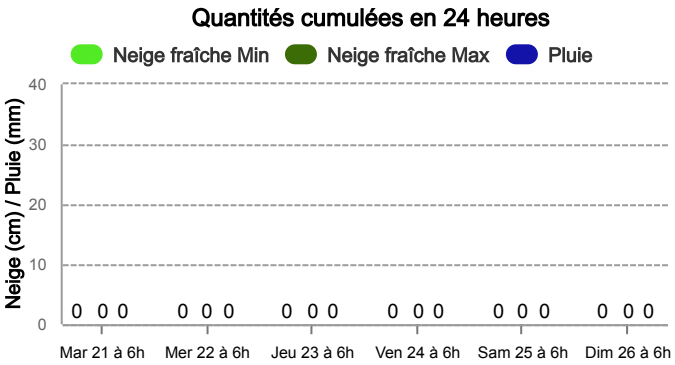

Tendance du dimanche 26 avril

2

Indice de risque limité

poursuite de l'humidification du manteau neigeux sous l'effet de la chaleur et du bon ensoleillement.

Pour consulter la vigilance en cours, veuillez vous rendre sur le site https://vigilance.meteofrance.fr/fr

Météo-France - 73 avenue de Paris, 94165 Saint-Mandé cedex - Contact : contact@meteo.fr

Rédigé par Météo-France avec la contribution des observateurs du réseau nivo-météorologiques. Partenariat : ANMSM (Maires de Stations de Montagne), DSF (Domaines Skiables de France), ADSP (Directeurs de Pistes et de la Sécurité des Stations de Sports d'Hiver) et autres acteurs de la montagne.

Bulletin neige & avalanches par téléphone au
0 892 68 10 20 Service 0,35 € / min + prix appel

RÉPUBLIQUE FRANÇAISE
Liberté Égalité Fraternité

METEO FRANCE
À VOS CÔTÉS, DANS UN CLIMAT QUI CHANGE

Bulletin d'estimation du risque d'avalanche

(valable en dehors des pistes balisées et ouvertes)

MASSIF : Champsaur

Rédigé le vendredi 24 avril 2026 à 16h

Conditions nivo-météo des 7 derniers jours

	sam. 18/04				dim. 19/04				lun. 20/04				mar. 21/04				mer. 22/04				jeu. 23/04				ven. 24/04			
	03h	09h	15h	21h	03h	09h	15h	21h	03h	09h	15h	21h	03h	09h	15h	21h	03h	09h	15h	21h	03h	09h	15h	21h	03h	09h	15h	21h
Météo																												
Vent (km/h)	10	10	15	10	15	20	25	20	20	20	25	20	20	20	25	20	20	25	25	15	20	15	15	15	15	10	10	10
à 3000m	→	↓	→	↘	↘	→	→	→	↓	→	→	↘	↘	→	→	→	→	→	→	↘	→	←	↖	↙	↙	↗	→	↘
Vent (km/h)	5	5	15	10	10	10	25	10	10	15	25	10	10	10	25	10	15	15	25	10	5	10	15	10	10	5	15	10
à 2000m	↓	↗	↘	←	↓	↘	↘	→	↓	↓	↘	↻	↓	→	↘	↓	↓	→	→	↓	←	←	→	←	↓	↑	→	←

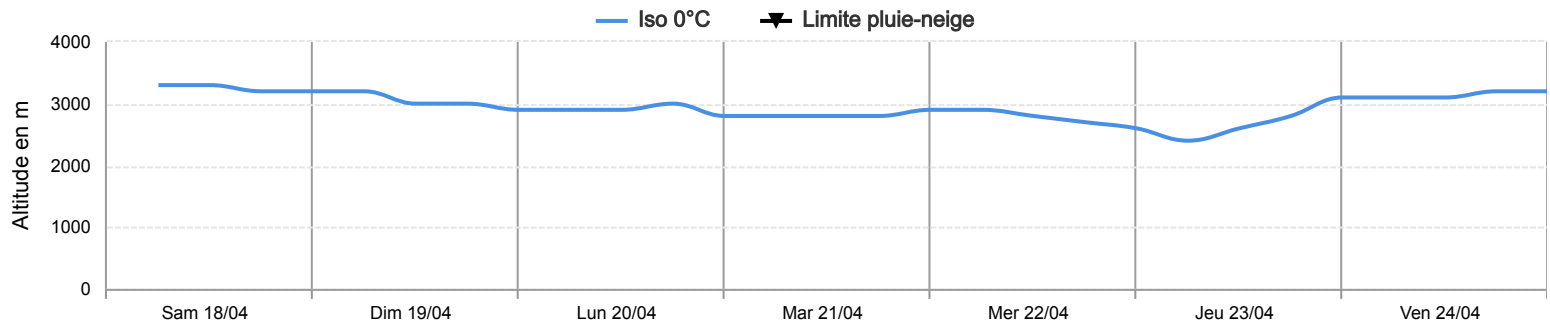

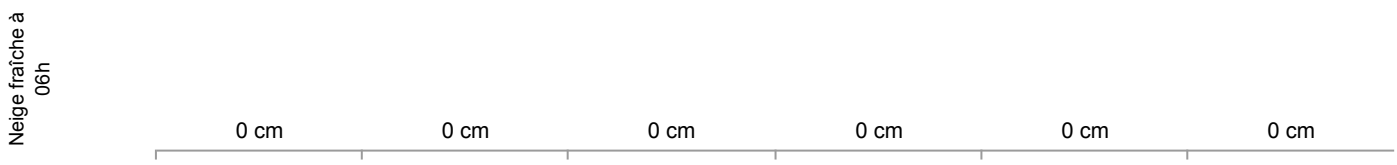

Risque d'avalanche	sam. 18/04	dim. 19/04	lun. 20/04	mar. 21/04	mer. 22/04	jeu. 23/04	ven. 24/04
	2	2	2	2	1	2	2

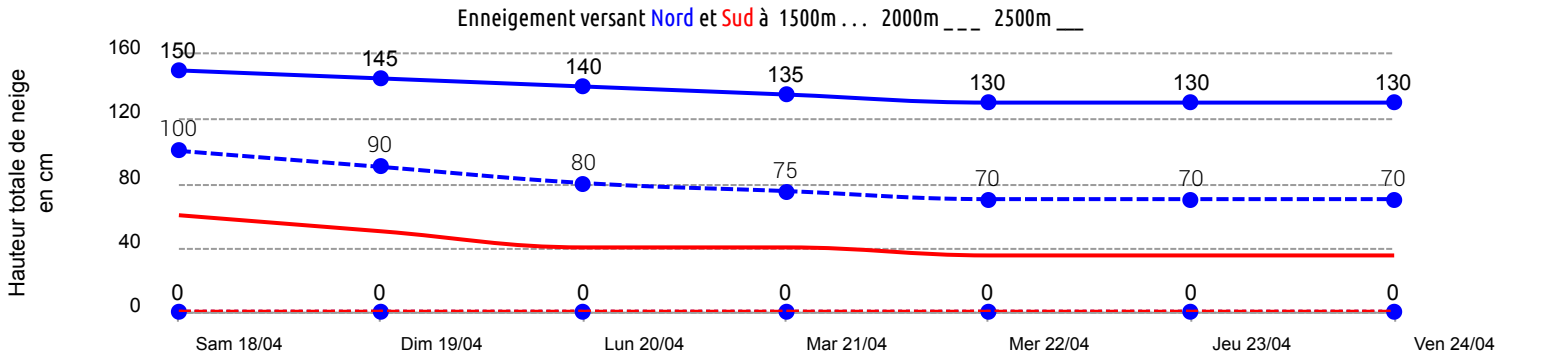

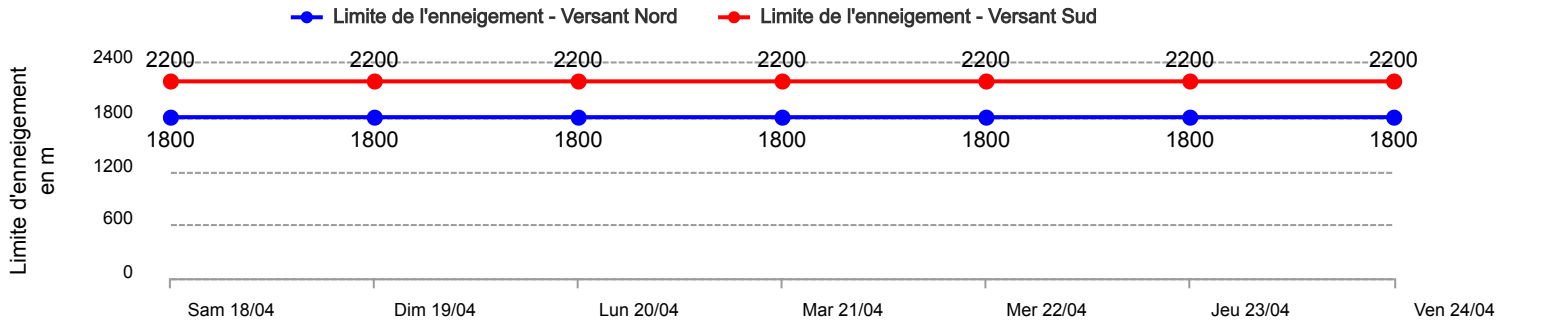

Pour consulter la vigilance en cours, veuillez vous rendre sur le site https://vigilance.meteofrance.fr/fr

Météo-France - 73 avenue de Paris, 94165 Saint-Mandé cedex - Contact : contact@meteo.fr

Rédigé par Météo-France avec la contribution des observateurs du réseau nivo-météorologiques. Partenariat : ANMSM (Maires de Stations de Montagne), DSF (Domaines Skiables de France), ADSP (Directeurs de Pistes et de la Sécurité des Stations de Sports d'Hiver) et autres acteurs de la montagne.

Bulletin neige & avalanches par téléphone au
0 892 68 10 20 Service 0,35 € / min + prix appel