Bulletin d'estimation du risque d'avalanche
(valable en dehors des pistes balisées et ouvertes)

MASSIF : Chartreuse

Rédigé le vendredi 24 avril 2026 à 16h

Estimation des risques pour le : SAMEDI 25 AVRIL

CONDITIONS PRINTANIERES, MANTEAU NEIGEUX TRES DENSE, STABLE..

1

1

Très rares

Indice de risque faible.

Départs spontanés : Peu probables.

Déclenchements provoqués : Non, attention le matin aux surfaces durcies par regel.

Indices de risque : 5 très fort - 4 fort - 3 marqué - 2 limité - 1 faible -- En noir : les pentes les plus dangereuses

Stabilité du manteau neigeux

Situation avalancheuse typique : pas de situation prédominante

De moins en moins de neige en place et très dense, presque de névé, donc stable...
Départs spontanés : Peu probables. Suite au redoux prolongé, la neige a bien diminuée et devient très dense, stable même lorsqu'elle est humide en journée. Noter aussi du regel nocturne/samedi marin
RAS ou très rare coulée en pente bien raide ?
Déclenchements provoqués : Pas de risque de plaque.

Autres : Surfaces temporairement durcies par regel nocturne, surfaces glissantes parfois.

Qualité de la neige

Qualification de l'enneigement : L'enneigement s'est fortement réduit depuis 3 semaines et devient déficitaire pour la saison. Au Sud il ne reste plus que de rares névés... la fin de saison approche.
Limites skiables : Vers 1500 à 1900m environ suivant l'exposition, la raideur de la pente...

Qualité de la neige samedi : Manteau printanier avec du relief. Regel nocturne correct. En journée l'humidification et la fonte reprennent, neige très humide, mais dense.

Aperçu météo pour le samedi 25 avril

	nuit	matin	après-midi	soir
Pluie-Neige				
Iso 0 °C	3 200 m	2 900 m	3 000 m	3 000 m
Vent 1500 m	10 km/h	15 km/h	20 km/h	10 km/h
Vent 2000 m	15 km/h	15 km/h	20 km/h	10 km/h

Beau temps calme et sec. Regel nocturne correct puis rapide redoux en journée. Quelques voiles élevés l'après-midi.

Épaisseur de neige hors-piste

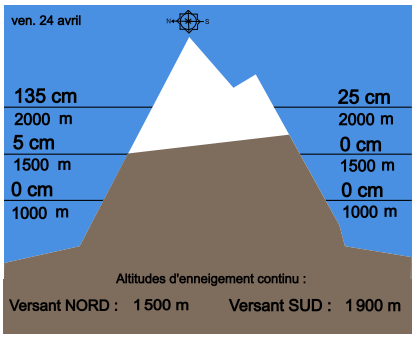

Précipitations à 1800 m

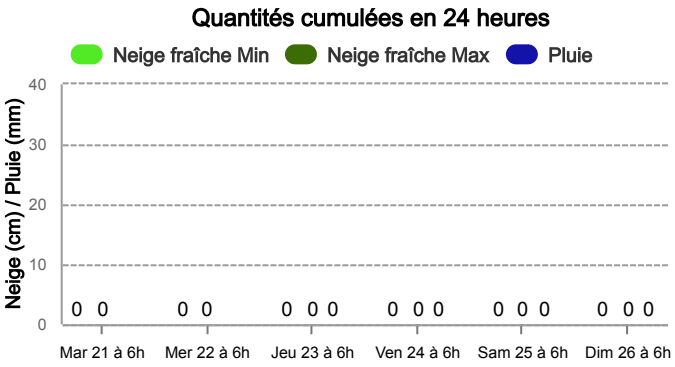

Tendance du dimanche 26 avril

1

Indice de risque faible

Pas d'évolution dimanche. Un peu de regel puis fonte en journée.

Pour consulter la vigilance en cours, veuillez vous rendre sur le site https://vigilance.meteofrance.fr/fr

Météo-France - 73 avenue de Paris, 94165 Saint-Mandé cedex - Contact : contact@meteo.fr

Rédigé par Météo-France avec la contribution des observateurs du réseau nivo-météorologiques. Partenariat : ANMSM (Maires de Stations de Montagne), DSF (Domaines Skiables de France), ADSP (Directeurs de Pistes et de la Sécurité des Stations de Sports d'Hiver) et autres acteurs de la montagne.

Bulletin neige & avalanches par téléphone au 0 892 68 10 20 Service 0,35 € / min + prix appel

Bulletin d'estimation du risque d'avalanche

(valable en dehors des pistes balisées et ouvertes)

MASSIF : Chartreuse

Rédigé le vendredi 24 avril 2026 à 16h

Conditions nivo-météo des 7 derniers jours

	sam. 18/04				dim. 19/04				lun. 20/04				mar. 21/04				mer. 22/04				jeu. 23/04				ven. 24/04			
	03h	09h	15h	21h	03h	09h	15h	21h	03h	09h	15h	21h	03h	09h	15h	21h	03h	09h	15h	21h	03h	09h	15h	21h	03h	09h	15h	21h
Météo																												
Vent (km/h)	5	10	5	5	10	10	25	20	15	10	10	15	10	5	10	10	10	15	10	5	5	15	10	15	10	5	5	10
à 2000m																												
Vent (km/h)	10	10	5	0	10	15	20	10	5	15	20	10	10	15	20	10	10	15	20	10	10	15	15	10	10	10	15	10
à 1500m																												

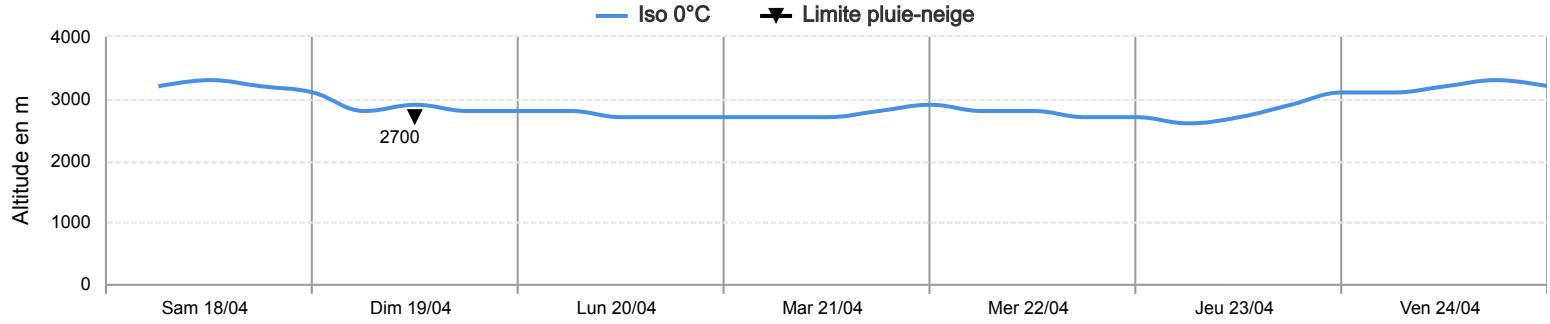

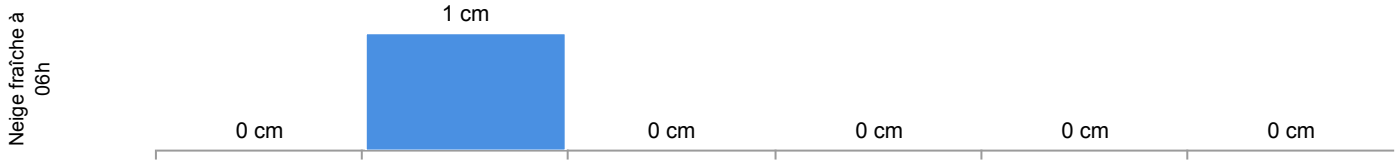

Risque d'avalanche	sam. 18/04	dim. 19/04	lun. 20/04	mar. 21/04	mer. 22/04	jeu. 23/04	ven. 24/04
	2	2	2	2	1	1	1

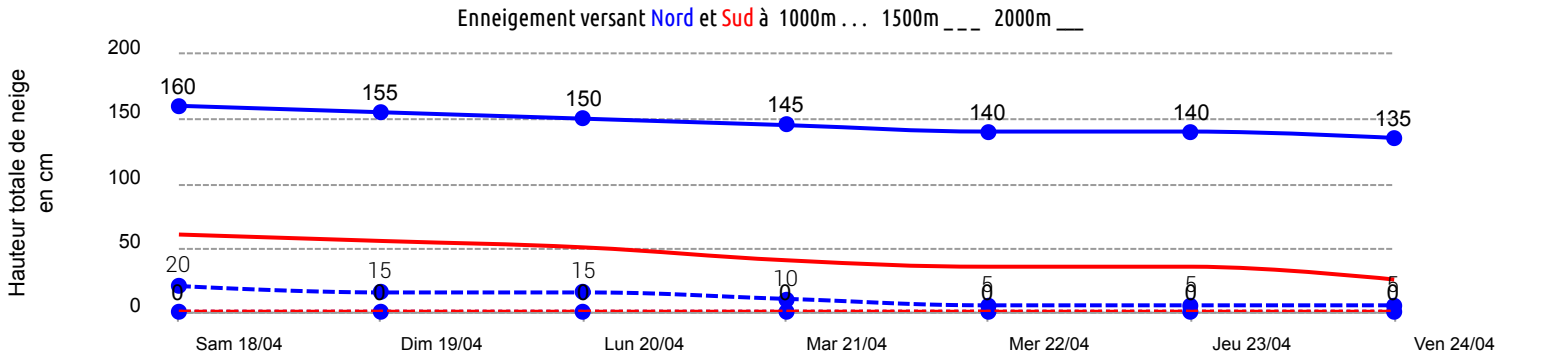

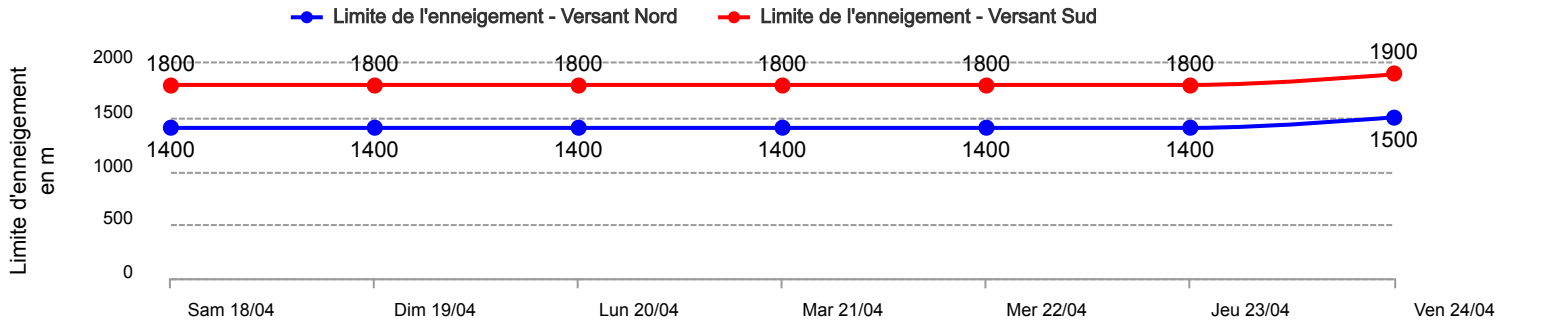

Pour consulter la vigilance en cours, veuillez vous rendre sur le site https://vigilance.meteofrance.fr/fr

Météo-France - 73 avenue de Paris, 94165 Saint-Mandé cedex - Contact : contact@meteo.fr

Bulletin neige & avalanches par téléphone au 0 892 68 10 20 Service 0,35 € / min + prix appel

Rédigé par Météo-France avec la contribution des observateurs du réseau nivo-météorologiques. Partenariat : ANMSM (Maires de Stations de Montagne), DSF (Domaines Skiables de France), ADSP (Directeurs de Pistes et de la Sécurité des Stations de Sports d'Hiver) et autres acteurs de la montagne.