Bulletin d'estimation du risque d'avalanche

(valable en dehors des pistes balisées et ouvertes)

MASSIF : Haute-Bigorre

Rédigé le vendredi 24 avril 2026 à 16h

Estimation des risques pour le : SAMEDI 25 AVRIL

ACTIVITÉ POSSIBLE DÈS LE MATIN, GRANDES AVALANCHES POSSIBLES

3

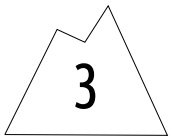

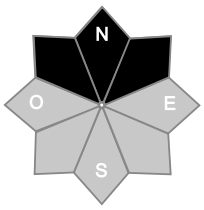

Rares mais grandes

Indices de risque : 5 très fort - 4 fort - 3 marqué - 2 limité - 1 faible -- En noir : les pentes les plus dangereuses

Indice de risque marqué.

Départs spontanés : GRANDES AVALANCHES VOIRE RARES TRES GRANDES POSSIBLES A FORT IMPACT

Déclenchements provoqués : COULEES

Stabilité du manteau neigeux

Situation avalancheuse typique : neige humide avalanches de fond

Départs spontanés :
RISQUE 3 NATUREL EN PENTES RAIDES en versant nord à Nord-Est pour les **avalanches de fond moyennes à grandes nombreuses à de rares très grandes mais pouvant avoir un fort impact car s'écoulant alors plus bas que la limite d'enneigement,** possiblement sur les sentiers. Elles se déroulent sous forme de blocs rapides, roulants et se détachant ou en masse s'écoulant lentement mais puissamment. Les densités de neige étant proches du maximum possible. Ces avalanches de fond partent en général d'une des **nombreuses fissures déjà ouvertes** sur les faces Nord à Nord-est. Les épaisseurs en jeu dans ces secteurs dépassent partout le mètre voire plus de 2 ou 3 m. Dans les autres expositions, les accumulations sont moindres et le manteau est plus tassé, moins instable.
Les zones de départs se situent plutôt au-dessus de 2300/2500 m.
Avec un manteau humidifié, regelant à peine en surface, en haute montagne, des départs ponctuels de taille petite à moyenne sont attendus même tôt le matin et deviennent nombreux au cours de la journée.

Déclenchements provoqués :
En expositions nord moins stabilisées par tassement, coulées possibles sous les skis en raison du manque de consistance de la neige en journée par l'effet du soleil.

Autres : **Corniches et ponts de neige encore en place extrêmement peu résistants**, pouvant céder dès le matin sous le poids d'une seule personne ou bien spontanément.
Une avalanche de l'heure précédente ou des jours récents, peut être suivie d'une autre coulée au même endroit, **suravalanches** possibles.

Qualité de la neige

Enneigement : plutôt bon pour la saison et débutant encore vers 1800 m en nord et au-dessus de 2150 m en sud.
Les limites de cet enneigement remontent progressivement dans la douceur ambiante, sous les éclaircies matinales et les quelques averses de l'après-midi.
État de la neige : Le manteau neigeux subit la longue période de douceur. Il peut être portant et ressaisi au-dessus de 2400 m au lever du jour mais évolue très vite et devient très mou au soleil en journée avec parfois des **enfoncements importants dans une neige sans consistance en après-midi.**

Aperçu météo pour le samedi 25 avril

	nuit	matin	après-midi	soir

Temps nuageux sous 1800 m, soleil au-dessus avec des cumulus en après-midi et des averses, potentiellement orageuses.

Pluie-Neige	2 900 m	2 700 m	2 900 m	
Iso 0 °C	3 300 m	3 200 m	3 200 m	3 200 m
Vent 2000 m	↑ 5 km/h	← 10 km/h	← 15 km/h	↑ 5 km/h
Vent 3000 m	↘ 10 km/h	↑ 10 km/h	↓ 15 km/h	↑ 10 km/h

Épaisseur de neige hors-piste

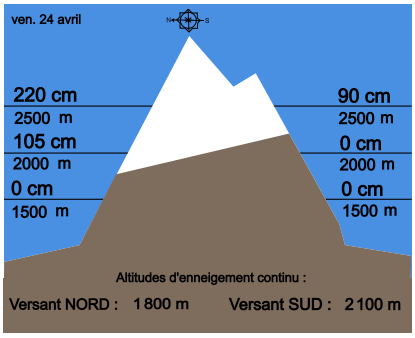

Précipitations à 1800 m

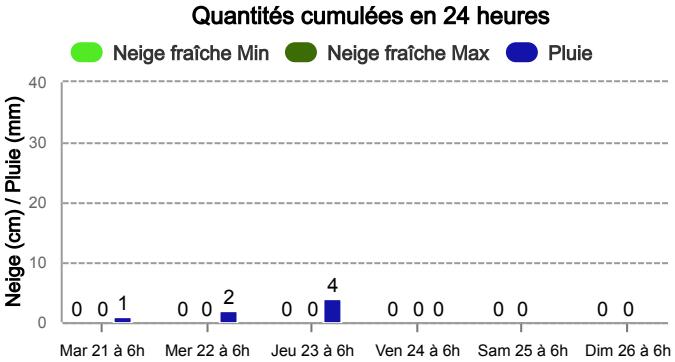

Tendance du dimanche 26 avril

3

Indice de risque marqué

Risques maintenus.

Pour consulter la vigilance en cours, veuillez vous rendre sur le site https://vigilance.meteofrance.fr/fr

Météo-France - 73 avenue de Paris, 94165 Saint-Mandé cedex - Contact : contact@meteo.fr

Bulletin neige & avalanches par téléphone au **0 892 68 10 20** Service 0,35 € / min + prix appel

Rédigé par Météo-France avec la contribution des observateurs du réseau nivo-météorologiques. Partenariat : ANMSM (Maires de Stations de Montagne), DSF (Domaines Skiables de France), ADSP (Directeurs de Pistes et de la Sécurité des Stations de Sports d'Hiver) et autres acteurs de la montagne.

RÉPUBLIQUE FRANÇAISE
Liberté Égalité Fraternité

METEO FRANCE
À VOS CÔTÉS, DANS UN CLIMAT QUI CHANGE

Bulletin d'estimation du risque d'avalanche

(valable en dehors des pistes balisées et ouvertes)

MASSIF : Haute-Bigorre

Rédigé le vendredi 24 avril 2026 à 16h

Conditions nivo-météo des 7 derniers jours

	sam. 18/04				dim. 19/04				lun. 20/04				mar. 21/04				mer. 22/04				jeu. 23/04				ven. 24/04			
	03h	09h	15h	21h	03h	09h	15h	21h	03h	09h	15h	21h	03h	09h	15h	21h	03h	09h	15h	21h	03h	09h	15h	21h	03h	09h	15h	21h
Météo																												
Vent (km/h)	15	10	15	20	25	20	20	25	25	20	55	25	20	30	40	55	45	40	25	20	35	25	25	15	25	15	20	10
à 3000m																												
Vent (km/h)	10	5	15	15	15	15	15	10	5	10	15	5	5	10	10	15	35	25	20	15	20	15	20	15	15	15	15	10
à 2000m																												

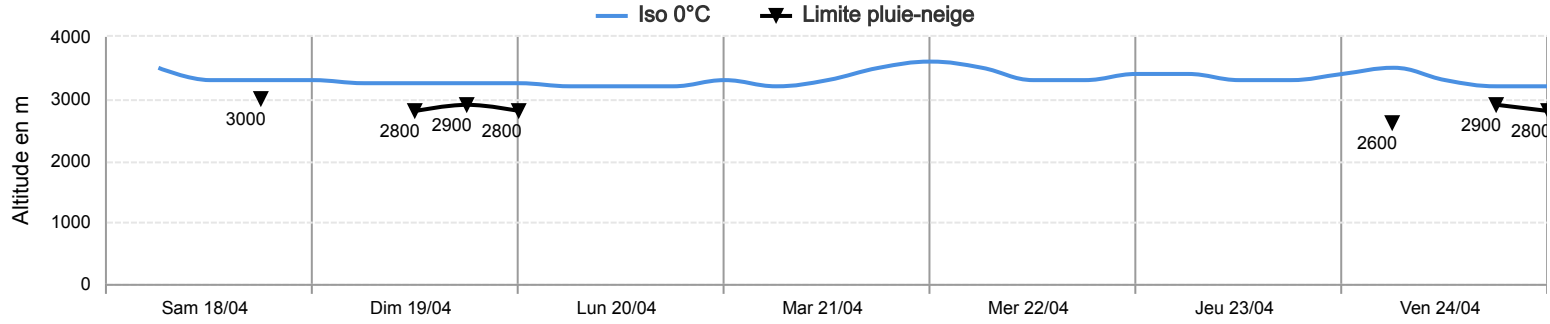

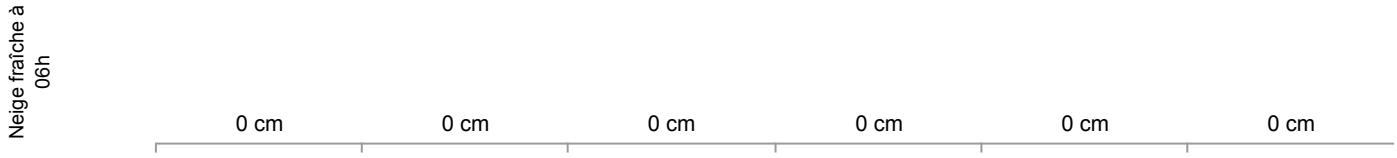

Risque d'avalanche	sam. 18/04	dim. 19/04	lun. 20/04	mar. 21/04	mer. 22/04	jeu. 23/04	ven. 24/04
	2	2	2	2	3	3	3

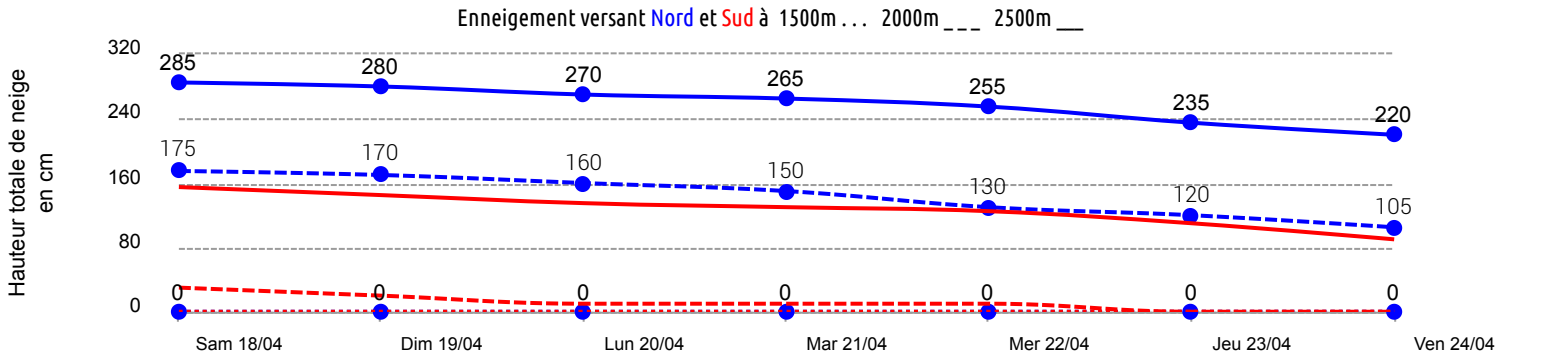

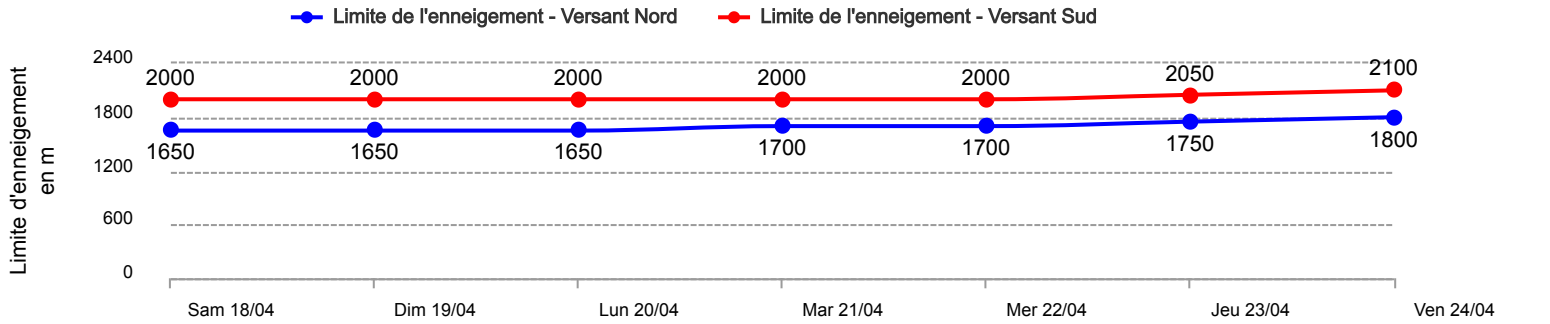

Pour consulter la vigilance en cours, veuillez vous rendre sur le site https://vigilance.meteofrance.fr/fr

Météo-France - 73 avenue de Paris, 94165 Saint-Mandé cedex - Contact : contact@meteo.fr

Rédigé par Météo-France avec la contribution des observateurs du réseau nivo-météorologiques. Partenariat : ANMSM (Maires de Stations de Montagne), DSF (Domaines Skiables de France), ADSP (Directeurs de Pistes et de la Sécurité des Stations de Sports d'Hiver) et autres acteurs de la montagne.

Bulletin neige & avalanches par téléphone au
0 892 68 10 20 Service 0,35 € / min + prix appel