RÉPUBLIQUE FRANÇAISE
Liberté Égalité Fraternité

METEO FRANCE
À VOS CÔTÉS, DANS UN CLIMAT QUI CHANGE

Bulletin d'estimation du risque d'avalanche
(valable en dehors des pistes balisées et ouvertes)
MASSIF : Haute-Maurienne

Rédigé le vendredi 24 avril 2026 à 16h

Estimation des risques pour le : SAMEDI 25 AVRIL

L'HUMIDIFICATION EN PROFONDEUR CONTINUE.

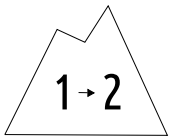

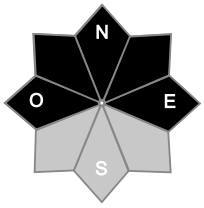

Indice de risque faible évoluant en limité.

Départs spontanés : rares mais potentiellement grands départs en neige humide.

Déclenchements provoqués : neige humide sous les skis.

Indices de risque : 5 très fort - 4 fort - 3 marqué - 2 limité - 1 faible -- En noir : les pentes les plus dangereuses

Stabilité du manteau neigeux

Situation avalancheuse typique : neige humide

Départs spontanés :
- **Rares avalanches de neige humide** dans les **pentes ensoleillées**. Départs ponctuels (coulées en "poires") désormais plus petits et rares, **petites avalanches**. Les pentes sud sont d'avantage stabilisées en cette saison déjà bien avancée avec une neige dense de type névé sur toute l'épaisseur du manteau. En versants Est, Nord et Ouest, l'humidification gagne en profondeur. **Un rare départ linéaire est possible** si l'humidification atteint une couche fragile enfouie, exceptionnellement une grande avalanche. De même, un rare départ en cascade est possible si une petite coulée humide sollicite une couche fragile, cassure linéaire et potentiellement grande avalanche.

Déclenchements provoqués : peu probables sauf avalanche de neige humide (pourrie) sous les skis en coupant une pente trop humidifiée.
- En plein Nord de haute altitude (>3000 m), une très rare plaque en neige froide peut subsister. Observable : couche enfouie moins dense qu'en surface.

Autres : chutes de corniches signalées.

Qualité de la neige

Enneigement : déficitaire pour la saison, la chaleur est durablement excessive et la neige fond à vue d'œil.

Limite skiable : vers 1700 m en nord, 2000 m en sud en pente douce, bien plus haut en pente sud raide.

Qualité de la neige : neige de printemps après un bon regel nocturne. Neige dure aux premières heures du jour puis rapidement moquette de la matinée à la mi journée suivant orientations et altitudes. Neige pourrie rapidement le matin en versant Est et généralement partout après midi. Il faut monter au-dessus de 3000 m en plein Nord pour trouver de la neige froide souvent poudreuse.

Aperçu météo pour le samedi 25 avril

nuit	matin	après-midi	soir

Largement ensoleillé, quelques petits cumulus et fin voile d'altitude dans l'après midi.

Pluie-Neige				
Iso 0 °C	3 300 m	3 200 m	3 100 m	3 200 m
Vent 2500 m	↘ 5 km/h	↘ 15 km/h	→ 20 km/h	↘ 5 km/h
Vent 3500 m	↖ 10 km/h	→ 20 km/h	↓ 25 km/h	↓ 10 km/h

Épaisseur de neige hors-piste

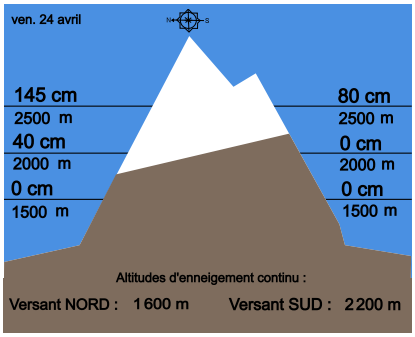

Précipitations à 1800 m

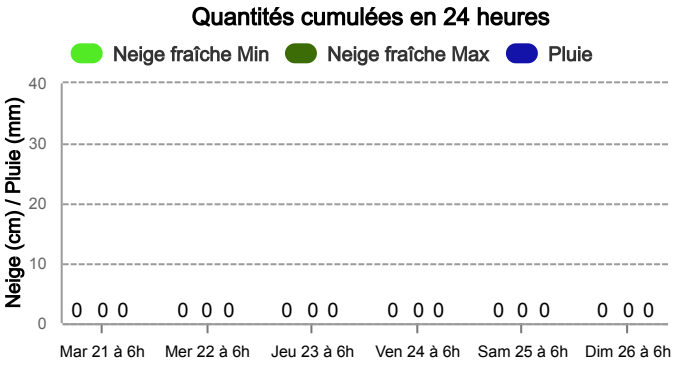

Tendance du dimanche 26 avril

Indice de risque limité

Conditions encore très printanières : risque croissant avec le réchauffement en journée.

Pour consulter la vigilance en cours, veuillez vous rendre sur le site https://vigilance.meteofrance.fr/fr

Météo-France - 73 avenue de Paris, 94165 Saint-Mandé cedex - Contact : contact@meteo.fr

Rédigé par Météo-France avec la contribution des observateurs du réseau nivo-météorologiques. Partenariat : ANMSM (Maires de Stations de Montagne), DSF (Domaines Skiables de France), ADSP (Directeurs de Pistes et de la Sécurité des Stations de Sports d'Hiver) et autres acteurs de la montagne.

Bulletin neige & avalanches par téléphone au
0 892 68 10 20 Service 0,35 € / min + prix appel

RÉPUBLIQUE FRANÇAISE
Liberté Égalité Fraternité

METEO FRANCE
À VOS CÔTÉS, DANS UN CLIMAT QUI CHANGE

Bulletin d'estimation du risque d'avalanche
(valable en dehors des pistes balisées et ouvertes)
MASSIF : Haute-Maurienne

Rédigé le vendredi 24 avril 2026 à 16h

Conditions nivo-météo des 7 derniers jours

	sam. 18/04				dim. 19/04				lun. 20/04				mar. 21/04				mer. 22/04				jeu. 23/04				ven. 24/04			
	03h	09h	15h	21h	03h	09h	15h	21h	03h	09h	15h	21h	03h	09h	15h	21h	03h	09h	15h	21h	03h	09h	15h	21h	03h	09h	15h	21h
Météo																												
Vent (km/h)	20	15	15	15	20	30	30	25	25	40	40	40	40	30	35	30	35	35	20	15	15	25	25	15	10	5	20	10
à 3500m																												
Vent (km/h)	15	10	10	10	15	20	25	20	20	25	20	25	20	20	20	15	20	25	15	10	10	15	15	10	5	5	15	5
à 2500m																												

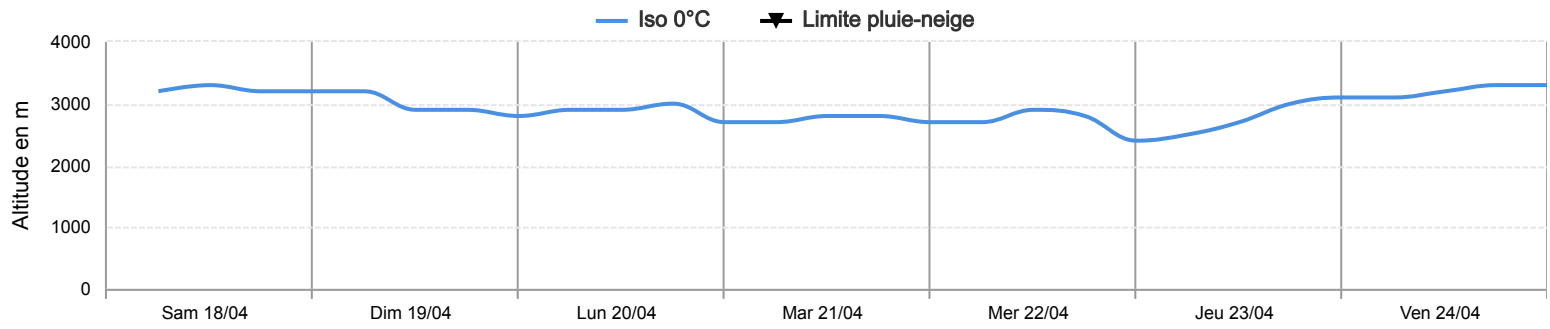

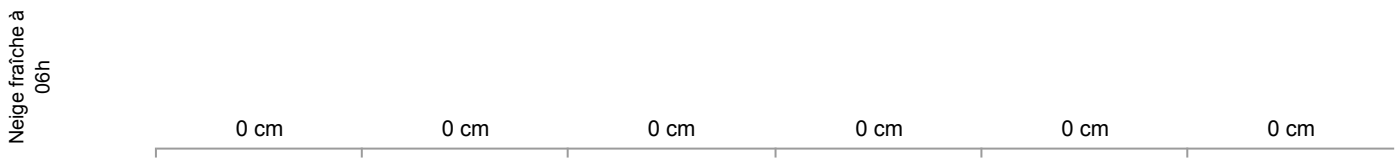

Risque d'avalanche	sam. 18/04	dim. 19/04	lun. 20/04	mar. 21/04	mer. 22/04	jeu. 23/04	ven. 24/04
	2	2	2	2	2	2	2

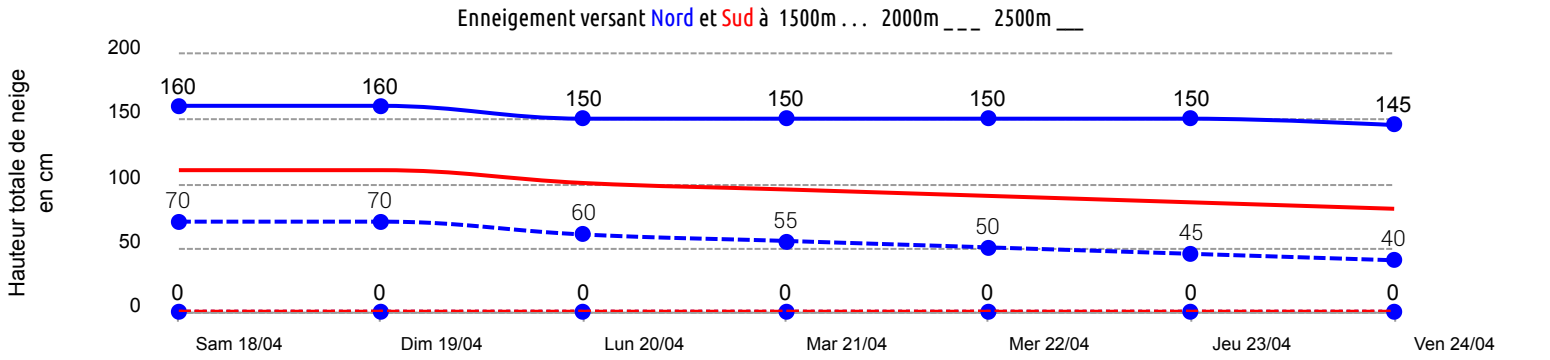

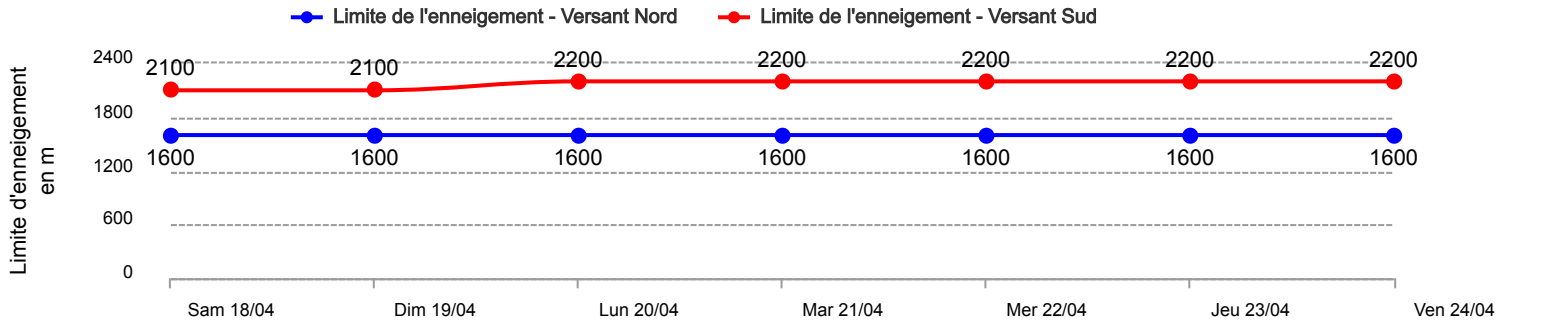

Pour consulter la vigilance en cours, veuillez vous rendre sur le site https://vigilance.meteofrance.fr/fr

Météo-France - 73 avenue de Paris, 94165 Saint-Mandé cedex - Contact : contact@meteo.fr

Bulletin neige & avalanches par téléphone au
0 892 68 10 20 Service 0,35 € / min + prix appel

Rédigé par Météo-France avec la contribution des observateurs du réseau nivo-météorologiques. Partenariat : ANMSM (Maires de Stations de Montagne), DSF (Domaines Skiables de France), ADSP (Directeurs de Pistes et de la Sécurité des Stations de Sports d'Hiver) et autres acteurs de la montagne.