Bulletin d'estimation du risque d'avalanche
(valable en dehors des pistes balisées et ouvertes)

MASSIF : Pays-Basque

Rédigé le vendredi 24 avril 2026 à 16h

Estimation des risques pour le : SAMEDI 25 AVRIL

HUMIDIFICATION EN PROFONDEUR.

1

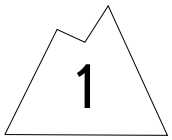

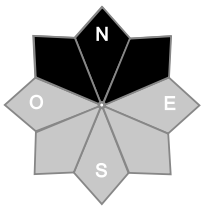

Peu de regel

Indice de risque faible.

Départs spontanés : En neige humide, quelques avalanches de fond.

Déclenchements provoqués : En neige humide.

Indices de risque : 5 très fort - 4 fort - 3 marqué - 2 limité - 1 faible -- En noir : les pentes les plus dangereuses

Stabilité du manteau neigeux

Situation avalancheuse typique : neige humide

Départs spontanés : manteau neigeux humidifié sur toute son épaisseur, **pas de regel nocturne.**
Activité faible mais déjà possible en fin de nuit et début de matinée, puis, dans la douceur ambiante, sous le soleil du matin et sous les quelques averses de l'après-midi, manteau neigeux très humide à gorgé d'eau, favorable à quelques départs ponctuels qur les quelques pentes raides encore enneigées, souvent de petite taille. Quelques avalanches de fond ou de glissement de taille moyenne encore possibles au plus doux et au plus humide de la journée, partant des quelques accumulations encore en place au plus haut du massif vers le secteur de la Pierre-Saint-Martin.
Aucune orientation ne sera épargnée, départs à proximité des rochers, des zones déneigées et des nombreuses fissures ouvertes.

Déclenchements provoqués : en neige humide exclusivement.
Au passage d'**un skieur ou randonneur**, **déclenchement aisé** de **neige très humide à gorgée d'eau**, **chassant en coulées** sur le haut du massif, dans le **secteur de la Pierre-Saint-Martin** essentiellement.

Autres : corniches et ponts de neige encore en place extrêmement peu résistants, pouvant céder dès le matin sous le poids d'une seule personne.

Qualité de la neige

Enneigement : Encore correct autour de l'Anie, débutant vers 1800 m en nord et de rares névés en sud.
Les limites de cet enneigement remontent dans la douceur ambiante, sous les éclaircies matinales et les quelques averses de l'après-midi. Enneigement par places, rares langues éparses en allant vers l'ouest (pic d'Orhy).
État de la neige : pas de regel nocturne, manteau neigeux humidifié sur toute son épaisseur, humide et peu portant au lever du jour, devenant rapidement gorgé d'eau au soleil et très mou au cours de la journée.

Aperçu météo pour le samedi 25 avril

	nuit	matin	après-midi	soir
	1800 m			

Temps nuageux sous 1800 m, soleil au-dessus avec des cumulus en après-midi et des averses, potentiellement orageuses.

	nuit	matin	après-midi	soir
Pluie-Neige	2 800 m	2 800 m		
Iso 0 °C	3 200 m	3 100 m	3 200 m	3 300 m
Vent 1000 m	10 km/h	10 km/h	10 km/h	5 km/h
Vent 2000 m	20 km/h	15 km/h	15 km/h	15 km/h

Épaisseur de neige hors-piste

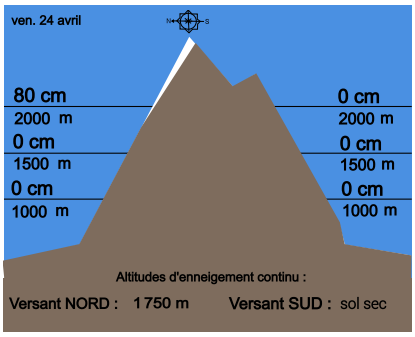

Précipitations à 1800 m

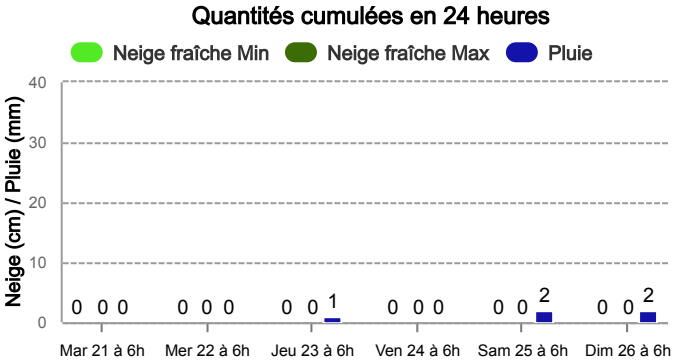

Tendance du dimanche 26 avril

1

Indice de risque faible

Risques maintenus.

Pour consulter la vigilance en cours, veuillez vous rendre sur le site https://vigilance.meteofrance.fr/fr

Météo-France - 73 avenue de Paris, 94165 Saint-Mandé cedex - Contact : contact@meteo.fr

Rédigé par Météo-France avec la contribution des observateurs du réseau nivo-météorologiques. Partenariat : ANMSM (Maires de Stations de Montagne), DSF (Domaines Skiables de France), ADSP (Directeurs de Pistes et de la Sécurité des Stations de Sports d'Hiver) et autres acteurs de la montagne.

Bulletin neige & avalanches par téléphone au
0 892 68 10 20 Service 0,35 € / min + prix appel

RÉPUBLIQUE FRANÇAISE
Liberté Égalité Fraternité

METEO FRANCE
À VOS CÔTÉS, DANS UN CLIMAT QUI CHANGE

Bulletin d'estimation du risque d'avalanche

(valable en dehors des pistes balisées et ouvertes)

MASSIF : Pays-Basque

Rédigé le vendredi 24 avril 2026 à 16h

Conditions nivo-météo des 7 derniers jours

	sam. 18/04				dim. 19/04				lun. 20/04				mar. 21/04				mer. 22/04				jeu. 23/04				ven. 24/04			
	03h	09h	15h	21h	03h	09h	15h	21h	03h	09h	15h	21h	03h	09h	15h	21h	03h	09h	15h	21h	03h	09h	15h	21h	03h	09h	15h	21h
Météo																												
Vent (km/h)	20	15	15	20	25	25	25	30	30	25	35	30	25	30	35	55	70	50	25	20	35	30	25	65	70	60	20	15
à 2000m																												
Vent (km/h)	5	10	10	10	10	15	15	15	5	5	15	10	10	10	10	15	40	30	25	10	10	20	20	40	50	40	15	10
à 1000m																												

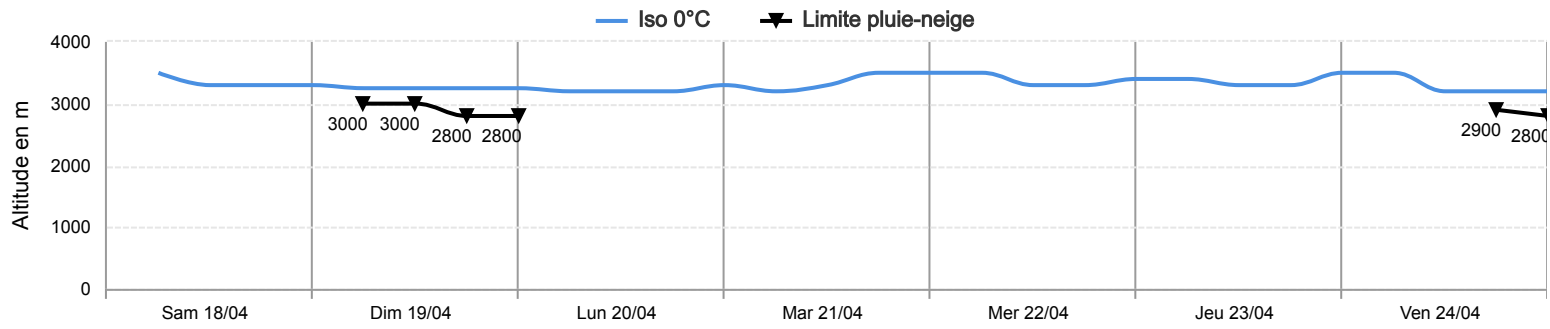

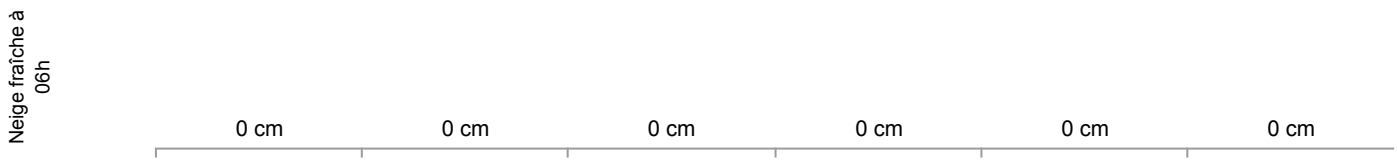

Risque d'avalanche	sam. 18/04	dim. 19/04	lun. 20/04	mar. 21/04	mer. 22/04	jeu. 23/04	ven. 24/04
	2	2	2	2	2	2	2

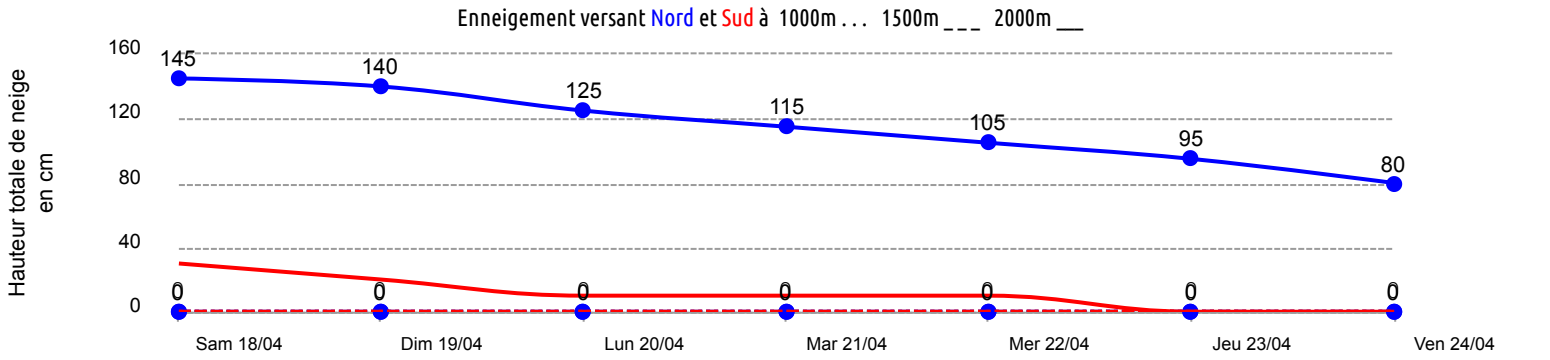

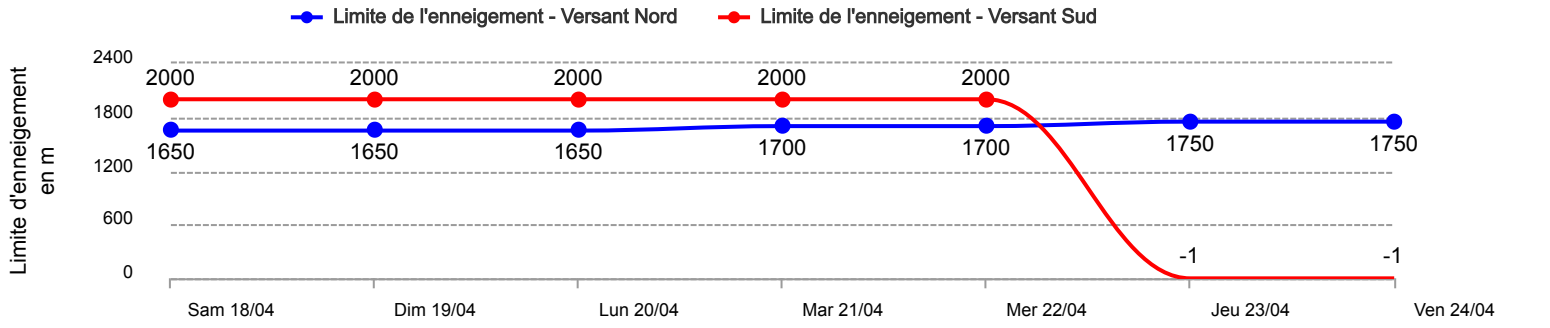

Pour consulter la vigilance en cours, veuillez vous rendre sur le site https://vigilance.meteofrance.fr/fr

Météo-France - 73 avenue de Paris, 94165 Saint-Mandé cedex - Contact : contact@meteo.fr

Bulletin neige & avalanches par téléphone au

0 892 68 10 20 Service 0,35 € / min + prix appel

Rédigé par Météo-France avec la contribution des observateurs du réseau nivo-météorologiques. Partenariat : ANMSM (Maires de Stations de Montagne), DSF (Domaines Skiables de France), ADSP (Directeurs de Pistes et de la Sécurité des Stations de Sports d'Hiver) et autres acteurs de la montagne.