GOBIERNO DE ESPAÑA
VICEPRESIDENCIA TERCERA DEL GOBIERNO
MINISTERIO PARA LA TRANSICIÓN ECOLÓGICA Y EL RETO DEMOGRÁFICO

Boletín de información nivológica y de peligro de aludes

Pirineo Navarro y Aragonés

aemet Agencia Estatal de Meteorología

sábado, 25 de abril de 2026

Pronóstico hasta las 24 horas del domingo, día 26 de abril

(Válido fuera de pistas de esquí balizadas y abiertas)

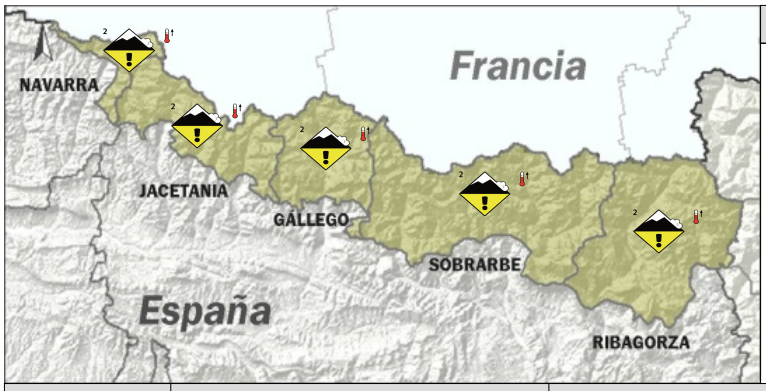

Problemas de aludes

Nieve húmeda

Deslizamientos basales

Macizo	Peligro	Problemas de aludes, cota, orientación, tamaño	Innivación observada (m)
Navarra	2 — 2 — Limitado	Nieve húmeda: 1 — N, O, E, S Deslizamientos basales: 2 — N, O, E, S	2026-04-25 N / S Cota más baja caras N
Jacetania	2 — 2 — Limitado	Nieve húmeda: 2 — N, O, E, S Deslizamientos basales: 2 — N, O, E, S	2026-04-25 N / S Cota más baja caras N
Gállego	2 — 2 — Limitado	Nieve húmeda: 2 — N, O, E, S Deslizamientos basales: 2 — N, O, E, S	2026-04-25 N / S Cota más baja caras N

AEMET. Se autoriza la reproducción de su contenido citando la fuente.

Boletín de información nivológica y de peligro de aludes

Pirineo Navarro y Aragonés

Sobrarbe	2 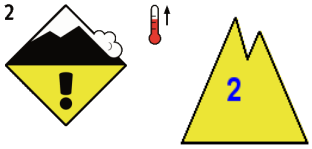 **Limitado**	**Nieve húmeda** 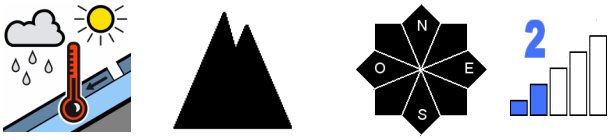 **Deslizamientos basales** 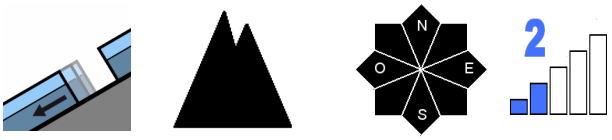	2026-04-25 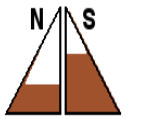 Cota más baja caras N
Ribagorza	2 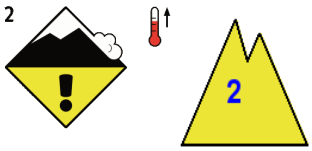 **Limitado**	**Nieve húmeda** **Deslizamientos basales** 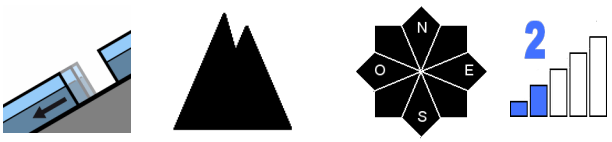	2026-04-25 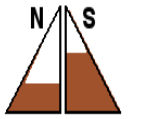 Cota más baja caras N

Estado del manto y observaciones recientes

Un día más, la insolación, las temperaturas elevadas y la ocurrencia de algunos chubascos vespertinos han continuado los procesos de merma y humidificación del manto nivoso. Este se halla básicamente restringido a las cotas altas y presenta una clara asimetría norte-sur, con solanas muy discontinuas. En cuanto a los espesores, pese al claro retroceso, todavía se reportan valores superiores a 80-100 cm en umbrías por encima de 2200 metros. La nieve está muy humidificada, con predominio del grano redondo y el enfriamiento nocturno no permite un rehielo efectivo.

Evolución del manto y peligro de aludes para el domingo, día 26

Problema de nieve húmeda. Problema de deslizamientos basales.

Ya desde media mañana se podrán producir algunos aludes de nieve húmeda en laderas lo suficientemente inclinadas. El peligro aumentará a lo largo de la tarde con la insolación y las posibles precipitaciones. Estos aludes podrán ser naturales o accidentales y de tamaño pequeño, localmente mediano.

También podrán podrá producirse algún deslizamiento basal en laderas herbosas o de roca lisa con la suficiente inclinación, normalmente de tamaño mediano, aunque no se descarta que pueda adquirir una dimensión mayor.

Predicción meteorológica para el domingo, día 26

Pirineo navarro:
Poco nuboso o despejado salvo por la tarde, cuando se desarrollará nubosidad de evolución diurna. No se descarta algún chubasco vespertino aislado, que podría ser tormentoso. Temperaturas mínimas con ligeros cambios. Máximas en ligero o moderado ascenso. Viento

AEMET. Se autoriza la reproducción de su contenido citando la fuente.

flojo de dirección variable.

Pirineo aragonés:
Poco nuboso o despejado salvo por la tarde, cuando se desarrollará nubosidad de evolución diurna. Probables chubascos dispersos por la tarde, que podrían ser ocasionalmente tormentosos. Temperaturas con ligeros cambios, predominando los ascensos en las máximas. Viento flojo de dirección variable, con predominio de la componente sur.

Datos en la atmósfera libre:

Altitud de la isoterma de 0 ºC: 3200 m
Altitud de la isoterma de -10 ºC: 4900 m

Viento a 1500 m: VRB 5 km/h
Viento a 3000 m: W 10 km/h

Evolución para el lunes día 27

Nivel de peligro con pocos cambios.

(Información elaborada a partir de los datos recibidos de los refugios de Linza, Lizara, Respomuso, Panticosa, Bachimaña, Góriz, Pineta, Angel Orús y Cap de Llauset y de la estación de esquí de Panticosa (lagos))

Escala europea de peligro de aludes

Débil | Limitado | Notable | Fuerte | Muy Fuerte

Problemas de aludes

Nieve reciente | Placas de viento | Capas débiles persistentes | Nieve húmeda | Deslizamientos basales | Sin problema evidente

Nota1: Se recuerda que, siempre que haya nieve, la ausencia total de peligro no existe. Hay que tener presente que en circunstancias desfavorables, con aludes de tamaño 1 (alud pequeño o colada) y tamaño 2 (alud mediano), se pueden sufrir severos daños personales.

Nota2: Los BPA se elaboran en base a información meteorológica así como al estado del manto nivoso a través de sondeos puntuales. Se advierte a los usuarios de la variabilidad de esta información al extrapolarla a zonas extensas de montaña. Por ello, AEMET no se hace responsable de su uso para la toma de decisiones que conciernen a la seguridad personal, ni de los riesgos físicos o materiales de ellas derivadas.

AEMET. Se autoriza la reproducción de su contenido citando la fuente.