Sonntag 26.04.2026

Veröffentlicht am 25.04.2026 um 17:00

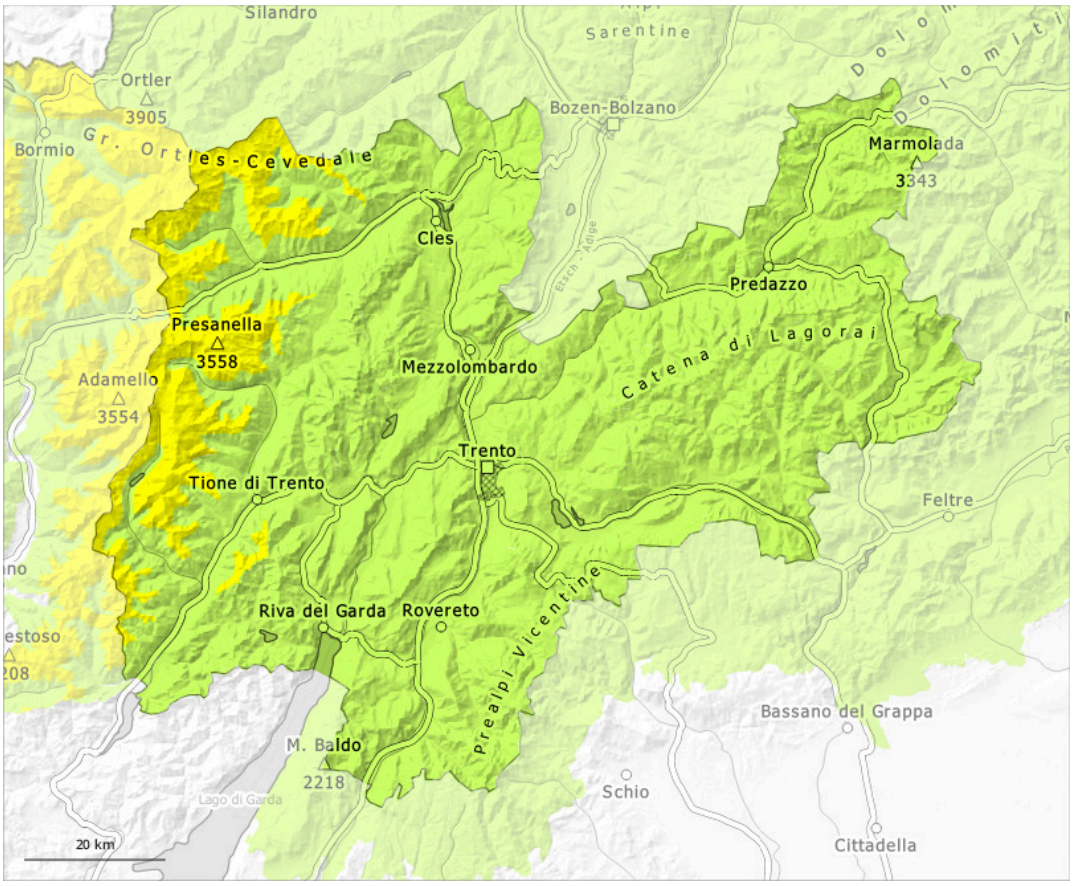

1	2	3	4	5
gering	mäßig	erheblich	groß	sehr groß

Gefahrenstufe 2 - Mäßig

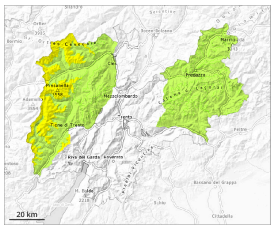

3000m

Tendenz: Lawinengefahr bleibt gleich
am Montag, den 27.04.2026

Nassschnee

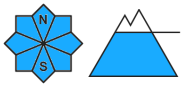

3000m

Altschnee

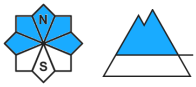

2500m

Anstieg der Gefahr von nassen Lawinen im Tagesverlauf.

Mit der tageszeitlichen Erwärmung und der Sonneneinstrahlung steigt die Gefahr von nassen Lawinen an. Lawinen können vor allem an Felswandfüßen spontan abgehen.
Einzelne Gefahrenstellen für trockene Lawinen liegen an sehr steilen Schattenhängen oberhalb von rund 2500 m. Solche Gefahrenstellen sind schwer zu erkennen.
Die Gefahr von Grundlawinen steigt im Tagesverlauf an.

Schneedecke

Gefahrenmuster gm.10: frühjahrssituation | gm.1: bodennahe schwachschicht

Die Schneeoberfläche ist nur in hohen Lagen tragfähig gefroren und weicht im Tagesverlauf auf. Sonne und Wärme führen unterhalb von rund 3000 m zu einer zunehmenden Durchnässung der Schneedecke.
Steile West-, Nord- und Osthänge oberhalb von rund 2500 m: Im unteren Teil der Altschneedecke sind kantig aufgebaute Schwachschichten vorhanden.
Unterhalb von rund 2000 m liegt für Schneesport meist zu wenig Schnee.

Tendenz

Sonntag: Die Lawinengefahr bleibt bestehen.

Gefahrenstufe 1 - Gering

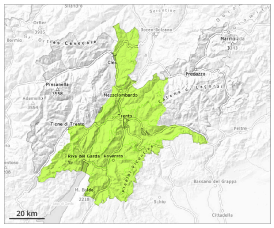

1

Tendenz: Lawinengefahr bleibt gleich
am Montag, den 27.04.2026

Nassschnee beachten.

Es sind nur noch vereinzelt nasse Lawinen möglich. Vorsicht an extrem steilen Schattenhängen. Lawinen sind meist eher klein.

Unterhalb von rund 2000 m liegt für Schneesport meist zu wenig Schnee.

Schneedecke

Gefahrenmuster gm.10: frühjahrssituation

Die Schneeoberfläche weicht im Tagesverlauf auf.

Tendenz

Sonntag: Die Lawinengefahr bleibt bestehen.