RÉPUBLIQUE FRANÇAISE
*Liberté Égalité Fraternité*

METEO FRANCE
À VOS CÔTÉS, DANS UN CLIMAT QUI CHANGE

# Bulletin d'estimation du risque d'avalanche

## (valable en dehors des pistes balisées et ouvertes)

# MASSIF : Couserans

Rédigé le samedi 25 avril 2026 à 15h

## Estimation des risques pour le : DIMANCHE 26 AVRIL

**POURSUITE DE L'HUMIDIFICATION, TRÈS GRANDES AVALANCHES DE FOND POSSIBLES.**

3

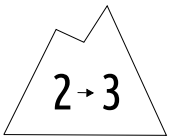


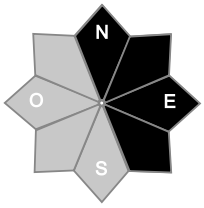


Indice de risque limité évoluant en marqué.

**Départs spontanés :** Avalanches de surface et avalanches de fond en neige humide

**Déclenchements provoqués :** Départs ponctuels en neige humide favorisés par le passage d'un randonneur

Indices de risque : 5 très fort - 4 fort - 3 marqué - 2 limité - 1 faible -- En noir : les pentes les plus dangereuses

## Stabilité du manteau neigeux

**Situation avalancheuse typique :** avalanches de fond neige humide

**Départs spontanés :**
- En altitude, avec l'humidification qui gagne en profondeur, des **avalanches de fond** emportant l'ensemble du manteau neigeux sont possibles en toutes orientations ( fissures/reptations et avalanches de fond signalées ces derniers jours). Elles seront de taille moyenne à grande, voire plus rarement très grandes dans les zones de plus fortes accumulations (pentes nord à sud-est). Les cassures peuvent en effet localement dépasser les 1 à 2m d'épaisseur. Ces avalanches peuvent alors parcourir des dénivelés importants et atteindre des sentiers à des altitudes inférieures à la limite d'enneigement dans les couloirs d'avalanche habituels. L'écoulement sera plus ou moins rapide selon la pente, avec parfois des blocs denses de tailles variées. Elles peuvent aussi entrainer avec elles des chutes de pierres.
- Avec un manteau intégralement humidifié, regelant peu en surface, des départs ponctuels d'**avalanches de neige humide**, de taille petite à moyenne sont déjà attendus dès le matin et deviennent plus nombreux au cours de la journée.

Ces deux types d'avalanches de neige humide peuvent aussi être initiés par la rupture d'une corniche sommitale ou suite à une averse alourdissant le manteau neigeux.
D'autre part, la présence d'un dépôt d'avalanche plus ou moins ancien n'est pas forcément un gage de sécurité dans le cas d'une pente sus-jacente pas totalement purgée.

.

**Déclenchements provoqués :**
- Un skieur coupant une pente raide déjà bien humidifiée pourra favoriser un départ ponctuel de taille petite à plus rarement moyenne. Ces coulées peuvent emporter les skis et provoquer la chute. Les pentes d'altitude orientées Est le matin puis Ouest en fin de journée (en passant par le Sud) sont les plus exposées à ce risque.

**Autre :** Des corniches encore imposantes sont en place et sont susceptibles de céder spontanément avec l'humidification, tout comme les ponts de neige sur les torrents bien alimentés par la fonte en cours.

## Qualité de la neige

**Enneigement :**
L'enneigement dans nos massifs reste bon pour la saison, encore largement supérieur à celui des derniers hivers. Avec la douceur ambiante, le manteau perd une dizaine de cm par jour en deçà de 2300/2400 m, et la limite skiable remonte progressivement, surtout en sud (où les quantités sont moins importantes). Elle est encore au mieux vers 1600/1700 m en nord et 1900 à 2000 m en sud, localement plus haut dans des zones moins enneigées cet hiver. On trouve ensuite rapidement une bonne épaisseur de neige qui dépasse encore souvent les 1m à 2000 m en nord, et 2m à 2500m.

**Qualité de la neige :**
Au petit matin, seules les pentes situées au-dessus de 2400/2500m devraient connaitre un regel en surface à la faveur des éclaircies de la nuit. Ailleurs, le regel est beaucoup plus aléatoire et bien souvent inexistant. L'humidification reprend rapidement en matinée, et se poursuit l'après-midi, de surcroit avec de nouvelles averses prévues.
La surface du manteau est généralement constituée de neige ocre, chargée en poussières sahariennes qui contribuent à accélérer la fonte. L'après-midi, la neige et partout lourde, souvent non portante pour les piétons. Les cols et crêtes ouest à nord-ouest sont généralement moins garnis en neige, les rochers affleurent de plus en plus en surface.

## Aperçu météo pour le dimanche 26 avril

| | nuit | matin | après-midi | soir |
|---|---|---|---|---|
| | | | | |
| | Mer de nuages le matin, des averses orageuses l'après-midi. | | | |
| **Pluie-Neige** | | | 2 900 m | 2 800 m |
| **Iso 0 °C** | 3 300 m | 3 200 m | 3 200 m | 3 200 m |
| **Vent 2000 m** | ↑ 5 km/h | ↙ 10 km/h | ↓ 15 km/h | ↑ 10 km/h |
| **Vent 3000 m** | ↗ 15 km/h | ↻ 15 km/h | ↙ 20 km/h | ↓ 10 km/h |

Pour consulter la vigilance en cours, veuillez vous rendre sur le site https://vigilance.meteofrance.fr/fr

Météo-France - 73 avenue de Paris, 94165 Saint-Mandé cedex - Contact : contact@meteo.fr

Rédigé par Météo-France avec la contribution des observateurs du réseau nivo-météorologiques. Partenariat : ANMSM (Maires de Stations de Montagne), DSF (Domaines Skiables de France), ADSP (Directeurs de Pistes et de la Sécurité des Stations de Sports d'Hiver) et autres acteurs de la montagne.

Bulletin neige & avalanches par téléphone au
0 892 68 10 20 Service 0,35 € / min + prix appel

# Bulletin d'estimation du risque d'avalanche

(valable en dehors des pistes balisées et ouvertes)

# MASSIF : Couserans

Rédigé le samedi 25 avril 2026 à 15h

## Épaisseur de neige hors-piste

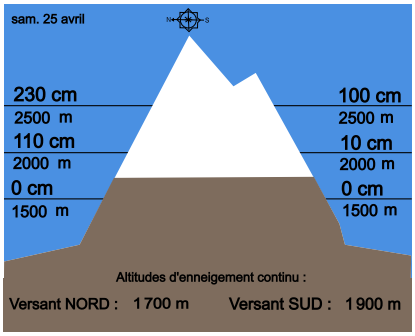


## Précipitations à 1800 m

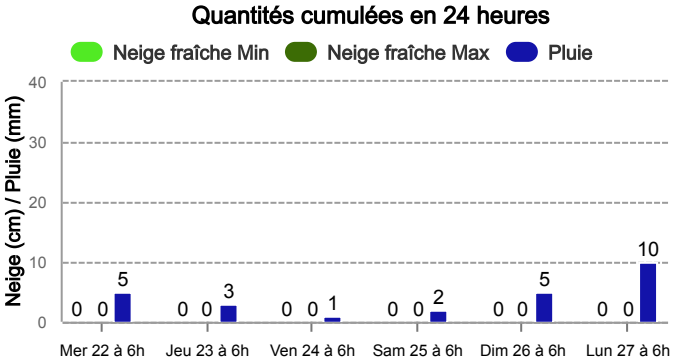


## Tendance du lundi 27 avril

**Indice de risque limité**

Plutôt en baisse.

Pour consulter la vigilance en cours, veuillez vous rendre sur le site https://vigilance.meteofrance.fr/fr

Météo-France - 73 avenue de Paris, 94165 Saint-Mandé cedex - Contact : contact@meteo.fr

Rédigé par Météo-France avec la contribution des observateurs du réseau nivo-météorologiques. Partenariat : ANMSM (Maires de Stations de Montagne), DSF (Domaines Skiables de France), ADSP (Directeurs de Pistes et de la Sécurité des Stations de Sports d'Hiver) et autres acteurs de la montagne.

Bulletin neige & avalanches par téléphone au

0 892 68 10 20 Service 0,35 € / min + prix appel

RÉPUBLIQUE FRANÇAISE
*Liberté Égalité Fraternité*

METEO FRANCE
À VOS CÔTÉS, DANS UN CLIMAT QUI CHANGE

# Bulletin d'estimation du risque d'avalanche

## (valable en dehors des pistes balisées et ouvertes)

# MASSIF : Couserans

Rédigé le samedi 25 avril 2026 à 15h

## Conditions nivo-météo des 7 derniers jours

| | dim. 19/04 | | | | lun. 20/04 | | | | mar. 21/04 | | | | mer. 22/04 | | | | jeu. 23/04 | | | | ven. 24/04 | | | | sam. 25/04 | | | |
|---|---|---|---|---|---|---|---|---|---|---|---|---|---|---|---|---|---|---|---|---|---|---|---|---|---|---|---|---|
| | 03h | 09h | 15h | 21h | 03h | 09h | 15h | 21h | 03h | 09h | 15h | 21h | 03h | 09h | 15h | 21h | 03h | 09h | 15h | 21h | 03h | 09h | 15h | 21h | 03h | 09h | 15h | 21h |
| Météo | | | | | | | | | | | | | | | | | | | | | | | | | | | | |
| Vent (km/h) | 20 | 15 | 20 | 20 | 25 | 25 | 30 | 25 | 25 | 30 | 40 | 40 | 45 | 25 | 25 | 20 | 25 | 20 | 25 | 15 | 25 | 25 | 25 | 15 | 20 | 20 | 20 | 15 |
| à 3000m | ↑ | → | ↓ | ↑ | ↑ | ↓ | ↘ | ↑ | → | ↑ | ↑ | ↑ | ↑ | → | ↓ | ↑ | ↑ | ↖ | → | ↑ | ↑ | ↙ | ↓ | → | ↓ | ↓ | ↓ | ↓ |
| Vent (km/h) | 15 | 10 | 15 | 15 | 20 | 20 | 20 | 15 | 15 | 20 | 25 | 35 | 40 | 20 | 20 | 15 | 15 | 15 | 20 | 15 | 20 | 20 | 20 | 10 | 10 | 10 | 15 | 5 |
| à 2000m | ↑ | ↓ | ↘ | ↗ | ↗ | → | ↘ | ↑ | ↗ | ↑ | ↗ | ↑ | ↑ | → | ↓ | ↑ | ↑ | ↗ | ↗ | ↗ | ↑ | ↓ | ↙ | ↗ | ↗ | ↙ | ↙ | ↓ |

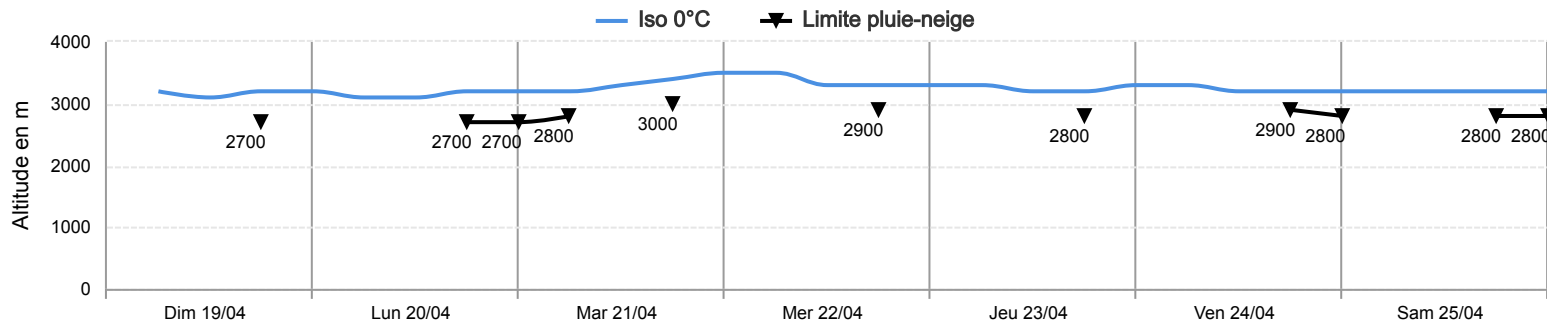


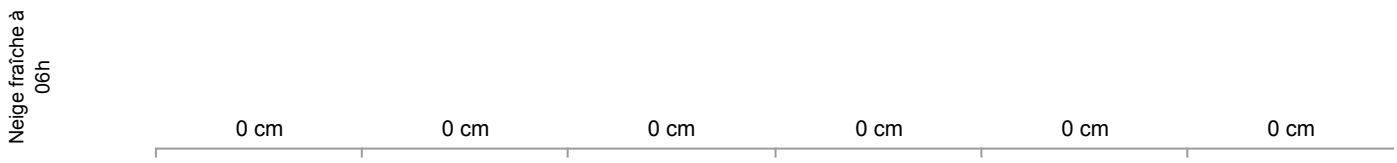


| Risque d'avalanche | dim. 19/04 | lun. 20/04 | mar. 21/04 | mer. 22/04 | jeu. 23/04 | ven. 24/04 | sam. 25/04 |
|---|---|---|---|---|---|---|---|
| | 2 | 2 | 2 | 3 | 3 | 3 | 3 |

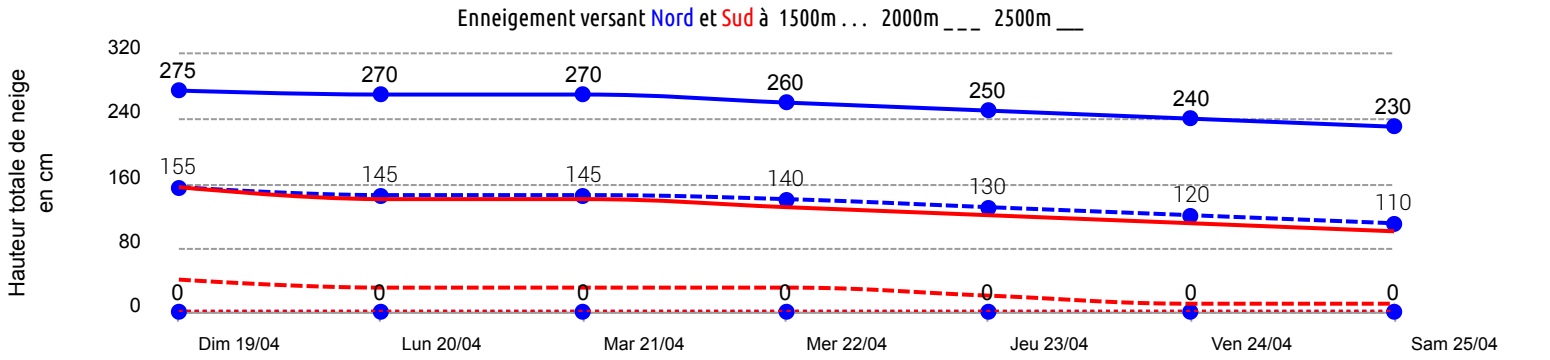


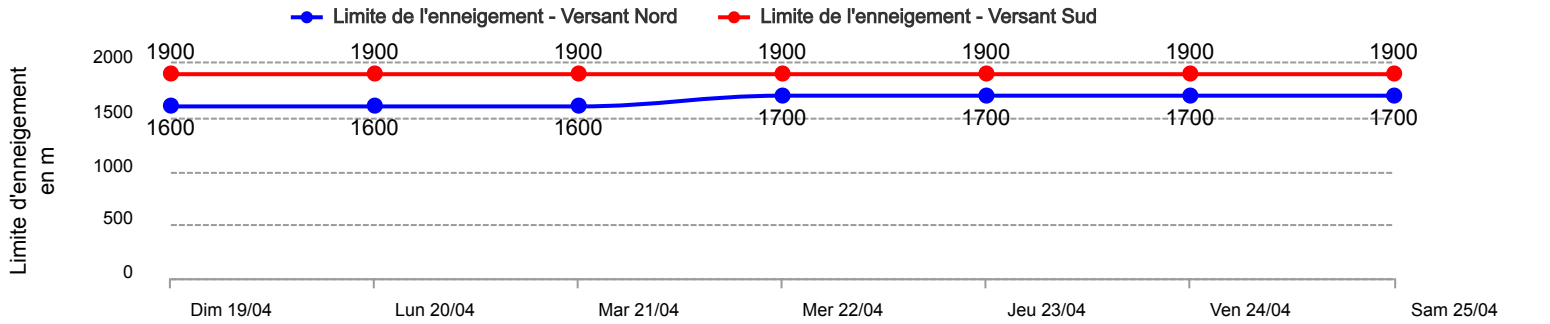


Pour consulter la vigilance en cours, veuillez vous rendre sur le site https://vigilance.meteofrance.fr/fr


Météo-France - 73 avenue de Paris, 94165 Saint-Mandé cedex - Contact : contact@meteo.fr



Rédigé par Météo-France avec la contribution des observateurs du réseau nivo-météorologiques. Partenariat : ANMSM (Maires de Stations de Montagne), DSF (Domaines Skiables de France), ADSP (Directeurs de Pistes et de la Sécurité des Stations de Sports d'Hiver) et autres acteurs de la montagne.



Bulletin neige & avalanches par téléphone au
0 892 68 10 20 Service 0,35 € / min + prix appel