RÉPUBLIQUE FRANÇAISE
Liberté Égalité Fraternité

METEO FRANCE
À VOS CÔTÉS, DANS UN CLIMAT QUI CHANGE

Bulletin d'estimation du risque d'avalanche
(valable en dehors des pistes balisées et ouvertes)

MASSIF : Chablais

Rédigé le samedi 25 avril 2026 à 16h

Estimation des risques pour le : DIMANCHE 26 AVRIL

CONDITIONS PRINTANIÈRES

2

1 → 2

N O E S

Indice de risque faible évoluant en limité.

Départs spontanés : avalanche de neige humide

Déclenchements provoqués : petits départs en neige humide sous les skis

Indices de risque : 5 très fort - 4 fort - 3 marqué - 2 limité - 1 faible -- En noir : les pentes les plus dangereuses

Stabilité du manteau neigeux

Situation avalancheuse typique : neige humide — avalanches de fond

Départs spontanés :
* rares **avalanches de neige humide, plus nombreuses au fil du réchauffement et du rayonnement solaire.** Taille 1 à 2 (petite à moyenne).
* quelques plaques de fond dans les zones herbeuses ou les dalles rocheuses, à toute heure du jour ou de la nuit. En dessous 2500 m. Taille 2 (moyenne). Au-dessus de 2300 m, dans les versants est, ouest et nord, de petits départs ponctuels peuvent déclencher, en cascade, une plaque de fond. Rare taille 3 (grande).

Déclenchements provoqués :
* avalanches de neige humide. Facile à déclencher au soleil. Départ ponctuel sous les skis. Taille 1 à 2. Causé par le réchauffement et le rayonnement solaire.

Qualité de la neige

Enneigement :
Pour la saison, l'enneigement est déficitaire sous 2500 m
On peut chausser les skis au-dessus de 2000 m en sud et 1600 m en nord.

Qualité de la neige ce dimanche matin :
* sous 2000 m, neige de névé avec un bon regel nocturne
* au-dessus de 2000 m, neige de printemps avec un bon regel nocturne.

Aperçu météo pour le dimanche 26 avril

	nuit	matin	après-midi	soir
	ensoleillé. Cumulus au-dessus du relief l'après-midi. Au maximum 12°C à 2000 m.			
Pluie-Neige				
Iso 0 °C	3 200 m	3 300 m	3 200 m	3 200 m
Vent 2000 m	5 km/h	5 km/h	5 km/h	10 km/h
Vent 2500 m	5 km/h	10 km/h	5 km/h	10 km/h

Épaisseur de neige hors-piste

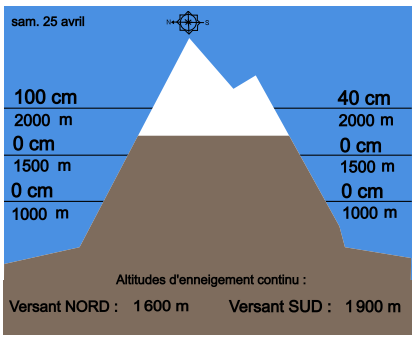

Précipitations à 1800 m

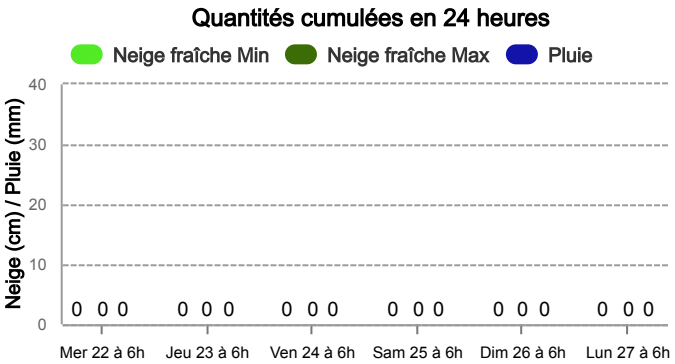

Tendance du lundi 27 avril

2

Indice de risque limité

Lundi : temps sec et rares cumulus l'après-midi. Isotherme 0°C vers 3000 m.
⇒ poursuite de l'humidification du manteau neigeux

Pour consulter la vigilance en cours, veuillez vous rendre sur le site https://vigilance.meteofrance.fr/fr

Météo-France - 73 avenue de Paris, 94165 Saint-Mandé cedex - Contact : contact@meteo.fr

Rédigé par Météo-France avec la contribution des observateurs du réseau nivo-météorologiques. Partenariat : ANMSM (Maires de Stations de Montagne), DSF (Domaines Skiables de France), ADSP (Directeurs de Pistes et de la Sécurité des Stations de Sports d'Hiver) et autres acteurs de la montagne.

Bulletin neige & avalanches par téléphone au
0 892 68 10 20 Service 0,35 € / min + prix appel

RÉPUBLIQUE FRANÇAISE
Liberté Égalité Fraternité

METEO FRANCE
À VOS CÔTÉS, DANS UN CLIMAT QUI CHANGE

Bulletin d'estimation du risque d'avalanche

(valable en dehors des pistes balisées et ouvertes)

MASSIF : Chablais

Rédigé le samedi 25 avril 2026 à 16h

Conditions nivo-météo des 7 derniers jours

	dim. 19/04				lun. 20/04				mar. 21/04				mer. 22/04				jeu. 23/04				ven. 24/04				sam. 25/04			
	03h	09h	15h	21h	03h	09h	15h	21h	03h	09h	15h	21h	03h	09h	15h	21h	03h	09h	15h	21h	03h	09h	15h	21h	03h	09h	15h	21h
Météo																												
Vent (km/h)	20	25	25	30	30	25	20	20	20	20	30	20	20	20	10	10	10	20	20	20	10	5	10	10	10	20	15	5
à 2500m																												
Vent (km/h)	15	20	15	20	15	15	15	10	10	15	20	10	15	10	5	5	5	15	10	10	5	5	5	5	10	15	15	5
à 2000m																												

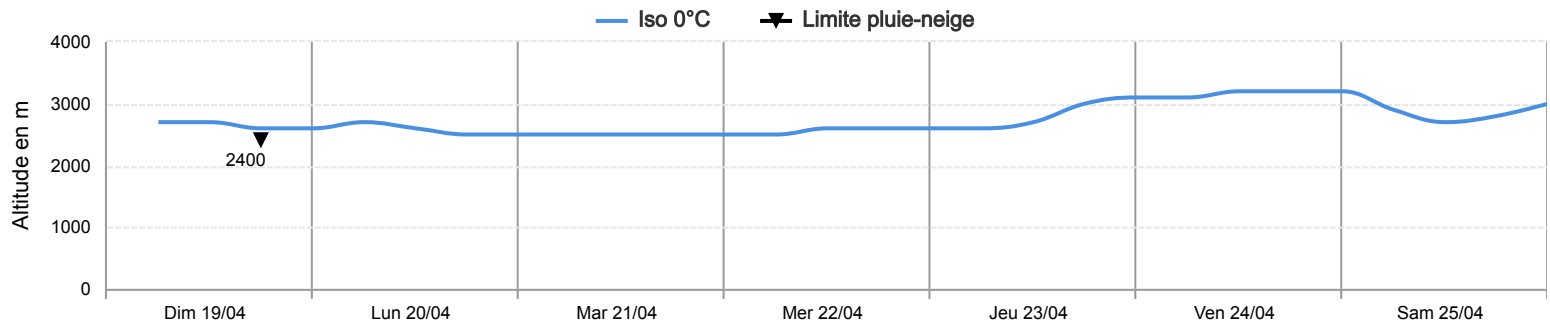

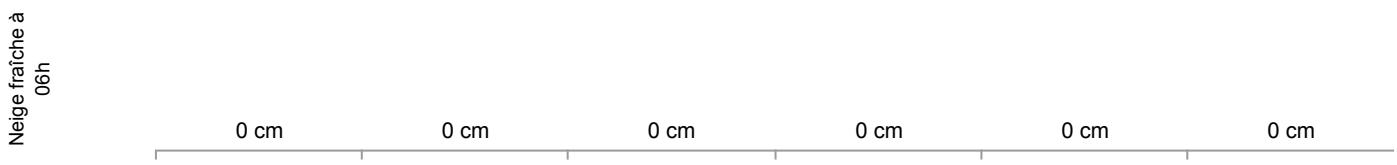

Risque d'avalanche	dim. 19/04	lun. 20/04	mar. 21/04	mer. 22/04	jeu. 23/04	ven. 24/04	sam. 25/04
	2	2	2	2	2	2	2

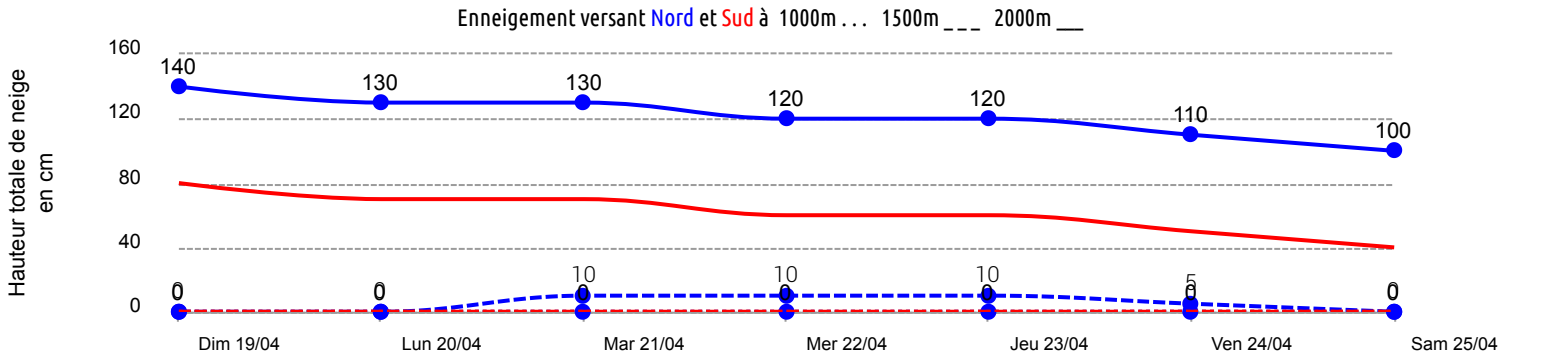

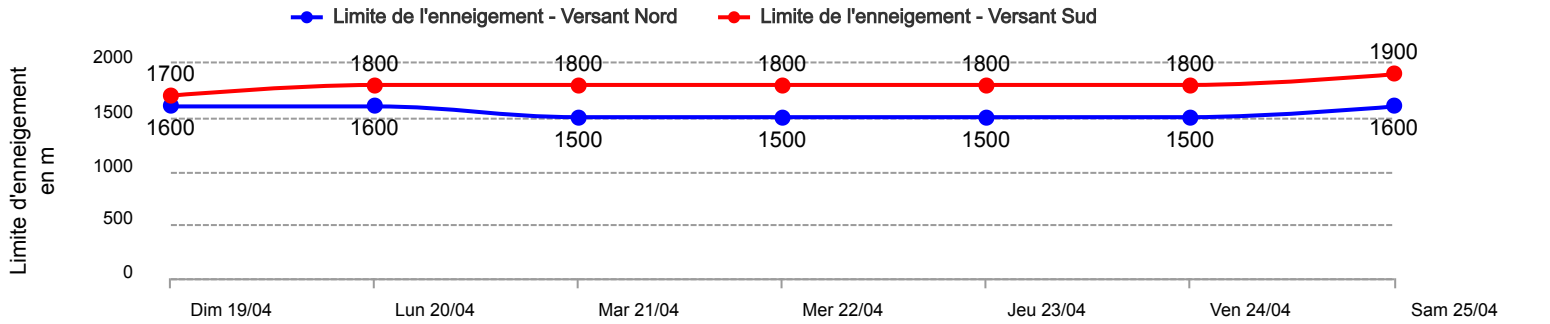

Pour consulter la vigilance en cours, veuillez vous rendre sur le site https://vigilance.meteofrance.fr/fr

Météo-France - 73 avenue de Paris, 94165 Saint-Mandé cedex - Contact : contact@meteo.fr

Bulletin neige & avalanches par téléphone au

0 892 68 10 20 Service 0,35 € / min + prix appel

Rédigé par Météo-France avec la contribution des observateurs du réseau nivo-météorologiques. Partenariat : ANMSM (Maires de Stations de Montagne), DSF (Domaines Skiables de France), ADSP (Directeurs de Pistes et de la Sécurité des Stations de Sports d'Hiver) et autres acteurs de la montagne.