Bulletin d'estimation du risque d'avalanche
(valable en dehors des pistes balisées et ouvertes)

MASSIF : Devoluy

Rédigé le samedi 25 avril 2026 à 16h

Estimation des risques pour le : DIMANCHE 26 AVRIL

MANTEAU NEIGEUX PRINTANIER. L'HUMIDIFICATION EN PROFONDEUR EN UBAC D'ALTITUDE SE POURSUIT.

2

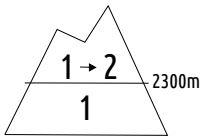

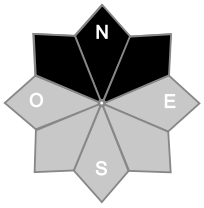

Au-dessus de 2300m indice de risque faible évoluant en limité, plus bas indice faible.

Départs spontanés : en neige humide. Rares, mais possiblement volumineux en ubacs d'altitude.

Déclenchements provoqués : en neige humide.

Indices de risque : 5 très fort - 4 fort - 3 marqué - 2 limité - 1 faible -- En noir : les pentes les plus dangereuses

Stabilité du manteau neigeux

Situation avalancheuse typique : neige humide

Départs spontanés : avalanches en neige humide restant rares mais pouvant être volumineuses en cas de départ linéaire. Taille moyenne à grande, dans les pentes nord-ouest / nord / nord-est au-dessus de 2300/2400 m environ, pouvant emporter la totalité du manteau neigeux. Peu probables en début de journée après un bon regel nocturne, puis risque en augmentation au fil du réchauffement et de l'ensoleillement. En dessous de 2400 m environ, et dans les pentes sud jusqu'à haute altitude, le manteau neigeux printanier est désormais dense et bien stabilisé.

Déclenchements provoqués : un skieur coupant une pente raide tardivement peut initier un départ de neige humide sous les skis. Dans les ubacs au-dessus de 2300/2400 m environ, une première avalanche superficielle de neige humide déclenchée par un skieur peut dans de rares cas provoquer un départ linéaire plus volumineux.

Qualité de la neige

Enneigement en nette diminution, encore proche des normales en vallons d'altitude, déficitaire en adrets.

Limite d'enneigement skiable : très localement vers 1600/1700 m en terrain favorable, 2200/2400 m en adrets.

État de la neige de surface : manteau neigeux printanier, voire de névé en toute orientation sous 2300/2400 m environ et en adrets d'altitude. Bon regel nocturne, puis reprise de l'humidification en journée.

Aperçu météo pour le dimanche 26 avril

	nuit	matin	après-midi	soir
Temps calme, largement ensoleillé et chaud. Voile nuageux plus épais en seconde partie de journée.				
Pluie-Neige				
Iso 0 °C	3 400 m	3 400 m	3 300 m	3 200 m
Vent 2000 m	↓ 20 km/h	↓ 15 km/h	↓ 20 km/h	↓ 5 km/h
Vent 3000 m	↓ 10 km/h	↖ 5 km/h	↑ 15 km/h	↗ 5 km/h

Épaisseur de neige hors-piste

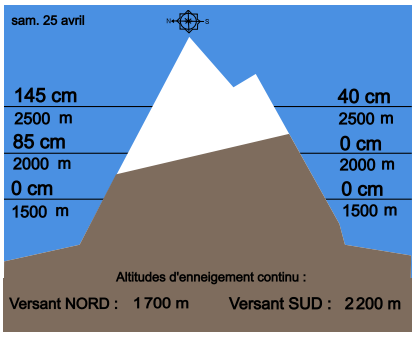

Précipitations à 1800 m

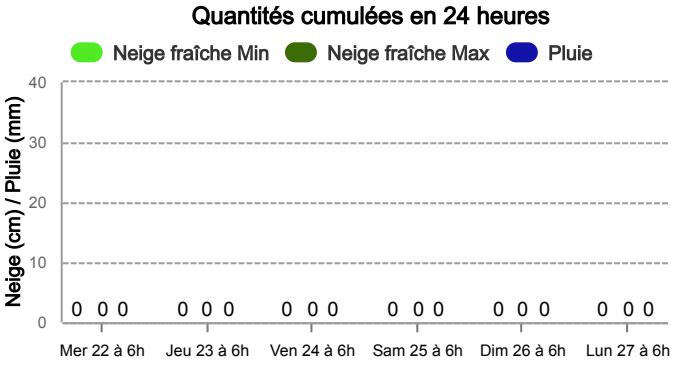

Tendance du lundi 27 avril

2

Indice de risque limité

Peu d'évolution. La situation nivologique reste pilotée par l'activité en neige humide au cours de la journée. Rares départs linéaires volumineux dans les ubacs d'altitude.

Pour consulter la vigilance en cours, veuillez vous rendre sur le site https://vigilance.meteofrance.fr/fr

Météo-France - 73 avenue de Paris, 94165 Saint-Mandé cedex - Contact : contact@meteo.fr

Rédigé par Météo-France avec la contribution des observateurs du réseau nivo-météorologiques. Partenariat : ANMSM (Maires de Stations de Montagne), DSF (Domaines Skiables de France), ADSP (Directeurs de Pistes et de la Sécurité des Stations de Sports d'Hiver) et autres acteurs de la montagne.

Bulletin neige & avalanches par téléphone au 0 892 68 10 20 Service 0,35 € / min + prix appel

RÉPUBLIQUE FRANÇAISE
Liberté Égalité Fraternité

METEO FRANCE
À VOS CÔTÉS, DANS UN CLIMAT QUI CHANGE

Bulletin d'estimation du risque d'avalanche
(valable en dehors des pistes balisées et ouvertes)

MASSIF : Devoluy

Rédigé le samedi 25 avril 2026 à 16h

Conditions nivo-météo des 7 derniers jours

	dim. 19/04				lun. 20/04				mar. 21/04				mer. 22/04				jeu. 23/04				ven. 24/04				sam. 25/04			
	03h	09h	15h	21h	03h	09h	15h	21h	03h	09h	15h	21h	03h	09h	15h	21h	03h	09h	15h	21h	03h	09h	15h	21h	03h	09h	15h	21h
Météo																												
Vent (km/h)	20	25	20	20	20	30	20	30	35	35	30	35	35	40	30	20	15	15	20	20	15	5	10	5	5	15	15	15
à 3000m																												
Vent (km/h)	15	20	25	15	15	15	25	15	15	15	20	15	10	10	25	10	10	10	20	10	5	5	15	10	10	25	35	25
à 2000m																												

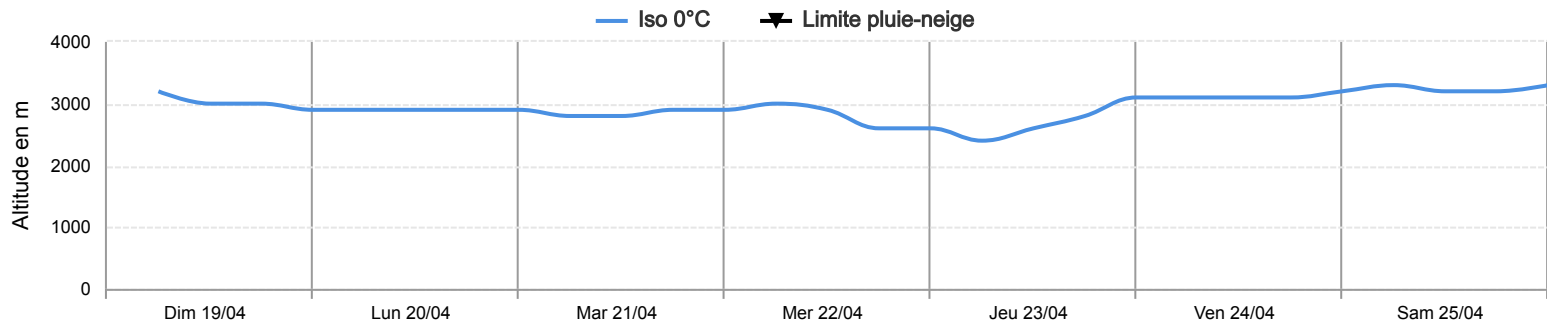

Neige fraîche à 06h

dim. 19/04	lun. 20/04	mar. 21/04	mer. 22/04	jeu. 23/04	ven. 24/04	sam. 25/04
0 cm	0 cm	0 cm	0 cm	0 cm	0 cm	

Risque d'avalanche	dim. 19/04	lun. 20/04	mar. 21/04	mer. 22/04	jeu. 23/04	ven. 24/04	sam. 25/04
	2	2	2	1	2	2	2

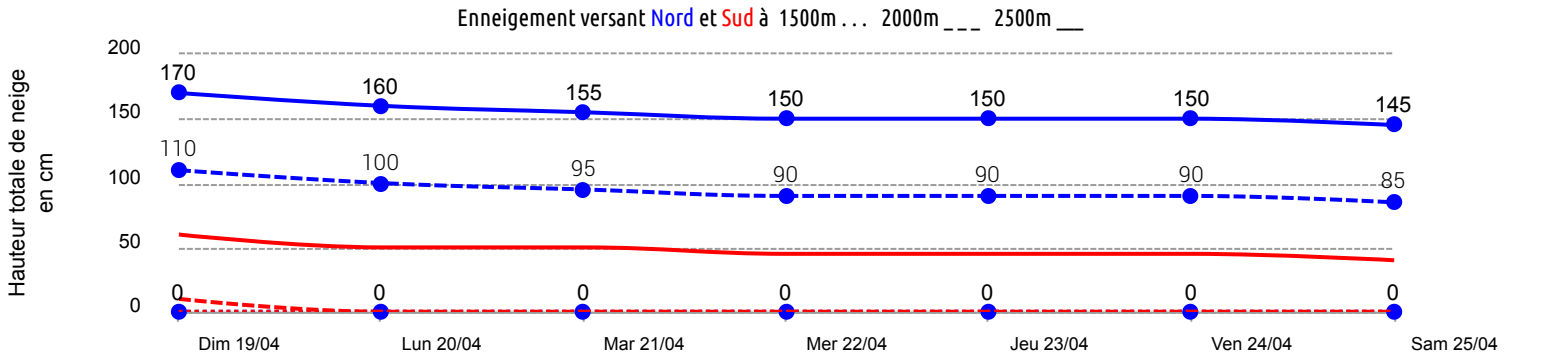

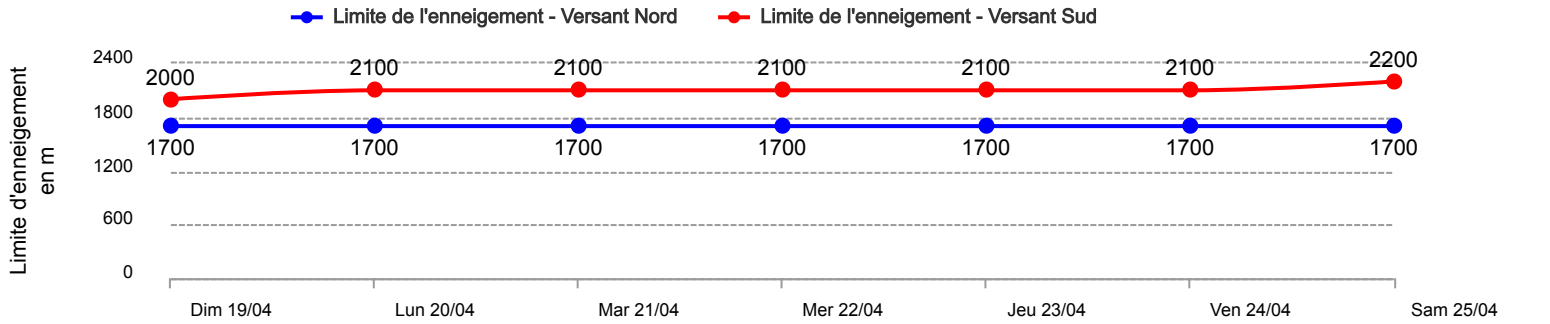

Pour consulter la vigilance en cours, veuillez vous rendre sur le site https://vigilance.meteofrance.fr/fr

Météo-France - 73 avenue de Paris, 94165 Saint-Mandé cedex - Contact : contact@meteo.fr

Rédigé par Météo-France avec la contribution des observateurs du réseau nivo-météorologiques. Partenariat : ANMSM (Maires de Stations de Montagne), DSF (Domaines Skiables de France), ADSP (Directeurs de Pistes et de la Sécurité des Stations de Sports d'Hiver) et autres acteurs de la montagne.

Bulletin neige & avalanches par téléphone au
0 892 68 10 20 Service 0,35 € / min + prix appel