RÉPUBLIQUE FRANÇAISE
Liberté Égalité Fraternité

METEO FRANCE
À VOS CÔTÉS, DANS UN CLIMAT QUI CHANGE

Bulletin d'estimation du risque d'avalanche
(valable en dehors des pistes balisées et ouvertes)
MASSIF : Grandes-Rousses

Rédigé le samedi 25 avril 2026 à 16h

Estimation des risques pour le : DIMANCHE 26 AVRIL

MANTEAU NEIGEUX PRINTANIER, RARE AVALANCHE DE "FONTE", TRÈS PONCTUELLEMENT UNE CASSURE LINÉAIRE EN FACE NORD ?

2

1 → 2

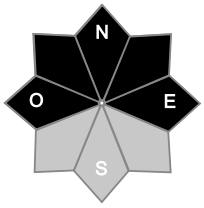

Rares, en altitude

Indices de risque : 5 très fort - 4 fort - 3 marqué - 2 limité - 1 faible -- En noir : les pentes les plus dangereuses

Indice de risque faible évoluant en limité.

Départs spontanés : Rares avalanches humides ou départs au terrain, plutôt en faces "froides". Une cassure large non exclue en Nord d'altitude.

Déclenchements provoqués : Peu probables, ou sous les skis en neige très humide (pentes raides)...

Stabilité du manteau neigeux

Situation avalancheuse typique : neige humide

Départs spontanés : Dans les pentes Est, Nord et Ouest, où l'humidification gagne en profondeur, de rares avalanches humides peuvent se produire aux heures chaudes de la journée ou le soir. De taille 1 à 2 avec départ ponctuel, mais exceptionnellement et plutôt en versant Nord, une grande avalanche de taille 3 ne peut être exclue si l'humidification atteint une couche fragile plus enfouie, avec départ linéaire et/ou au terrain possible. En faces Sud, moins de neige et très dense, presque de névé, stable...

Déclenchements provoqués : Peu probables, hormis un risque limité de coulée ponctuelle sous les skis en terrain raide et bien humidifié.

Autres : Neige parfois durcie / croûtée par le regel à l'ombre, en début de journée notamment.

Qualité de la neige

Qualification de l'enneigement : L'enneigement s'est bien réduit depuis 3 semaines, il devient déficitaire en faces Sud et moyenne montagne. Il reste correct dans les versants Nord d'altitude.

Limites skiables : Vers 1600/1800m en Nord à 2000/2400m suivant l'exposition au soleil, la raideur de la pente...

Qualité de la neige dimanche : Neige bosselée, parfois croûtée / durcie par le regel (moyen à correct en altitude). Puis l'humidification et la fonte reprennent, assez rapidement au soleil, donnant une neige très humide.

Aperçu météo pour le dimanche 26 avril

nuit	matin	après-midi	soir

Soleil parfois voilé. Quelques cumulus isolés l'après-midi.

Pluie-Neige				
Iso 0 °C	3 100 m	3 300 m	3 200 m	3 200 m
Vent 2000 m	↘ 10 km/h	↗ 10 km/h	→ 10 km/h	↑ 5 km/h
Vent 3000 m	↘ 15 km/h	↙ 15 km/h	→ 15 km/h	↗ 10 km/h

Épaisseur de neige hors-piste

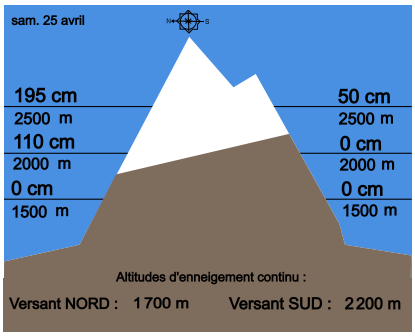

Précipitations à 1800 m

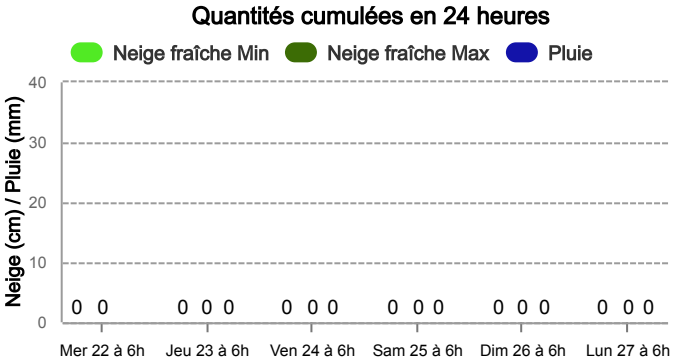

Tendance du lundi 27 avril

2

Indice de risque limité

Lundi, le risque évolue peu. A nouveau un peu de regel nocturne, puis poursuite de l'humidification et de la fonte.

Pour consulter la vigilance en cours, veuillez vous rendre sur le site https://vigilance.meteofrance.fr/fr

Météo-France - 73 avenue de Paris, 94165 Saint-Mandé cedex - Contact : contact@meteo.fr

Rédigé par Météo-France avec la contribution des observateurs du réseau nivo-météorologiques. Partenariat : ANMSM (Maires de Stations de Montagne), DSF (Domaines Skiables de France), ADSP (Directeurs de Pistes et de la Sécurité des Stations de Sports d'Hiver) et autres acteurs de la montagne.

Bulletin neige & avalanches par téléphone au
0 892 68 10 20 Service 0,35 € / min + prix appel

RÉPUBLIQUE FRANÇAISE
Liberté Égalité Fraternité

METEO FRANCE
À VOS CÔTÉS, DANS UN CLIMAT QUI CHANGE

Bulletin d'estimation du risque d'avalanche

(valable en dehors des pistes balisées et ouvertes)

MASSIF : Grandes-Rousses

Rédigé le samedi 25 avril 2026 à 16h

Conditions nivo-météo des 7 derniers jours

	dim. 19/04				lun. 20/04				mar. 21/04				mer. 22/04				jeu. 23/04				ven. 24/04				sam. 25/04			
	03h	09h	15h	21h	03h	09h	15h	21h	03h	09h	15h	21h	03h	09h	15h	21h	03h	09h	15h	21h	03h	09h	15h	21h	03h	09h	15h	21h
Météo																												
Vent (km/h)	15	20	25	30	20	25	25	30	35	30	30	20	30	30	25	15	15	20	15	10	15	10	10	10	10	15	20	15
à 3000m																												
Vent (km/h)	10	15	20	15	10	15	25	15	10	10	20	10	15	20	25	10	10	15	15	10	5	5	15	5	5	10	15	10
à 2000m																												

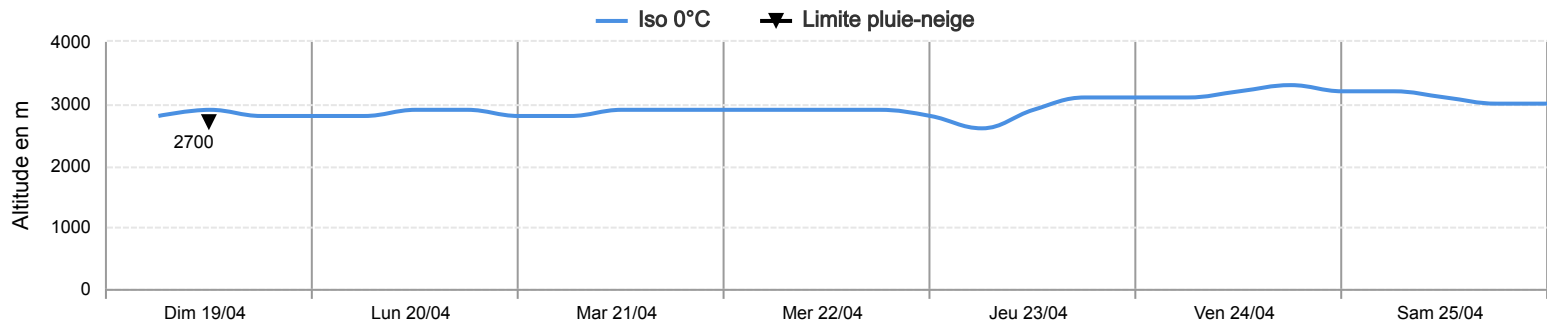

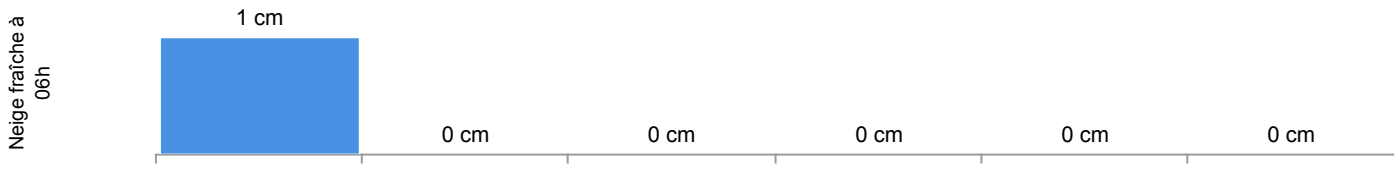

Risque d'avalanche	dim. 19/04	lun. 20/04	mar. 21/04	mer. 22/04	jeu. 23/04	ven. 24/04	sam. 25/04
	2	2	2	2	2	2	2

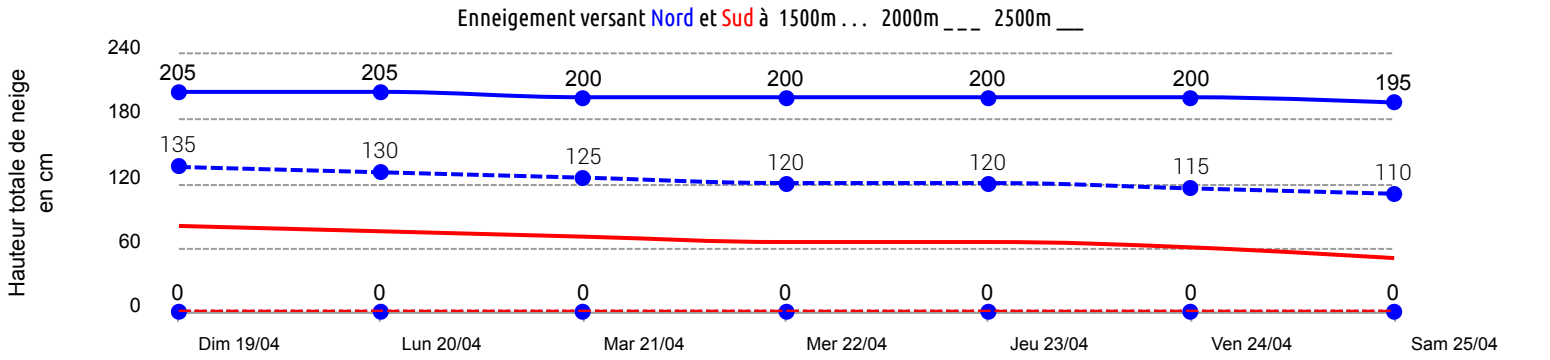

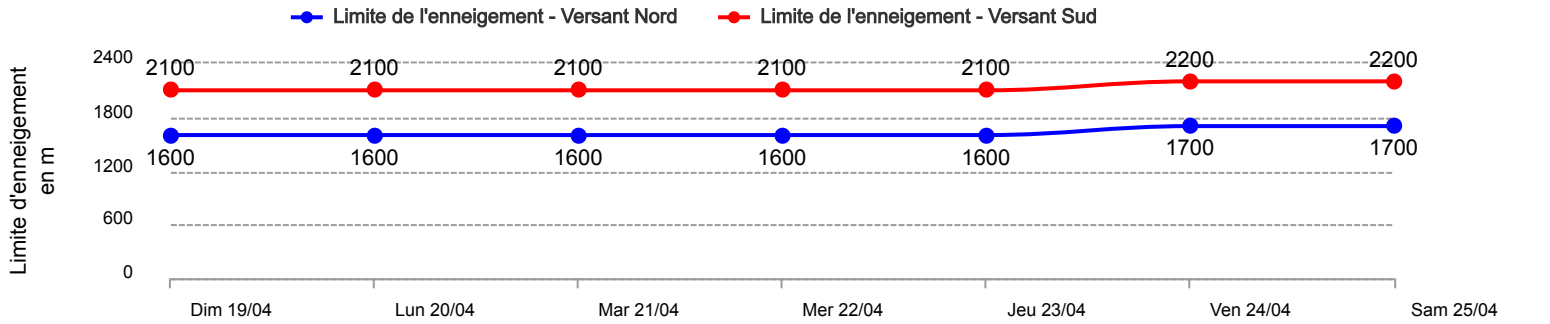

Pour consulter la vigilance en cours, veuillez vous rendre sur le site https://vigilance.meteofrance.fr/fr

Météo-France - 73 avenue de Paris, 94165 Saint-Mandé cedex - Contact : contact@meteo.fr

Bulletin neige & avalanches par téléphone au 0 892 68 10 20 Service 0,35 € / min + prix appel

Rédigé par Météo-France avec la contribution des observateurs du réseau nivo-météorologiques. Partenariat : ANMSM (Maires de Stations de Montagne), DSF (Domaines Skiables de France), ADSP (Directeurs de Pistes et de la Sécurité des Stations de Sports d'Hiver) et autres acteurs de la montagne.