RÉPUBLIQUE FRANÇAISE
*Liberté Égalité Fraternité*

METEO FRANCE
À VOS CÔTÉS, DANS UN CLIMAT QUI CHANGE

# Bulletin d'estimation du risque d'avalanche
## (valable en dehors des pistes balisées et ouvertes)

# MASSIF : Luchonnais

Rédigé le samedi 25 avril 2026 à 16h

## Estimation des risques pour le : DIMANCHE 26 AVRIL

**HUMIDIFICATION EN PROFONDEUR TOUJOURS EN COURS.**

3

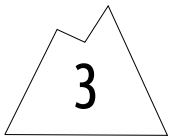


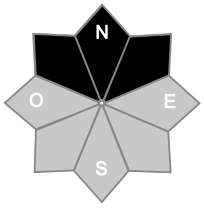


Indice de risque marqué.

**Départs spontanés :** en neige humide, avalanches de fond moyenne à rarement très grandes.

**Déclenchements provoqués :** en neige humide seulement.

Indices de risque : 5 très fort - 4 fort - 3 marqué - 2 limité - 1 faible -- En noir : les pentes les plus dangereuses

## Stabilité du manteau neigeux

**Situation avalancheuse typique :** neige humide avalanches de fond

**Départs spontanés** : coulées et avalanches petites à moyennes en neige humide, rarement grandes.
Manteau neigeux à peine ressaisi sous 2400m, faiblement regelé en surface au-dessus au petit matin, donc **peu d'activité à attendre aux premières heures de la journée**, plutôt sous forme de **départs ponctuels de boulettes et de coulées de neige humide**.
**Activité augmentant en fréquence** sous les **éclaircies du matin** puis les **averses de l'après-midi**, les coulées deviendront des **avalanches de taille moyenne dans les pentes raides**.
**L'humidification pénétrant en profondeur** dans le manteau neigeux au cours de la journée, **quelques avalanches de fond de taille moyenne** restent possibles dans l'après-midi et en fin de journée dans les **pentes nord**, partant du haut du massif, engendrant **localement** par effet de cascade en emportant la neige détrempée en contrebas une **avalanche de grande taille** pouvant **descendre bas en altitude**.
**Plus rare mais toujours possible** à cette même période de la journée, **une très grande avalanche de fond** peut spontanément se déclencher, notamment au niveau des **fissures,** ouvertes ou s'ouvrant plutôt **au-dessus de 2400 à 2500m** maintenant, où l'on trouve autour du secteur nord des accumulations encore importantes pour la saison.

**Déclenchements provoqués** : en neige humide seulement.
Déclenchement **difficile de boulettes et de petites coulées de surface en pentes nord-est à est en début de matinée**, puis **déclenchement aisé de coulées et petites avalanches par un seul skieur ou randonneur** en **coupant une pente raide en neige très humide à détrempée**, **très localement une avalanche moyenne** au plus fort d' l'humidification dans les **secteurs sud à ouest**.

**Autres** :
- **corniches et ponts de neige** encore en place **fragiles et peu résistants**, pouvant **céder** dès le matin **spontanément** ou sous le **poids d'une seule personne**.
- les **chemins de randonnée déjà déneigés** mais **situés sous les secteurs d'altitude encore chargés** peuvent être **atteints par une avalanche de fond de grande taille** ou plus dans l'après-midi.

## Qualité de la neige

**Enneigement** : plutôt bon pour la saison et débutant encore vers 1800m en nord et au-dessus de 2100m en sud. Les limites de cet enneigement remontent progressivement dans la douceur ambiante, sous les éclaircies matinales et les quelques averses de l'après-midi.
**État de la neige** : au petit matin, manteau neigeux tout juste ressaisi sous 2400m mais portant, plus au moins regelé en surface au dessus.
Dans la douceur ambiante, sous les éclaircies du matin, les averses localement orageuses de l'après-midi, l'humidification en profondeur se poursuit, le manteau neigeux ramollit au fil des heures : neige devenant très humide à détrempée en versants nord au-dessus de 2400/2500m, souvent pourrie en versants nord sous 2400/2500m et en versants sud raides.

## Aperçu météo pour le dimanche 26 avril

| | nuit | matin | après-midi | soir |
|---|---|---|---|---|
| | 1400 m | | | |

Temps doux, mer de nuages au petit matin, sec avec éclaircies en matinée, averses localement orageuses l'après-midi.

| | | | | |
|---|---|---|---|---|
| **Pluie-Neige** | | | 2900 m | |
| **Iso 0 °C** | 3300 m | 3300 m | 3300 m | 3300 m |
| **Vent 2000 m** | 0 km/h | 5 km/h | 5 km/h | 5 km/h |
| **Vent 3000 m** | 20 km/h | 15 km/h | 15 km/h | 20 km/h |

Pour consulter la vigilance en cours, veuillez vous rendre sur le site https://vigilance.meteofrance.fr/fr

Météo-France - 73 avenue de Paris, 94165 Saint-Mandé cedex - Contact : contact@meteo.fr

Rédigé par Météo-France avec la contribution des observateurs du réseau nivo-météorologiques. Partenariat : ANMSM (Maires de Stations de Montagne), DSF (Domaines Skiables de France), ADSP (Directeurs de Pistes et de la Sécurité des Stations de Sports d'Hiver) et autres acteurs de la montagne.

Bulletin neige & avalanches par téléphone au
0 892 68 10 20 Service 0,35 € / min + prix appel

# Bulletin d'estimation du risque d'avalanche

(valable en dehors des pistes balisées et ouvertes)

# MASSIF : Luchonnais

Rédigé le samedi 25 avril 2026 à 16h

## Épaisseur de neige hors-piste

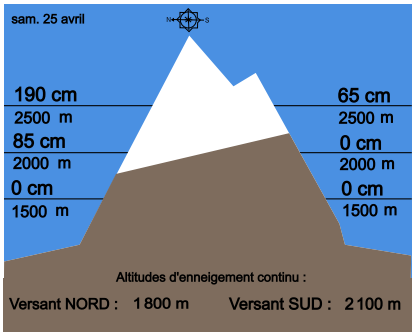


## Précipitations à 1800 m

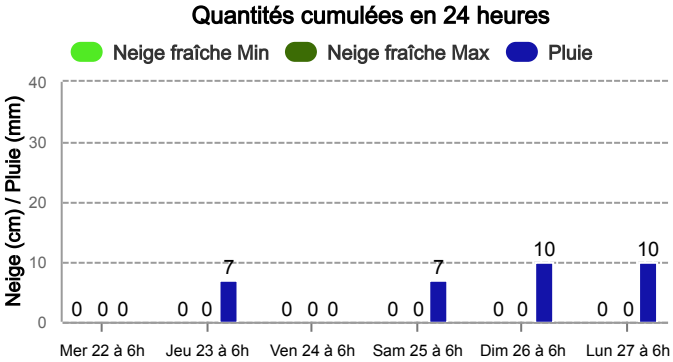


## Tendance du lundi 27 avril

**Indice de risque limité**

Sans évolution notable des conditions météorologiques et le manteau neigeux étant de plus en plus tassé, le risque devrait diminuer et devenir limité.

Pour consulter la vigilance en cours, veuillez vous rendre sur le site https://vigilance.meteofrance.fr/fr

Météo-France - 73 avenue de Paris, 94165 Saint-Mandé cedex - Contact : contact@meteo.fr

Rédigé par Météo-France avec la contribution des observateurs du réseau nivo-météorologiques. Partenariat : ANMSM (Maires de Stations de Montagne), DSF (Domaines Skiables de France), ADSP (Directeurs de Pistes et de la Sécurité des Stations de Sports d'Hiver) et autres acteurs de la montagne.

Bulletin neige & avalanches par téléphone au

0 892 68 10 20 Service 0,35 € / min + prix appel

RÉPUBLIQUE FRANÇAISE
*Liberté Égalité Fraternité*

METEO FRANCE
À VOS CÔTÉS, DANS UN CLIMAT QUI CHANGE

# Bulletin d'estimation du risque d'avalanche

## (valable en dehors des pistes balisées et ouvertes)

# MASSIF : Luchonnais

Rédigé le samedi 25 avril 2026 à 16h

## Conditions nivo-météo des 7 derniers jours

| | dim. 19/04 | | | | lun. 20/04 | | | | mar. 21/04 | | | | mer. 22/04 | | | | jeu. 23/04 | | | | ven. 24/04 | | | | sam. 25/04 | | | |
|---|---|---|---|---|---|---|---|---|---|---|---|---|---|---|---|---|---|---|---|---|---|---|---|---|---|---|---|---|
| | 03h | 09h | 15h | 21h | 03h | 09h | 15h | 21h | 03h | 09h | 15h | 21h | 03h | 09h | 15h | 21h | 03h | 09h | 15h | 21h | 03h | 09h | 15h | 21h | 03h | 09h | 15h | 21h |
| Météo | | | | | | | | | | | | | | | | | | | | | | | | | | | | |
| Vent (km/h) | 20 | 20 | 30 | 25 | 25 | 20 | 55 | 25 | 20 | 25 | 30 | 45 | 35 | 40 | 25 | 30 | 35 | 20 | 30 | 45 | 30 | 25 | 20 | 15 | 20 | 25 | 20 | 15 |
| à 3000m | | | | | | | | | | | | | | | | | | | | | | | | | | | | |
| Vent (km/h) | 15 | 15 | 20 | 10 | 5 | 10 | 15 | 5 | 5 | 10 | 10 | 15 | 35 | 25 | 20 | 10 | 15 | 15 | 20 | 25 | 20 | 10 | 15 | 10 | 5 | 10 | 2 | 5 |
| à 2000m | | | | | | | | | | | | | | | | | | | | | | | | | | | | |

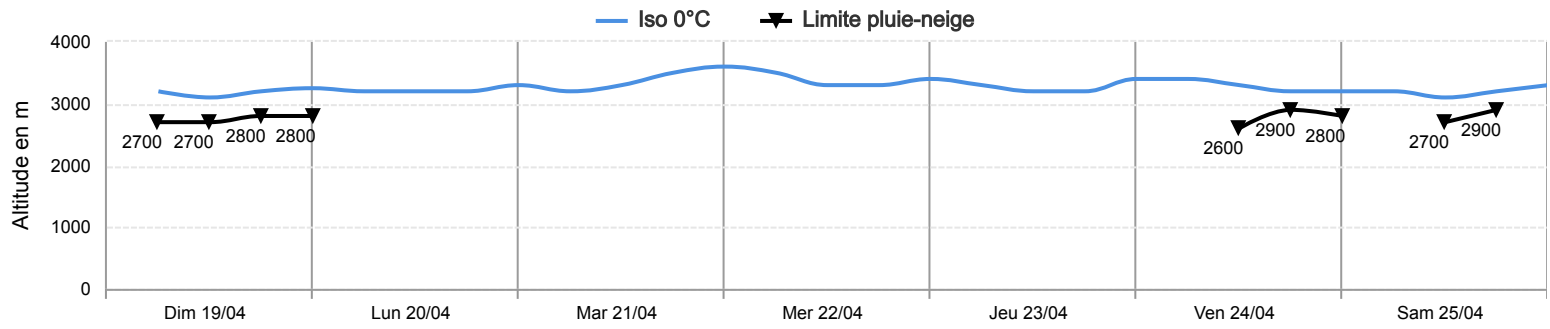


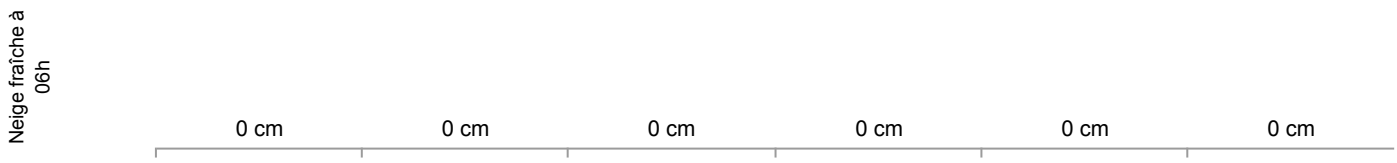


| Risque d'avalanche | dim. 19/04 | lun. 20/04 | mar. 21/04 | mer. 22/04 | jeu. 23/04 | ven. 24/04 | sam. 25/04 |
|---|---|---|---|---|---|---|---|
| | 2 | 2 | 2 | 3 | 3 | 3 | 3 |

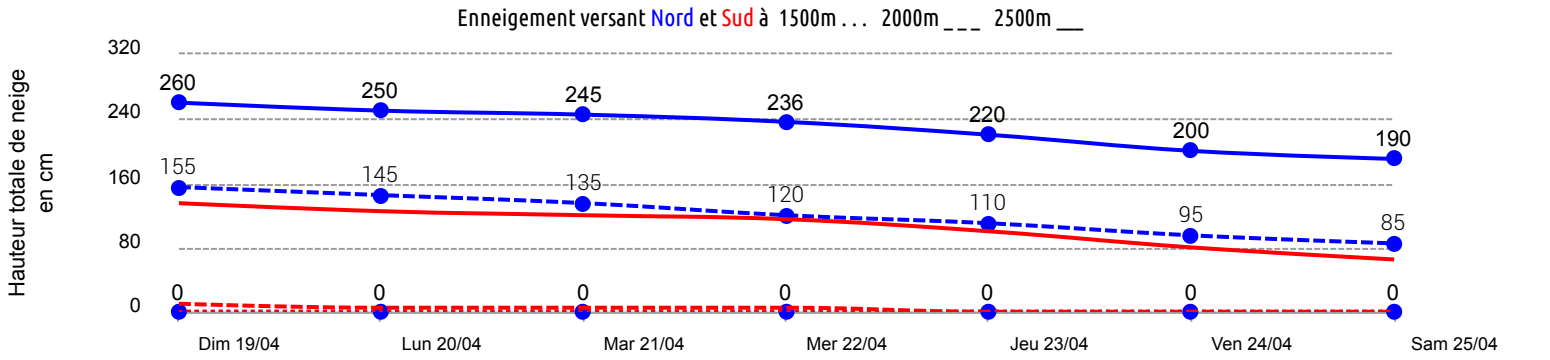


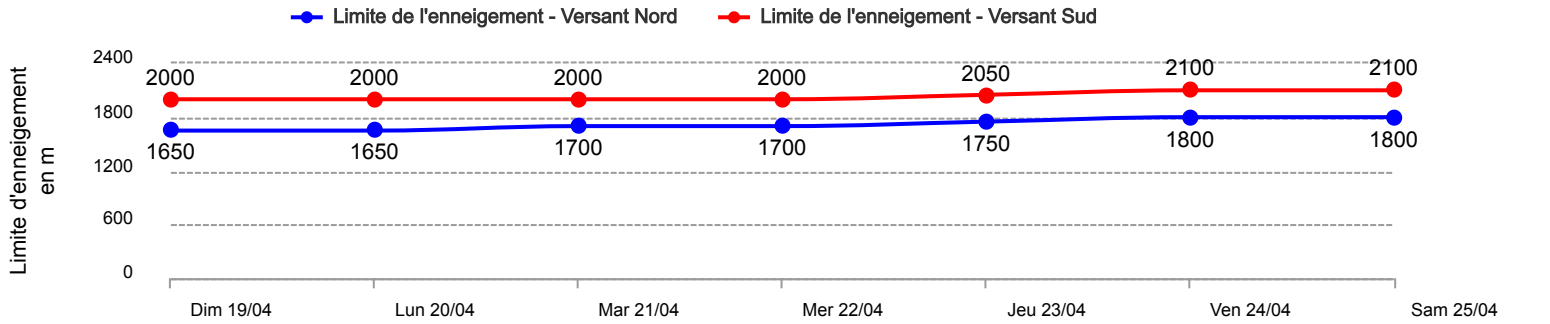


Pour consulter la vigilance en cours, veuillez vous rendre sur le site https://vigilance.meteofrance.fr/fr


**Météo-France - 73 avenue de Paris, 94165 Saint-Mandé cedex - Contact : contact@meteo.fr**


Rédigé par Météo-France avec la contribution des observateurs du réseau nivo-météorologiques. Partenariat : ANMSM (Maires de Stations de Montagne), DSF (Domaines Skiables de France), ADSP (Directeurs de Pistes et de la Sécurité des Stations de Sports d'Hiver) et autres acteurs de la montagne.

**Bulletin neige & avalanches par téléphone au**

**0 892 68 10 20** Service 0,35 € / min + prix appel