GOBIERNO DE ESPAÑA
VICEPRESIDENCIA TERCERA DEL GOBIERNO
MINISTERIO PARA LA TRANSICIÓN ECOLÓGICA Y EL RETO DEMOGRÁFICO

Boletín de información nivológica y de peligro de aludes

Pirineo Navarro y Aragonés

aemet Agencia Estatal de Meteorología

domingo, 26 de abril de 2026

Pronóstico hasta las 24 horas del lunes, día 27 de abril

(Válido fuera de pistas de esquí balizadas y abiertas)

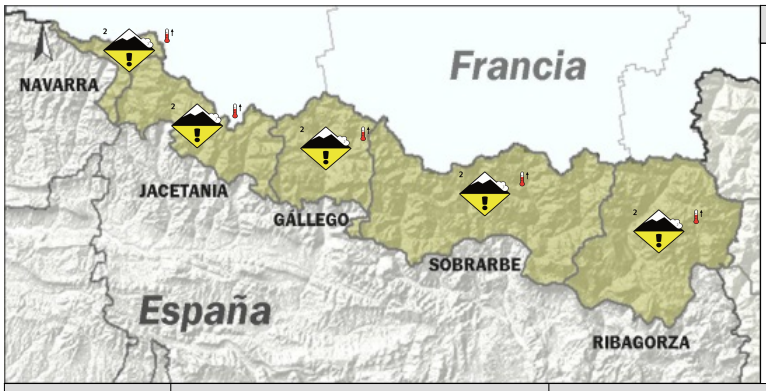

Problemas de aludes

Nieve húmeda

Deslizamientos basales

Macizo	Peligro	Problemas de aludes, cota, orientación, tamaño	Innivación observada (m)
Navarra	2 — 2 — Limitado	Nieve húmeda: N, O, E, S — 1 Deslizamientos basales: N, O, E, S — 2	2026-04-26 N / S Cota más baja caras N
Jacetania	2 — 2 — Limitado	Nieve húmeda: N, O, E, S — 2 Deslizamientos basales: N, O, E, S — 2	2026-04-26 N / S Cota más baja caras N
Gállego	2 — 2 — Limitado	Nieve húmeda: N, O, E, S — 2 Deslizamientos basales: N, O, E, S — 2	2026-04-26 N / S Cota más baja caras N

AEMET. Se autoriza la reproducción de su contenido citando la fuente.

Boletín de información nivológica y de peligro de aludes

Pirineo Navarro y Aragonés

Sobrarbe	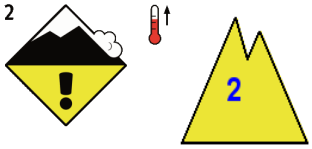 **Limitado**	**Nieve húmeda**  **Deslizamientos basales** 	2026-04-26 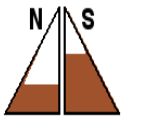 Cota más baja caras N
Ribagorza	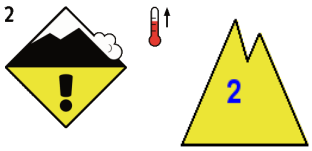 **Limitado**	**Nieve húmeda** **Deslizamientos basales** 	2026-04-26 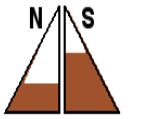 Cota más baja caras N

Estado del manto y observaciones recientes

Un día más a consecuencia de la insolación, las temperaturas elevadas y los chubascos vespertinos, que ayer resultaron ser bastante generalizados, prosiguen los procesos de merma y humidificación del manto nivoso. Este se halla básicamente restringido a las cotas altas y presenta una clara asimetría norte-sur, con solanas muy discontinuas. En cuanto a los espesores, pese al claro retroceso, todavía se reportan valores superiores a 80-100 cm en umbrías por encima de 2200 metros. La nieve está muy humidificada, con predominio del grano redondo y el enfriamiento nocturno no está permitiendo un rehielo efectivo.

Evolución del manto y peligro de aludes para el lunes, día 27

Problema de nieve húmeda. Problema de deslizamientos basales.

Ya durante la mañana se podrán producir algunos aludes de nieve húmeda en laderas lo suficientemente inclinadas. El peligro aumentará a lo largo del día con la insolación y las posibles precipitaciones. Estos aludes podrán ser naturales o accidentales y de tamaño pequeño o mediano.

También se podrá producir algún deslizamiento basal, preferentemente en laderas herbosas o de roca lisa con la suficiente inclinación, de tamaño mediano, aunque no se descarta que localmente pueda adquirir una dimensión mayor.

Predicción meteorológica para el lunes, día 27

Pirineo navarro:
Poco nuboso o despejado a primeras horas. A lo largo de la mañana, aumentará la nubosidad con el desarrollo de nubes de evolución diurna. Chubascos ocasionales durante la segunda mitad del día, que podrán ser tormentosos. Temperaturas sin cambios o en ligero ascenso.

AEMET. Se autoriza la reproducción de su contenido citando la fuente.

Viento flojo de dirección variable, con intervalos de moderado del sureste.

Pirineo aragonés:
Poco nuboso o despejado a primeras horas. A lo largo de la mañana, aumentará la nubosidad con el desarrollo de nubes de evolución diurna. Chubascos tormentosos durante la segunda mitad del día, que podrían ser localmente fuertes y con granizo. Temperaturas sin cambios o en ligero ascenso. Viento flojo, con predominio de la componente sur, que podrá soplar más intenso y racheado en áreas de chubasco.

Datos en la atmósfera libre:

Altitud de la isoterma de 0 ºC: 3300 m
Altitud de la isoterma de -10 ºC: 4700 m

Viento a 1500 m: S 10 km/h
Viento a 3000 m: S 10 km/h

Evolución para el martes día 28

Nivel de peligro con pocos cambios.

(Información elaborada a partir de los datos recibidos de los refugios de Linza, Lizara, Respomuso, Panticosa, Bachimaña, Góriz, Pineta, Estós, Angel Orús, La Renclusa y Cap de Llauset, de la estación de esquí de Panticosa (lagos) y de Ordesa Pradera)

Escala europea de peligro de aludes

Débil | Limitado | Notable | Fuerte | Muy Fuerte

Problemas de aludes

Nieve reciente | Placas de viento | Capas débiles persistentes | Nieve húmeda | Deslizamientos basales | Sin problema evidente

Nota1: Se recuerda que, siempre que haya nieve, la ausencia total de peligro no existe. Hay que tener presente que en circunstancias desfavorables, con aludes de tamaño 1 (alud pequeño o colada) y tamaño 2 (alud mediano), se pueden sufrir severos daños personales.

Nota2: Los BPA se elaboran en base a información meteorológica así como al estado del manto nivoso a través de sondeos puntuales. Se advierte a los usuarios de la variabilidad de esta información al extrapolarla a zonas extensas de montaña. Por ello, AEMET no se hace responsable de su uso para la toma de decisiones que conciernen a la seguridad personal, ni de los riesgos físicos o materiales de ellas derivadas.

AEMET. Se autoriza la reproducción de su contenido citando la fuente.