Montag 27.04.2026

Veröffentlicht am 26.04.2026 um 17:00

Vormittag

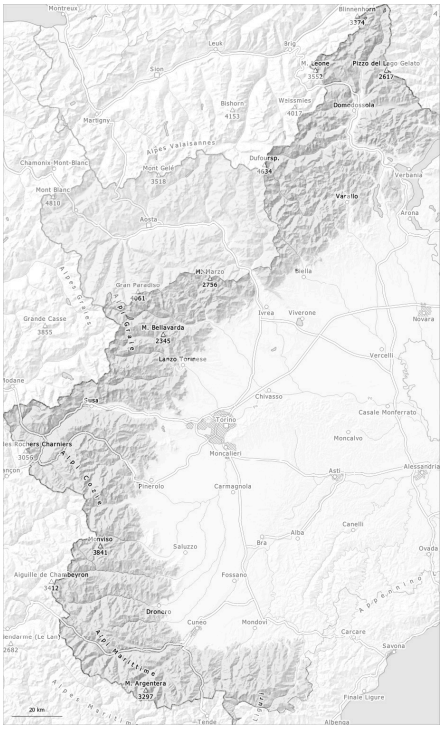

Nachmittag

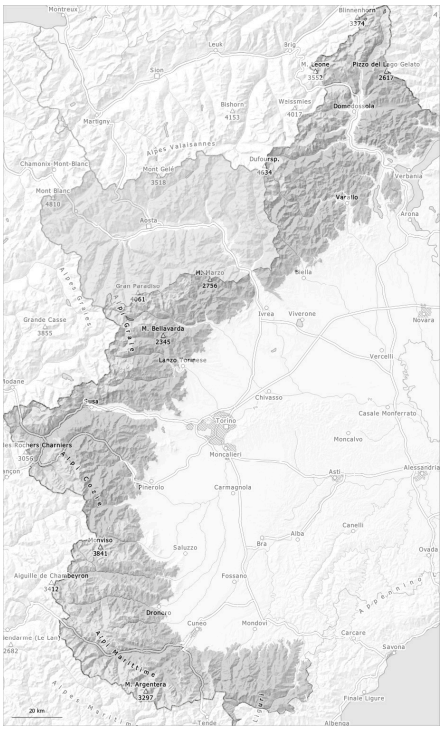

1	2	3	4	5
gering	mäßig	erheblich	groß	sehr groß

Gefahrenstufe 2 - Mäßig

AM:

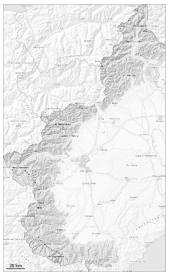

Tendenz: Lawinengefahr bleibt gleich
am Dienstag, den 28.04.2026

PM:

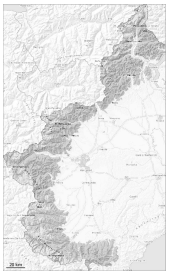

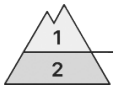

2900m

Tendenz: Lawinengefahr bleibt gleich
am Dienstag, den 28.04.2026

Nassschnee

2900m

Die Gefahr von feuchten und nassen Lawinen steigt im Tagesverlauf an.

Die Schneeoberfläche ist tragfähig gefroren und weicht schon am Vormittag auf.
Mit der tageszeitlichen Erwärmung und der Sonneneinstrahlung steigt die Lawinengefahr im Tagesverlauf allmählich an. Es sind nasse Rutsche und Lawinen möglich, auch mittelgroße. Dies vor allem an sehr steilen Nordhängen unterhalb von rund 2500 m und an sehr steilen Ost-, Süd- und Westhängen unterhalb von rund 2900 m.
Im Hochgebirge steigt die Gefahr von feuchten und nassen Lawinen innerhalb der Gefahrenstufe an.
Touren und Hüttenaufstiege sollten früh gestartet und rechtzeitig beendet werden.
Auf der harten Schneeoberfläche besteht im Steilgelände Absturzgefahr.

Schneedecke

Gefahrenmuster gm.10: frühjahrssituation

Mit starken Temperaturschwankungen verfestigte sich die Schneedecke. Dies vor allem an steilen Sonnenhängen in hohen Lagen und an allen Expositionen in mittleren Lagen. Die Schneedecke ist recht homogen, mit einer Schmelzharschkruste an der Oberfläche. Dies vor allem am Morgen.
Sonne und Wärme führen im Tagesverlauf zu einer zunehmenden Anfeuchtung der Schneedecke.
Unterhalb von rund 2200 m liegt an Südhängen nur wenig Schnee.