Montag 27.04.2026

Veröffentlicht am 26.04.2026 um 17:00

Vormittag

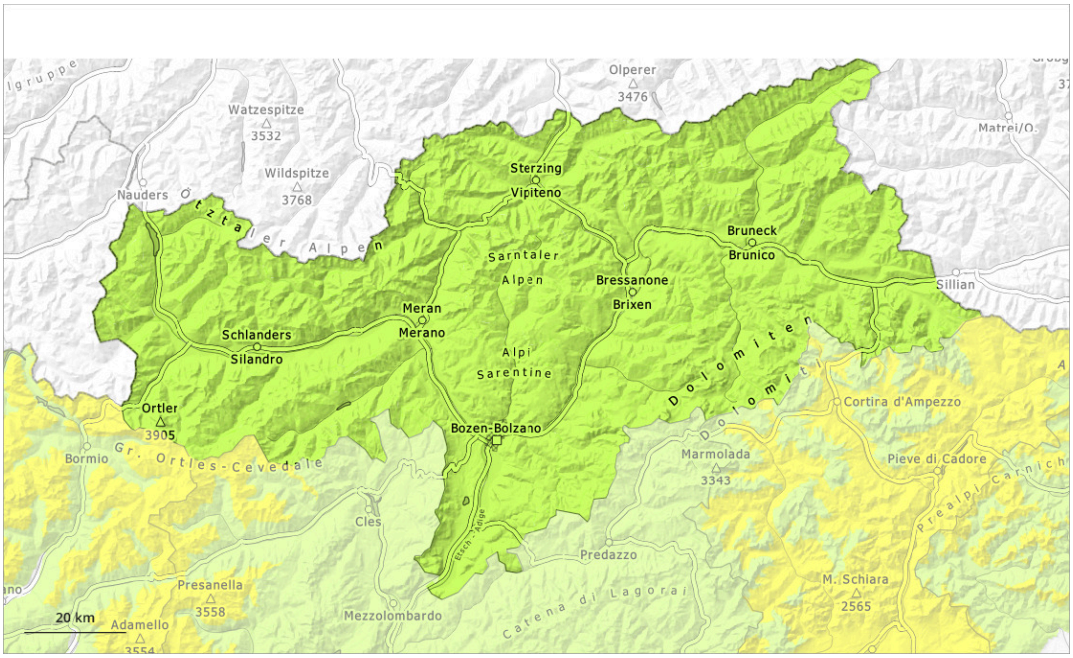

Nachmittag

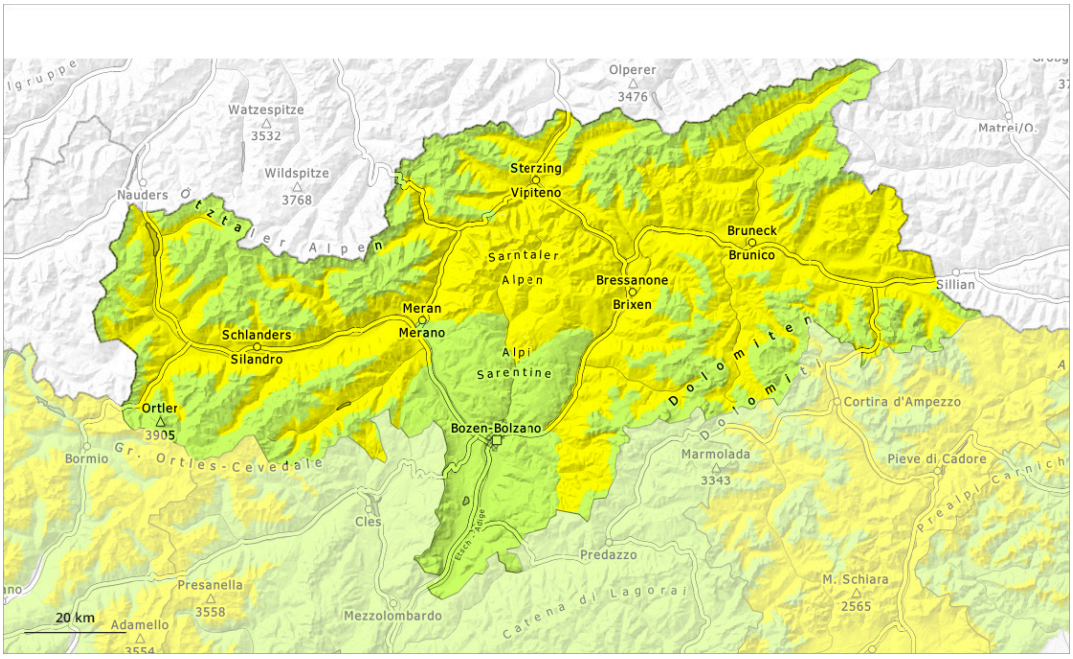

1	2	3	4	5
gering	mäßig	erheblich	groß	sehr groß

Gefahrenstufe 2 - Mäßig

AM:

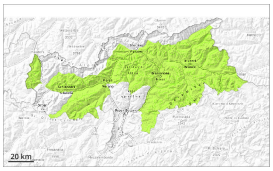

Tendenz: Lawinengefahr bleibt gleich
am Dienstag, den 28.04.2026

Altschnee

2500m

PM:

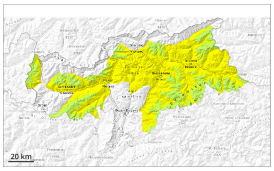

2800m

Tendenz: Lawinengefahr bleibt gleich
am Dienstag, den 28.04.2026

Nassschnee

2800m

Altschnee

2500m

Anstieg der Gefahr von nassen Lawinen im Tagesverlauf.

Mit der tageszeitlichen Erwärmung und der Sonneneinstrahlung steigt die Gefahr von nassen Lawinen im Tagesverlauf etwas an. Nasse Lawinen können vereinzelt von einzelnen Wintersportlern ausgelöst werden. Dies an sehr steilen Nordwest-, Nord- und Nordosthängen unterhalb von rund 2500 m sowie an sehr steilen West- und Osthängen unterhalb von rund 2800 m, vereinzelt aber auch an sehr steilen Sonnenhängen in der Höhe.

Gefahrenstellen für trockene Lawinen liegen an sehr steilen Schattenhängen oberhalb von rund 2500 m. Diese Stellen sind sehr selten aber schwer zu erkennen.

Schneedecke

Gefahrenmuster gm.10: frühjahrssituation | gm.1: bodennahe schwachschicht

Die nächtliche Abstrahlung ist zeitweise reduziert. Die Schneeoberfläche gefriert tragfähig und weicht schneller auf als am Vortag. Sonne und Wärme führen in mittleren und hohen Lagen zu einer allmählichen Anfeuchtung der Schneedecke.

Schattenhänge oberhalb von rund 2500 m: Im unteren Teil der Altschneedecke sind in der Höhe kantig aufgebaute Schwachschichten vorhanden.

An steilen Sonnenhängen sowie unterhalb von rund 1800 m liegt kaum Schnee.

Tendenz

Die nächtliche Abstrahlung ist reduziert. Die Gefahr von nassen Lawinen steigt schon am Morgen an.

Gefahrenstufe 2 - Mäßig

AM:

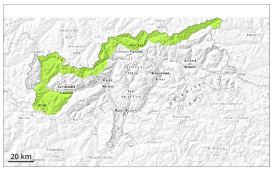

Tendenz: Lawinengefahr bleibt gleich
am Dienstag, den 28.04.2026

Altschnee

2500m

PM:

2800m

Tendenz: Lawinengefahr bleibt gleich
am Dienstag, den 28.04.2026

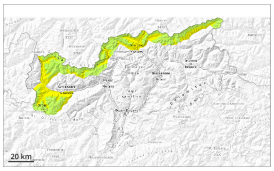

Nassschnee

2800m

Altschnee

2500m

Anstieg der Gefahr von nassen Lawinen im Tagesverlauf.

Mit der tageszeitlichen Erwärmung und der Sonneneinstrahlung steigt die Gefahr von nassen Lawinen im Tagesverlauf etwas an. Dies an sehr steilen Nordwest-, Nord- und Nordosthängen unterhalb von rund 2500 m sowie an sehr steilen West- und Osthängen unterhalb von rund 2800 m, vereinzelt aber auch an sehr steilen Sonnenhängen in der Höhe. Die Schneeoberfläche weicht schneller auf als am Vortag.
Nasse Lawinen können vereinzelt von einzelnen Wintersportlern ausgelöst werden. Diese können sehr vereinzelt den schwachen Altschnee mitreißen und groß werden. Dies an sehr steilen Schattenhängen unterhalb von rund 2500 m.

Zudem können sehr vereinzelt trockene Lawinen mit meist großer Belastung ausgelöst werden, besonders an sehr steilen Nordwest-, Nord- und Nordosthängen oberhalb von rund 2500 m. Die Gefahrenstellen sind sehr selten aber schwer zu erkennen.

Schneedecke

Gefahrenmuster gm.10: frühjahrssituation | gm.1: bodennahe schwachschicht

Die nächtliche Abstrahlung ist teilweise reduziert. Die Schneeoberfläche gefriert tragfähig und weicht schneller auf als am Vortag. Sonne und Wärme führen in mittleren und hohen Lagen zu einer allmählichen Anfeuchtung der Schneedecke.

Schattenhänge oberhalb von rund 2500 m: Im unteren Teil der Altschneedecke sind kantig aufgebaute Schwachschichten vorhanden.

In tiefen und mittleren Lagen liegt kaum Schnee.

Tendenz

Die nächtliche Abstrahlung ist reduziert. Die Gefahr von nassen Lawinen steigt bereits am Vormittag an.

Gefahrenstufe 1 - Gering

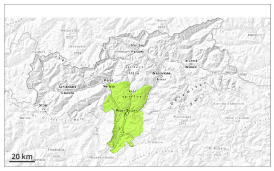

1

Tendenz: Lawinengefahr bleibt gleich
am Dienstag, den 28.04.2026

Nassschnee beachten.

Es sind nur noch vereinzelt nasse Lawinen möglich. Vorsicht an extrem steilen Schattenhängen. Lawinen sind meist eher klein.

Schneedecke

Gefahrenmuster gm.10: frühjahrssituation gm.1: bodennahe schwachschicht

Die nächtliche Abstrahlung ist stellenweise reduziert. Die Schneeoberfläche ist nur in hohen Lagen tragfähig gefroren und weicht rasch auf.

Tendenz

Geringe Lawinengefahr. Nassschnee beachten.