# Lunedì 27.04.2026

Pubblicato il 26.04.2026 alle ore 17:00

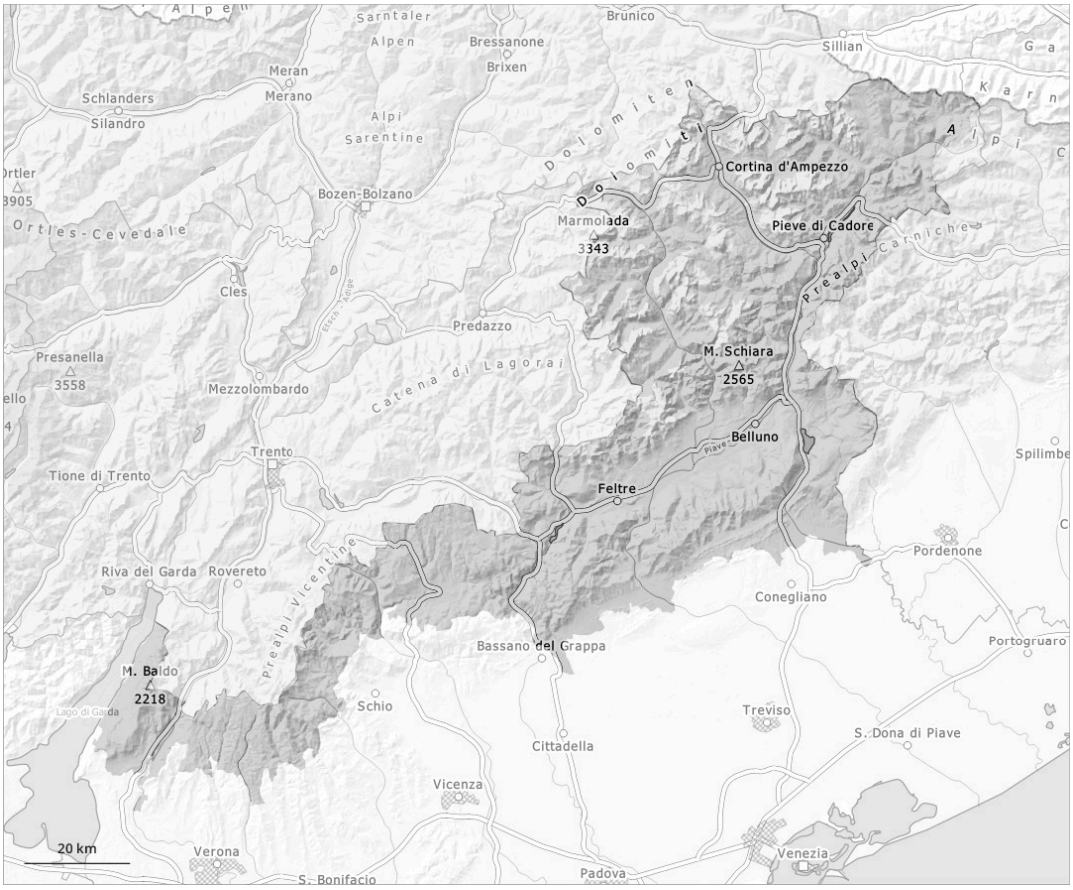


| 1 | 2 | 3 | 4 | 5 |
|---|---|---|---|---|
| debole | moderato | marcato | forte | molto forte |

## Grado di pericolo 2 - Moderato

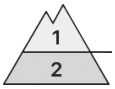


**2800m**

**Tendenza: pericolo valanghe stabile**
per Martedì il 28.04.2026

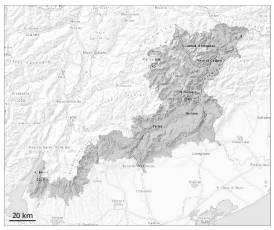

Neve bagnata

**2800m**

Strati deboli persistenti

**2500m**

## Il pericolo di valanghe bagnate sarà superiore già al mattino.

Con il rialzo termico e l'irradiazione solare diurni, a partire dal mattino il pericolo di valanghe bagnate aumenterà. Le valanghe bagnate possono a livello isolato distaccarsi in seguito al passaggio di un singolo appassionato di sport invernali. Ciò sui pendii ombreggiati molto ripidi al di sotto dei 2800 m circa, come pure sui pendii soleggiati molto ripidi in quota.

Isolati punti pericolosi per valanghe asciutte si trovano sui pendii ombreggiati molto ripidi al di sopra dei 2500 m circa. Sfavorevoli sono principalmente i punti di passaggio da poca a molta neve, (--). I punti pericolosi sono difficili da individuare.

## Manto nevoso

**Situazione tipo** st.10: situazione primaverile | st.1: strato debole persistente basale

La superficie del manto nevoso riuscirà a rigelarsi e a essere portante solo ad alta quota e si ammorbidirà rapidamente. Il sole e il calore causeranno alle quote medie e alte un rapido inumidimento del manto nevoso.

Sui pendii ombreggiati al di sopra dei 2500 m circa: In quota, nella parte basale del manto di neve vecchia si trovano strati fragili a cristalli angolari.

Soprattutto sulle Prealpi così come al di sotto dei 1800 m circa c'è solo poca neve. A livello locale, cadrà poca neve.

## Tendenza

L'irraggiamento notturno sarà ridotto. Il pericolo di valanghe bagnate sarà superiore già al mattino. A livello locale cadranno da 5 a 15 cm di neve al di sopra dei 2500 m circa.