Bulletin d'estimation du risque d'avalanche

(valable en dehors des pistes balisées et ouvertes)

MASSIF : Pays-Basque

Rédigé le dimanche 26 avril 2026 à 15h

Estimation des risques pour le : LUNDI 27 AVRIL

MANTEAU NEIGEUX HUMIDE ET TASSE.

1

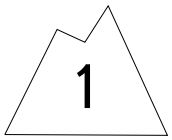

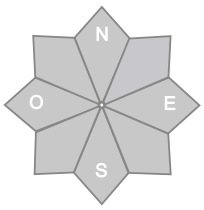

Indice de risque faible.

Départs spontanés : en neige humide.

Déclenchements provoqués : en neige humide.

Indices de risque : 5 très fort - 4 fort - 3 marqué - 2 limité - 1 faible -- En noir : les pentes les plus dangereuses

Stabilité du manteau neigeux

Situation avalancheuse typique : neige humide avalanches de fond

Départs spontanés : manteau neigeux humidifié sur toute son épaisseur, présent en versants nord seulement, pas de regel nocturne.
Très peu voire pas d'activité au petit matin, puis **quelques coulées de neige humide à détrempée** sous les **éclaircies du début de matinée**, puis les **averses orageuses à partir de la mi-journée**.
Manteau neigeux tassé, mais, **l'humidification pénétrant en profondeur** au cours de la journée, de **rares avalanches de fond de taille moyenne** restent **possibles dans l'après-midi et en fin de journée** dans les **pentes nord du Pic d'Anie.**
Dans le secteur d'Iraty et du pic d'Orhy, seuls quelques névés persistent en pentes raides nord.

Déclenchements provoqués : seulement en neige humide.
Dans la grande majorité des pentes nord du massif où il reste de la neige, plutôt de type névé maintenant, déclenchement difficile de coulées de neige humide.
Cependant, dans les pentes nord du Pic d'Anie, un skieur ou randonneur peut facilement déclencher une coulée de neige très humide à détrempée en coupant une pente raide, très localement une avalanche de fond petite à moyenne au plus fort de l'humidification.

Autres : **corniches et ponts de neige** encore en place **fragiles et peu résistants**, pouvant **céder** dès le matin **spontanément** ou sous le **poids d'une seule personne**.

Qualité de la neige

Enneigement : encore correct autour du pic d'Anie, débutant vers 1800m en nord et de très rares névés en sud.
La fonte du manteau neigeux, moins marquée que les jours précédents, se poursuit, les limites de cet enneigement remontent lentement dans la douceur ambiante, sous les éclaircies matinales et les averses de l'après-midi. Sous le pic d'Orhy en face nord, seuls des névés persistent.
État de la neige : pas de regel nocturne, manteau neigeux humidifié sur toute son épaisseur, humide mais portant au lever du jour, devenant rapidement gorgé d'eau et très mou au cours de la journée.

Aperçu météo pour le lundi 27 avril

	nuit	matin	après-midi	soir
	Eclaircies en début de matinée, nuages se développant ensuite, donnant des averses orageuses pour l'après-midi.			
Pluie-Neige		2 800 m	2 900 m	2 800 m
Iso 0 °C	3 300 m	3 100 m	3 200 m	3 100 m
Vent 1000 m	↑ 5 km/h	↓ 10 km/h	↓ 5 km/h	↻ 5 km/h
Vent 2000 m	↗ 20 km/h	↑ 20 km/h	↗ 25 km/h	↑ 30 km/h

Épaisseur de neige hors-piste

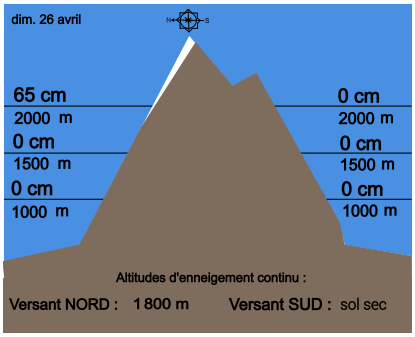

Précipitations à 1800 m

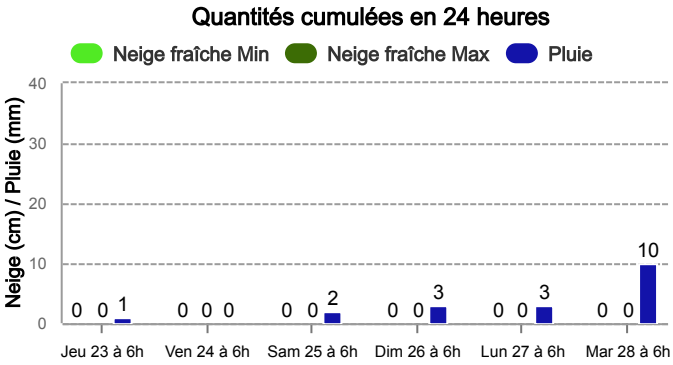

Tendance du mardi 28 avril

1

Indice de risque faible

Sans évolution notable des conditions météorologiques, le risque restera faible sur le massif.

Pour consulter la vigilance en cours, veuillez vous rendre sur le site https://vigilance.meteofrance.fr/fr

Météo-France - 73 avenue de Paris, 94165 Saint-Mandé cedex - Contact : contact@meteo.fr

Rédigé par Météo-France avec la contribution des observateurs du réseau nivo-météorologiques. Partenariat : ANMSM (Maires de Stations de Montagne), DSF (Domaines Skiables de France), ADSP (Directeurs de Pistes et de la Sécurité des Stations de Sports d'Hiver) et autres acteurs de la montagne.

Bulletin neige & avalanches par téléphone au **0 892 68 10 20** Service 0,35 € / min + prix appel

RÉPUBLIQUE FRANÇAISE
Liberté Égalité Fraternité

METEO FRANCE
À VOS CÔTÉS, DANS UN CLIMAT QUI CHANGE

Bulletin d'estimation du risque d'avalanche

(valable en dehors des pistes balisées et ouvertes)

MASSIF : Pays-Basque

Rédigé le dimanche 26 avril 2026 à 15h

Conditions nivo-météo des 7 derniers jours

	lun. 20/04				mar. 21/04				mer. 22/04				jeu. 23/04				ven. 24/04				sam. 25/04				dim. 26/04			
	03h	09h	15h	21h	03h	09h	15h	21h	03h	09h	15h	21h	03h	09h	15h	21h	03h	09h	15h	21h	03h	09h	15h	21h	03h	09h	15h	21h
Météo																												
Vent (km/h)	30	25	35	30	25	30	35	55	70	50	25	20	35	30	25	65	70	60	20	10	10	10	15	20	20	15	20	20
à 2000m																												
Vent (km/h)	5	5	15	10	10	10	10	15	40	30	25	10	10	20	20	30	30	25	10	10	10	10	10	5	5	10	10	2
à 1000m																												

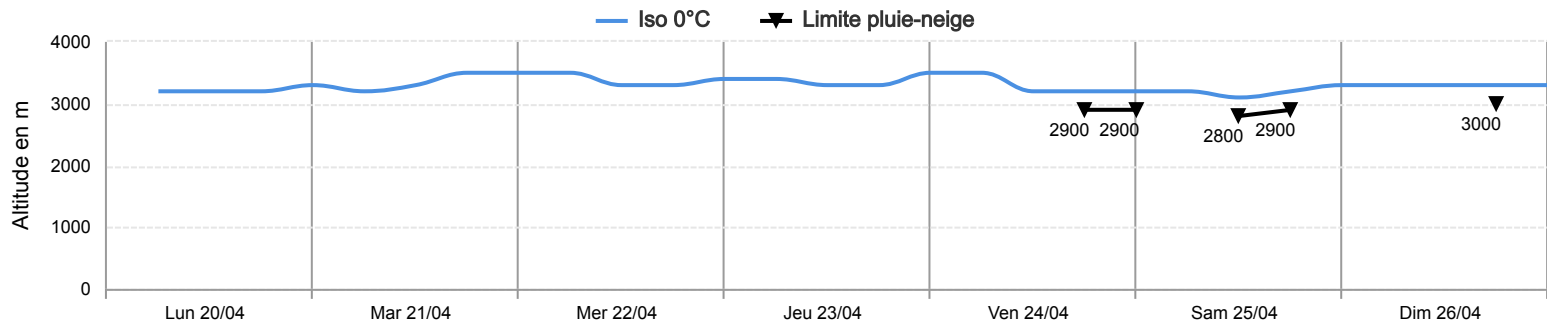

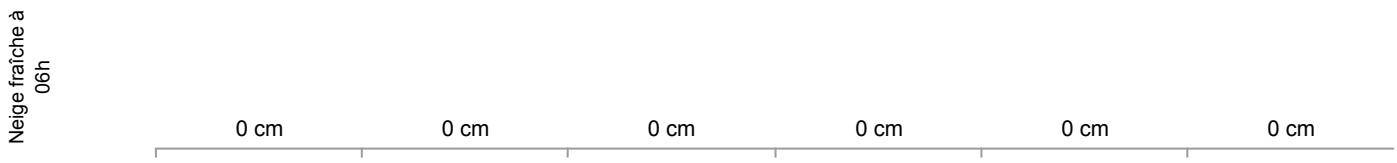

Risque d'avalanche	lun. 20/04	mar. 21/04	mer. 22/04	jeu. 23/04	ven. 24/04	sam. 25/04	dim. 26/04
	2	2	2	2	2	1	1

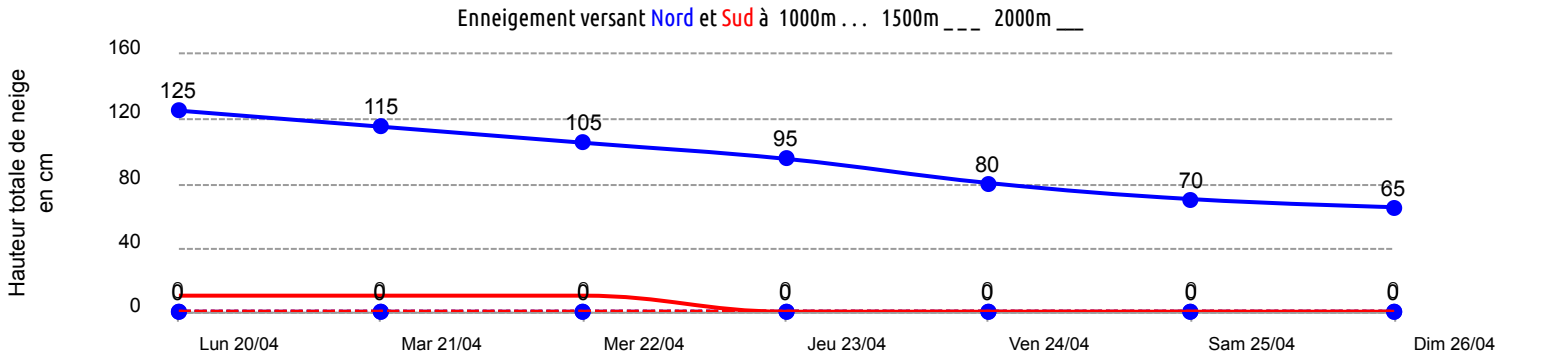

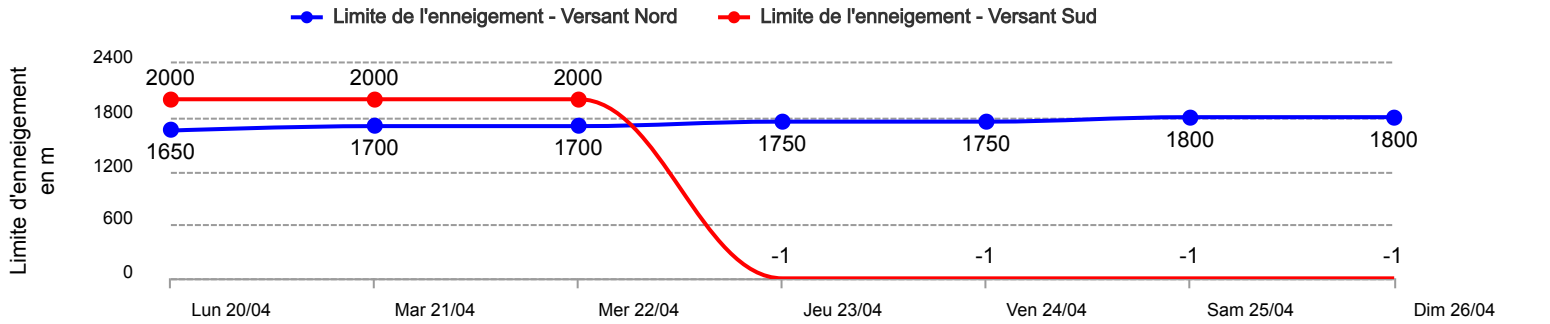

Pour consulter la vigilance en cours, veuillez vous rendre sur le site https://vigilance.meteofrance.fr/fr

Météo-France - 73 avenue de Paris, 94165 Saint-Mandé cedex - Contact : contact@meteo.fr

Rédigé par Météo-France avec la contribution des observateurs du réseau nivo-météorologiques. Partenariat : ANMSM (Maires de Stations de Montagne), DSF (Domaines Skiables de France), ADSP (Directeurs de Pistes et de la Sécurité des Stations de Sports d'Hiver) et autres acteurs de la montagne.

Bulletin neige & avalanches par téléphone au

0 892 68 10 20 Service 0,35 € / min + prix appel