Bulletin d'estimation du risque d'avalanche
(valable en dehors des pistes balisées et ouvertes)

MASSIF : Bauges

Rédigé le dimanche 26 avril 2026 à 16h

Estimation des risques pour le : LUNDI 27 AVRIL

CONDITIONS PRINTANIÈRES

1

1

N O E S

Indice de risque faible.

Départs spontanés : avalanche de neige humide

Déclenchements provoqués : petits départs en neige humide sous les skis

Indices de risque : 5 très fort - 4 fort - 3 marqué - 2 limité - 1 faible -- En noir : les pentes les plus dangereuses

Stabilité du manteau neigeux

Situation avalancheuse typique : neige humide avalanches de fond

Départs spontanés :
* rares avalanches de neige humide, un peu plus nombreuses au fil du réchauffement et du rayonnement solaire. Taille 1 (petite).
* rares plaques de fond dans les zones herbeuses ou les dalles rocheuses, à toute heure du jour ou de la nuit. Taille 2 (moyenne).

Déclenchements provoqués :
* départ ponctuel en neige humide, sous les skis. Taille 1. Causé par le réchauffement et le rayonnement solaire.

Qualité de la neige

Enneigement :
Pour la saison, l'enneigement est correct.
On peut chausser les skis au-dessus de 1700 m en nord. Les versants sud sont secs.

Qualité de la neige ce lundi matin : neige de névé avec un bon regel nocturne

Aperçu météo pour le lundi 27 avril

	nuit	matin	après-midi	soir
	ensoleillé. Cumulus au-dessus du relief l'après-midi. Au maximum 12°C à 2000 m.			
Pluie-Neige				
Iso 0 °C	3 100 m	3 200 m	3 100 m	3 000 m
Vent 1500 m	5 km/h	5 km/h	10 km/h	10 km/h
Vent 2000 m	10 km/h	5 km/h	10 km/h	15 km/h

Épaisseur de neige hors-piste

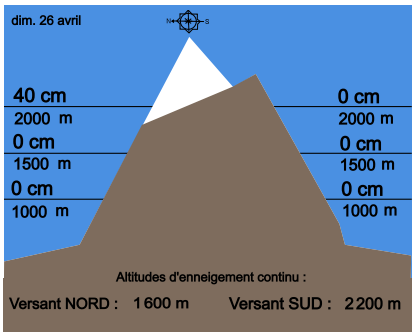

Précipitations à 1800 m

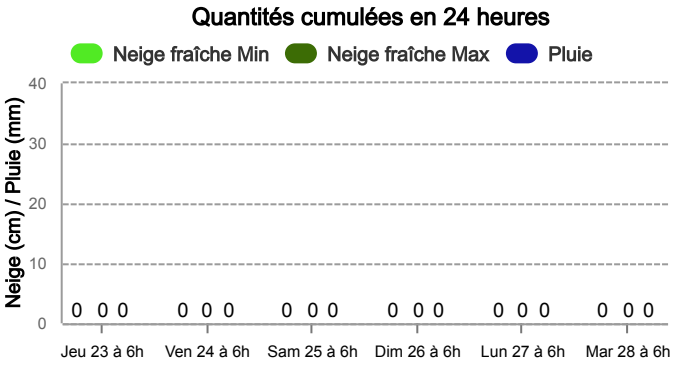

Tendance du mardi 28 avril

1

Indice de risque faible

Mardi : temps nuageux avec des averses localement orageuses.
⇒ mauvais regel nocturne. Rares avalanches en neige humide possible dès le début de matinée, surtout sous les averses.

Pour consulter la vigilance en cours, veuillez vous rendre sur le site https://vigilance.meteofrance.fr/fr

Météo-France - 73 avenue de Paris, 94165 Saint-Mandé cedex - Contact : contact@meteo.fr

Rédigé par Météo-France avec la contribution des observateurs du réseau nivo-météorologiques. Partenariat : ANMSM (Maires de Stations de Montagne), DSF (Domaines Skiables de France), ADSP (Directeurs de Pistes et de la Sécurité des Stations de Sports d'Hiver) et autres acteurs de la montagne.

Bulletin neige & avalanches par téléphone au 0 892 68 10 20 Service 0,35 € / min + prix appel

Bulletin d'estimation du risque d'avalanche

(valable en dehors des pistes balisées et ouvertes)

MASSIF : Bauges

Rédigé le dimanche 26 avril 2026 à 16h

Conditions nivo-météo des 7 derniers jours

	lun. 20/04				mar. 21/04				mer. 22/04				jeu. 23/04				ven. 24/04				sam. 25/04				dim. 26/04			
	03h	09h	15h	21h	03h	09h	15h	21h	03h	09h	15h	21h	03h	09h	15h	21h	03h	09h	15h	21h	03h	09h	15h	21h	03h	09h	15h	21h
Météo																												
Vent (km/h)	20	25	30	20	20	20	30	20	20	15	10	10	10	10	10	10	10	10	10	10	15	10	20	25	10	15	15	10
à 2000m																												
Vent (km/h)	10	15	20	10	10	15	20	10	10	10	5	5	5	5	5	5	5	5	5	5	5	5	15	15	5	10	10	10
à 1500m																												

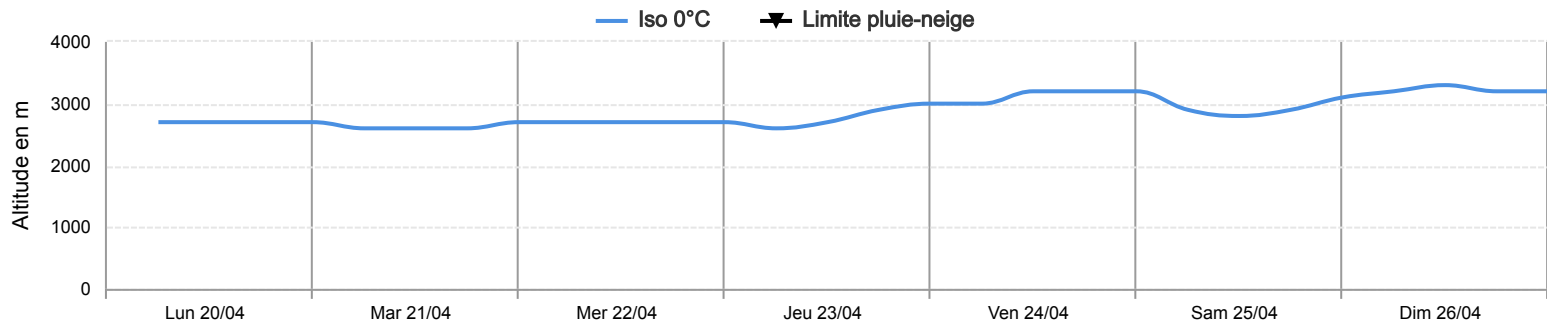

Neige fraîche à 06h

Lun 20/04	Mar 21/04	Mer 22/04	Jeu 23/04	Ven 24/04	Sam 25/04
0 cm	0 cm	0 cm	0 cm	0 cm	0 cm

Risque d'avalanche	lun. 20/04	mar. 21/04	mer. 22/04	jeu. 23/04	ven. 24/04	sam. 25/04	dim. 26/04
	1	1	1	1	1	1	1

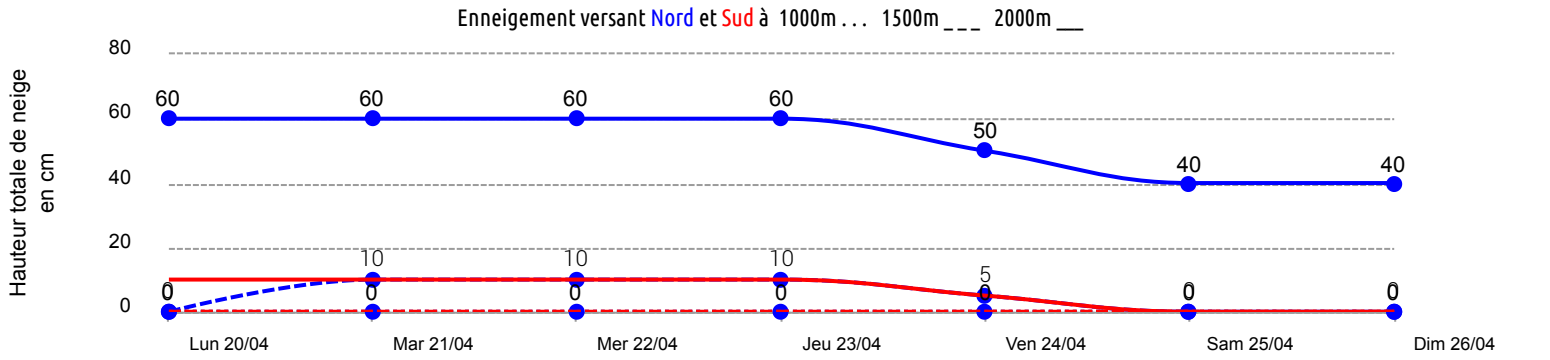

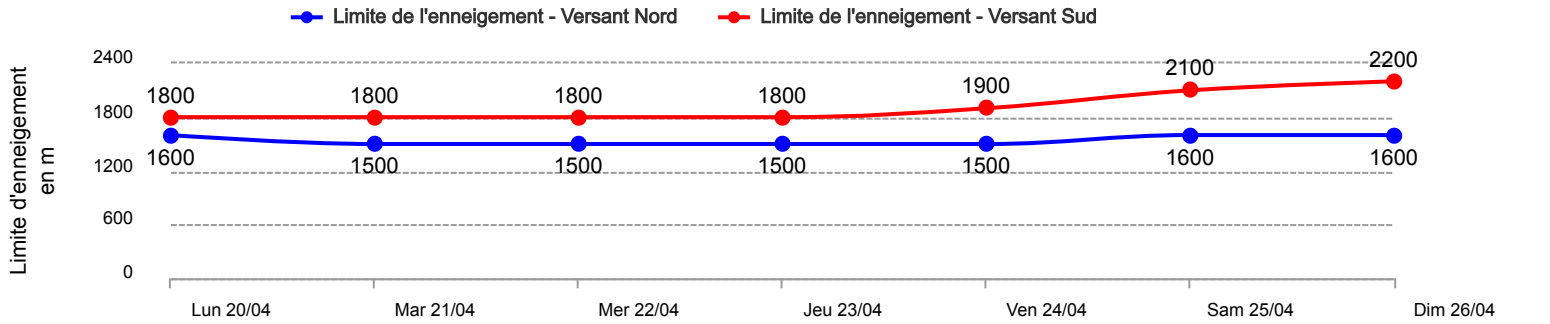

Pour consulter la vigilance en cours, veuillez vous rendre sur le site https://vigilance.meteofrance.fr/fr

Météo-France - 73 avenue de Paris, 94165 Saint-Mandé cedex - Contact : contact@meteo.fr

Bulletin neige & avalanches par téléphone au 0 892 68 10 20 Service 0,35 € / min + prix appel

Rédigé par Météo-France avec la contribution des observateurs du réseau nivo-météorologiques. Partenariat : ANMSM (Maires de Stations de Montagne), DSF (Domaines Skiables de France), ADSP (Directeurs de Pistes et de la Sécurité des Stations de Sports d'Hiver) et autres acteurs de la montagne.