Bulletin d'estimation du risque d'avalanche

(valable en dehors des pistes balisées et ouvertes)

MASSIF : Haut-Var Haut-Verdon

Rédigé le dimanche 26 avril 2026 à 16h

Estimation des risques pour le : LUNDI 27 AVRIL

MANTEAU NEIGEUX PRINTANIER - UN PEU D'ACTIVITÉ NATURELLE EN NEIGE HUMIDE

2

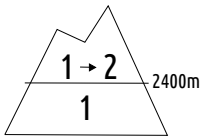

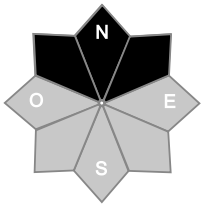

Au-dessus de 2400m indice de risque faible évoluant en limité, plus bas indice faible.

Départs spontanés : quelques avalanches de neige humide, généralement de petite taille - rare avalanche volumineuse possible en ubacs d'altitude.

Déclenchements provoqués : en neige humide sous les skis.

Indices de risque : 5 très fort - 4 fort - 3 marqué - 2 limité - 1 faible -- En noir : les pentes les plus dangereuses

Stabilité du manteau neigeux

Situation avalancheuse typique : neige humide

Départs spontanés : après regel nocturne correct, l'activité en neige humide reprend en cours de journée sous l'effet de la douceur et des averses de pluie. Quelques avalanches généralement superficielles sont alors possibles par départ ponctuel, de petite taille (taille 1). De rares départs linéaires plus volumineux sont possibles dans les pentes nord-ouest à nord-est au-dessus de 2400/2500 m environ, emportant la totalité du manteau neigeux en place. Taille moyenne, grande non exclue.

Déclenchements provoqués : un skieur coupant tardivement une pente raide peut initier un départ de neige humide sous ses skis, généralement de petite taille.
Dans les ubacs d'altitude au-dessus de 2400/2500 m, une première avalanche superficielle de neige humide peut dans de très rares cas provoquer un seconde départ plus volumineux sous forme linéaire.

Qualité de la neige

Enneigement nettement déficitaire pour la période, avec une fonte qui se poursuit à un rythme élevé. Absence de précipitations significatives depuis plus d'un mois et grande douceur en place depuis début avril.

Enneigement skiable généralement à partir de 2000 m en ubacs sur terrain favorable (routes forestières, terrains herbeux) et plus de 2400/2500 m en adrets.

État de la neige en surface : manteau neigeux printanier, voire de névé en toute orientation sous 2300/2500 m et en adrets d'altitude. Bon regel nocturne, puis reprise rapide de l'humidification et de la fonte en cours de journée dans toutes les expositions. La neige peut rester dure dans les pentes nord raides de haute altitude.

Aperçu météo pour le lundi 27 avril

	nuit	matin	après-midi	soir
Temps doux avec un risque d'averses l'après-midi. 13° à 2000 m et 6° à 3000 m.				
Pluie-Neige	2 800 m			
Iso 0 °C	3 200 m	3 100 m	3 100 m	3 200 m
Vent 2000 m	↓ 5 km/h	↑ 10 km/h	↗ 20 km/h	↓ 10 km/h
Vent 3000 m	↓ 10 km/h	↑ 15 km/h	↗ 20 km/h	↗ 20 km/h

Épaisseur de neige hors-piste

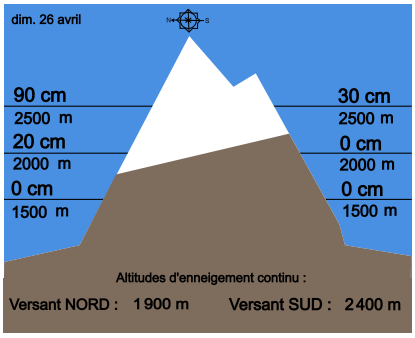

Précipitations à 1800 m

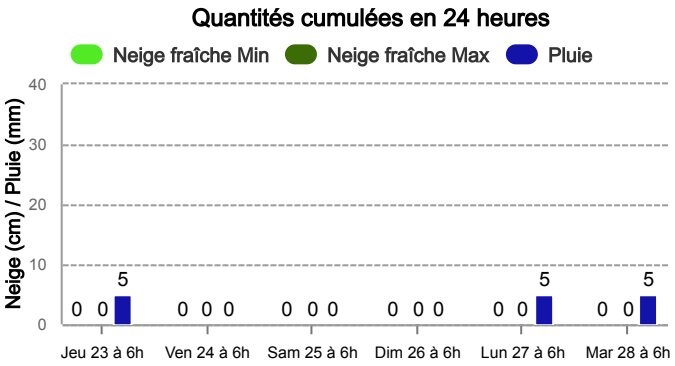

Tendance du mardi 28 avril

2

Indice de risque limité

Maintien d'un risque limité avec à nouveau un regel nocturne puis la poursuite de l'humidification et de la fonte du manteau neigeux.

Pour consulter la vigilance en cours, veuillez vous rendre sur le site https://vigilance.meteofrance.fr/fr

Météo-France - 73 avenue de Paris, 94165 Saint-Mandé cedex - Contact : contact@meteo.fr

Rédigé par Météo-France avec la contribution des observateurs du réseau nivo-météorologiques. Partenariat : ANMSM (Maires de Stations de Montagne), DSF (Domaines Skiables de France), ADSP (Directeurs de Pistes et de la Sécurité des Stations de Sports d'Hiver) et autres acteurs de la montagne.

Bulletin neige & avalanches par téléphone au 0 892 68 10 20 Service 0,35 € / min + prix appel

RÉPUBLIQUE FRANÇAISE
Liberté Égalité Fraternité

METEO FRANCE
À VOS CÔTÉS, DANS UN CLIMAT QUI CHANGE

Bulletin d'estimation du risque d'avalanche

(valable en dehors des pistes balisées et ouvertes)

MASSIF : Haut-Var Haut-Verdon

Rédigé le dimanche 26 avril 2026 à 16h

Conditions nivo-météo des 7 derniers jours

	lun. 20/04				mar. 21/04				mer. 22/04				jeu. 23/04				ven. 24/04				sam. 25/04				dim. 26/04			
	03h	09h	15h	21h	03h	09h	15h	21h	03h	09h	15h	21h	03h	09h	15h	21h	03h	09h	15h	21h	03h	09h	15h	21h	03h	09h	15h	21h
Météo																												
Vent (km/h)	25	30	35	25	30	30	40	40	35	30	30	25	15	15	20	20	15	10	15	15	15	15	20	10	10	15	20	10
à 3000m																												
Vent (km/h)	20	20	30	20	20	20	30	15	15	20	25	15	10	15	20	10	10	10	20	10	10	10	25	10	10	10	20	10
à 2000m																												

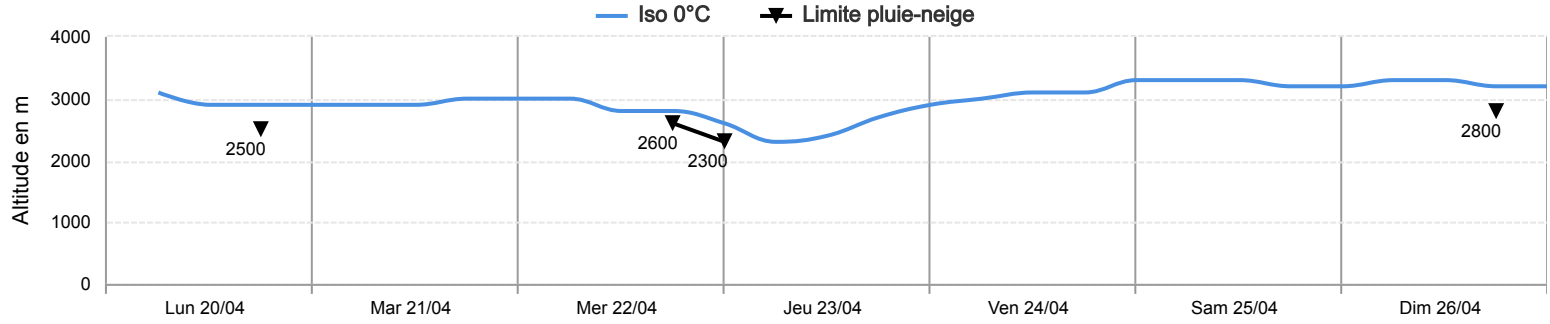

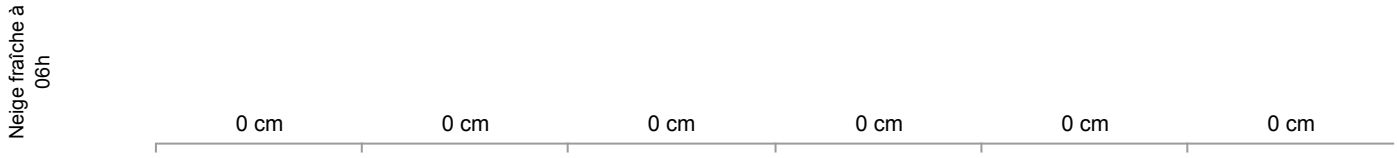

Risque d'avalanche	lun. 20/04	mar. 21/04	mer. 22/04	jeu. 23/04	ven. 24/04	sam. 25/04	dim. 26/04
	2	2	2	2	2	2	2

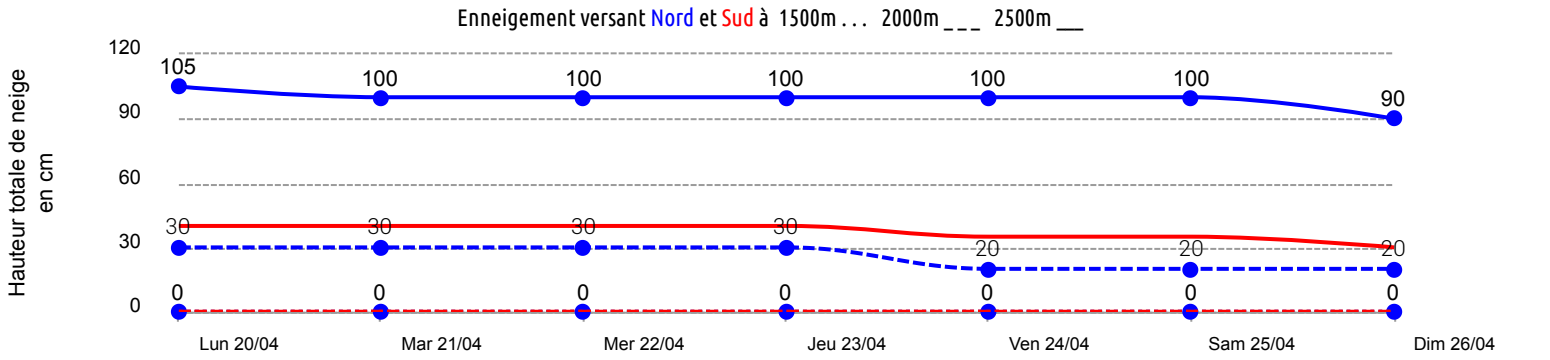

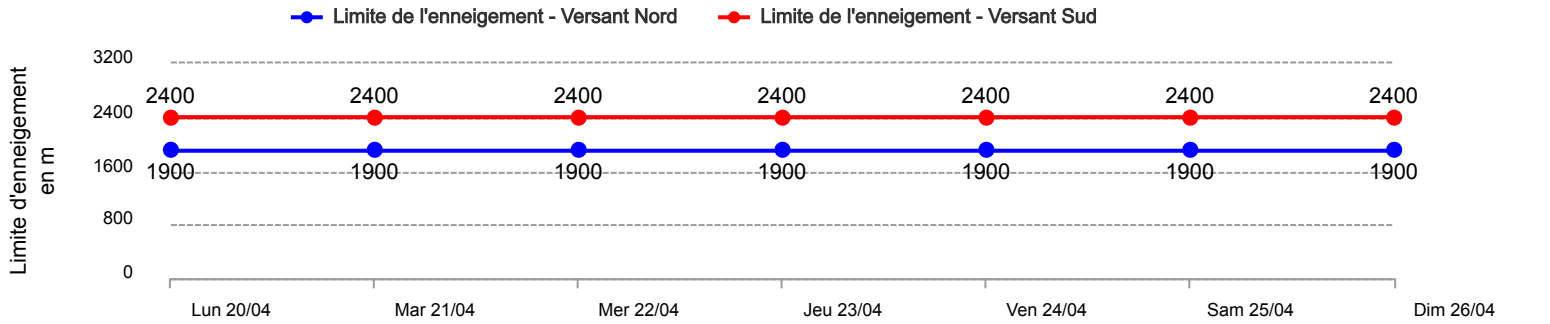

Pour consulter la vigilance en cours, veuillez vous rendre sur le site https://vigilance.meteofrance.fr/fr

Météo-France - 73 avenue de Paris, 94165 Saint-Mandé cedex - Contact : contact@meteo.fr

Rédigé par Météo-France avec la contribution des observateurs du réseau nivo-météorologiques. Partenariat : ANMSM (Maires de Stations de Montagne), DSF (Domaines Skiables de France), ADSP (Directeurs de Pistes et de la Sécurité des Stations de Sports d'Hiver) et autres acteurs de la montagne.

Bulletin neige & avalanches par téléphone au

0 892 68 10 20 Service 0,35 € / min + prix appel