Bulletin d'estimation du risque d'avalanche

(valable en dehors des pistes balisées et ouvertes)

MASSIF : Vercors

Rédigé le dimanche 26 avril 2026 à 16h

Estimation des risques pour le : LUNDI 27 AVRIL

MANTEAU NEIGEUX TRES DENSE, STABLE..

1

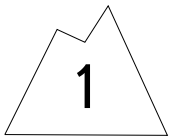

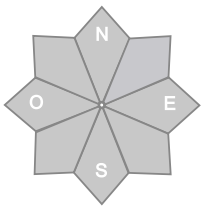

Indice de risque faible.

Départs spontanés : Peu probables.

Déclenchements provoqués : Peu probables. Attention le matin aux surfaces durcies par regel.

Indices de risque : 5 très fort - 4 fort - 3 marqué - 2 limité - 1 faible -- En noir : les pentes les plus dangereuses

Stabilité du manteau neigeux

Situation avalancheuse typique : pas de situation prédominante

De moins en moins de neige en place et très dense, presque de névé, donc stable même lorsqu'elle est humide en journée...
Départs spontanés : Peu probables, ou très rare coulée humide en pente bien raide. Noter aussi un peu de regel nocturne possible.
Déclenchements provoqués : Peu probables, ou de manière très rare sous les skis en neige humide dans une pente réchauffée.

Autres : Surfaces temporairement durcies en cas de regel nocturne, pouvant être glissantes.

Qualité de la neige

Qualification de l'enneigement : L'enneigement s'est fortement réduit depuis 3 semaines et devient déficitaire pour la saison. Au Sud il ne reste plus que de rares névés... la fin de saison approche.
Limites skiables : Vers 1500 à 2000m environ suivant l'exposition, la raideur de la pente...

Qualité de la neige lundi : Manteau neigeux printanier. Regel nocturne parfois correct en altitude. En journée reprise de l'humidification et de la fonte. Neige très humide, mais dense.

Aperçu météo pour le lundi 27 avril

nuit	matin	après-midi	soir

Regel nocturne parfois correct en altitude. Temps ensoleillé et doux, formation de cumulus l'après-midi. Rare averse isolée non exclue en fin de journée.

Pluie-Neige				
Iso 0 °C	3 200 m	3 200 m	3 200 m	3 000 m
Vent 1500 m	↙ 10 km/h	↙ 15 km/h	→ 15 km/h	↑ 5 km/h
Vent 2000 m	↓ 15 km/h	→ 20 km/h	→ 20 km/h	↗ 10 km/h

Épaisseur de neige hors-piste

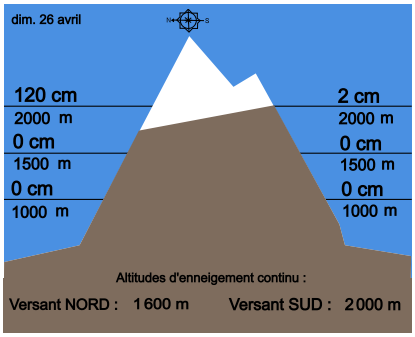

Précipitations à 1800 m

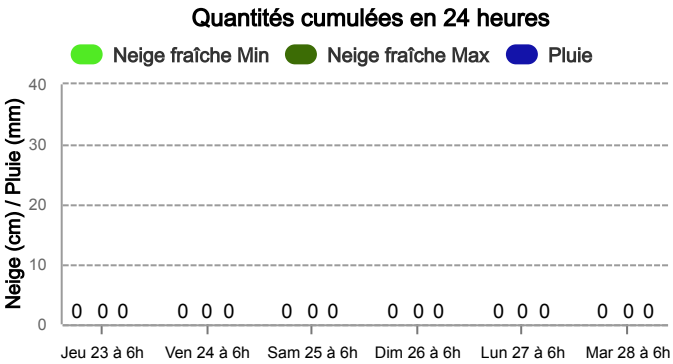

Tendance du mardi 28 avril

1

Indice de risque faible

Mardi, le risque devrait peu évoluer malgré un regel nocturne parfois absent sous un ciel devenant plus chargé. En journée, assez nuageux et chaotique avec des averses de pluie sur le massif, parfois accompagnées de coups de tonnerre.

Pour consulter la vigilance en cours, veuillez vous rendre sur le site https://vigilance.meteofrance.fr/fr

Météo-France - 73 avenue de Paris, 94165 Saint-Mandé cedex - Contact : contact@meteo.fr

Rédigé par Météo-France avec la contribution des observateurs du réseau nivo-météorologiques. Partenariat : ANMSM (Maires de Stations de Montagne), DSF (Domaines Skiables de France), ADSP (Directeurs de Pistes et de la Sécurité des Stations de Sports d'Hiver) et autres acteurs de la montagne.

Bulletin neige & avalanches par téléphone au

0 892 68 10 20 Service 0,35 € / min + prix appel

RÉPUBLIQUE FRANÇAISE
Liberté Égalité Fraternité

METEO FRANCE
À VOS CÔTÉS, DANS UN CLIMAT QUI CHANGE

Bulletin d'estimation du risque d'avalanche

(valable en dehors des pistes balisées et ouvertes)

MASSIF : Vercors

Rédigé le dimanche 26 avril 2026 à 16h

Conditions nivo-météo des 7 derniers jours

	lun. 20/04				mar. 21/04				mer. 22/04				jeu. 23/04				ven. 24/04				sam. 25/04				dim. 26/04			
	03h	09h	15h	21h	03h	09h	15h	21h	03h	09h	15h	21h	03h	09h	15h	21h	03h	09h	15h	21h	03h	09h	15h	21h	03h	09h	15h	21h
Météo																												
Vent (km/h)	20	20	25	15	15	20	20	10	15	20	25	15	20	20	20	10	15	20	20	10	15	25	30	25	25	30	25	15
à 2000m																												
Vent (km/h)	10	20	25	10	10	20	25	10	10	15	20	10	10	15	20	10	10	10	20	10	10	20	25	20	20	25	20	10
à 1500m																												

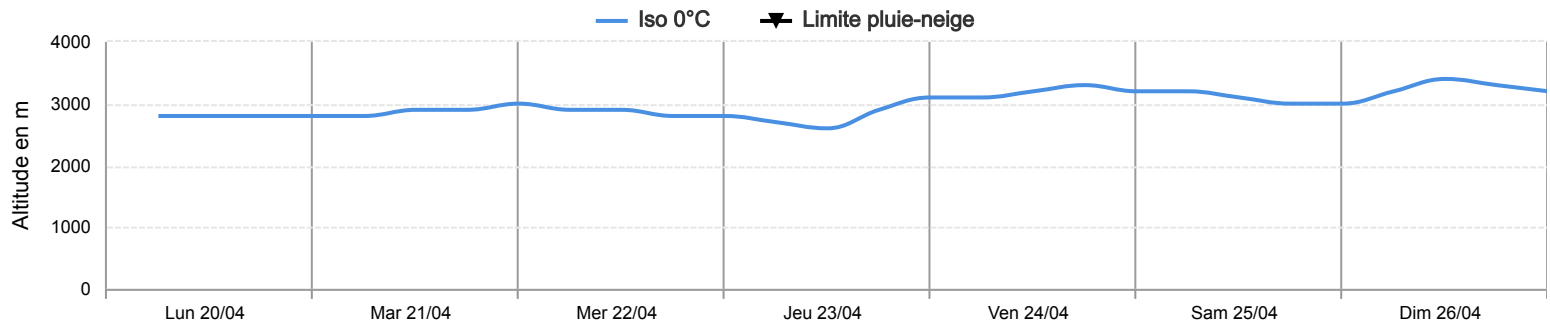

Neige fraîche à 06h

Lun 20/04	Mar 21/04	Mer 22/04	Jeu 23/04	Ven 24/04	Sam 25/04
0 cm	0 cm	0 cm	0 cm	0 cm	0 cm

Risque d'avalanche	lun. 20/04	mar. 21/04	mer. 22/04	jeu. 23/04	ven. 24/04	sam. 25/04	dim. 26/04
	2	2	1	1	1	1	1

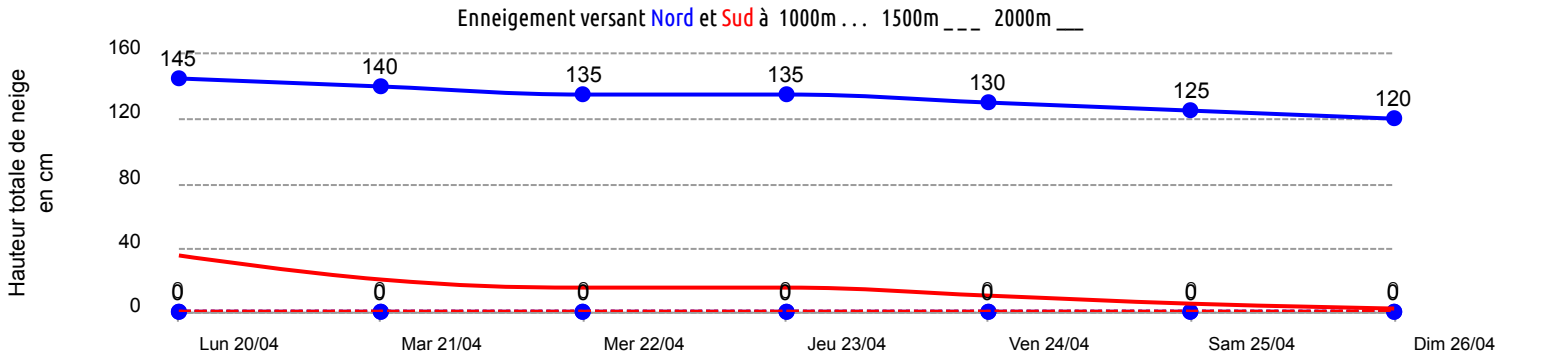

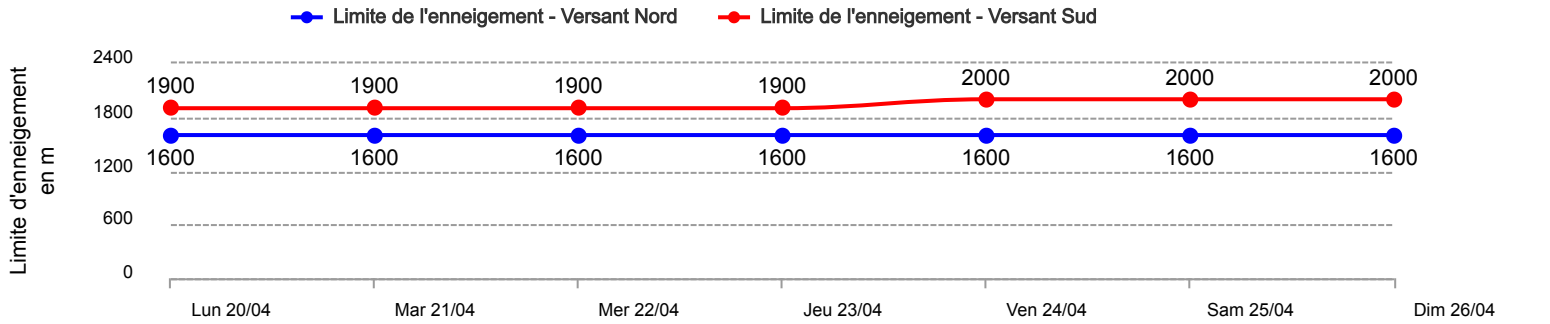

Pour consulter la vigilance en cours, veuillez vous rendre sur le site https://vigilance.meteofrance.fr/fr

Météo-France - 73 avenue de Paris, 94165 Saint-Mandé cedex - Contact : contact@meteo.fr

Rédigé par Météo-France avec la contribution des observateurs du réseau nivo-météorologiques. Partenariat : ANMSM (Maires de Stations de Montagne), DSF (Domaines Skiables de France), ADSP (Directeurs de Pistes et de la Sécurité des Stations de Sports d'Hiver) et autres acteurs de la montagne.

Bulletin neige & avalanches par téléphone au

0 892 68 10 20 Service 0,35 € / min + prix appel