Bulletin d'estimation du risque d'avalanche
(valable en dehors des pistes balisées et ouvertes)

MASSIF : Haute-Tarentaise

Rédigé le dimanche 26 avril 2026 à 17h

Estimation des risques pour le : LUNDI 27 AVRIL

L'HUMIDIFICATION EN PROFONDEUR CONTINUE.

2

1 → 2

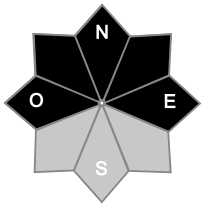

Indice de risque faible évoluant en limité.

Départs spontanés : rares mais possibles grands départs en neige humide.

Déclenchements provoqués : coulées humides sous les skis.

Indices de risque : 5 très fort - 4 fort - 3 marqué - 2 limité - 1 faible -- En noir : les pentes les plus dangereuses

Stabilité du manteau neigeux

Situation avalancheuse typique : neige humide

Départs spontanés : rares avalanches de neige humide dans les pentes ensoleillées. Elles se produisent après plusieurs heures d'action du soleil, départs majoritairement ponctuels (coulées en "poires"), petites avalanches. Les pentes sud sont davantage stabilisées en cette saison déjà bien avancée avec une neige dense de type névé sur toute l'épaisseur du manteau.
En versants Est et Ouest d'altitude, ainsi qu'en Nord, l'humidification gagne en profondeur. **Un rare départ linéaire est possible** quand l'humidification atteint une couche fragile enfouie, **une grande avalanche (taille 3)** devient possible.

Déclenchements provoqués : peu probables sauf avalanche de neige humide (pourrie) sous les skis en coupant une pente trop humidifiée.

Autres : chutes de corniches signalées, rares plaques de fond.

Qualité de la neige

Enneigement : déficitaire pour la saison, la chaleur est durablement excessive et la neige fond à vue d'œil. La très haute montagne est sèche à cause des épisodes de vent de l'hiver.

Limite skiable : vers 1600 m en nord, 2000/2200 m en sud en pente douce, bien plus haut en pente sud raide.

Qualité de la neige : neige de printemps après un bon regel nocturne. Neige dure aux premières heures du jour puis rapidement moquette de la matinée à la mi journée suivant orientations et altitudes. Neige pourrie rapidement le matin en versant Est et généralement partout après midi. Il faut monter au-dessus de 3000 m en plein Nord pour trouver un peu de neige froide localement en vieille poudre, souvent bétonnée par le vent.

Aperçu météo pour le lundi 27 avril

	nuit	matin	après-midi	soir
Journée ensoleillée et printanière.				
Pluie-Neige				
Iso 0 °C	3 200 m	3 300 m	3 300 m	3 100 m
Vent 2500 m	→ 10 km/h	→ 10 km/h	↘ 10 km/h	↘ 10 km/h
Vent 3500 m	→ 15 km/h	→ 20 km/h	→ 20 km/h	→ 20 km/h

Épaisseur de neige hors-piste

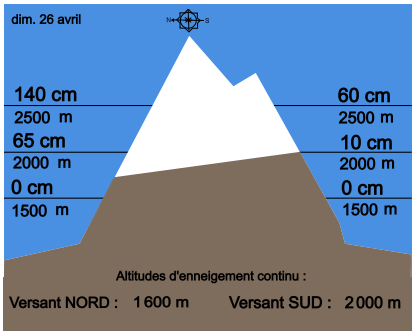

Précipitations à 1800 m

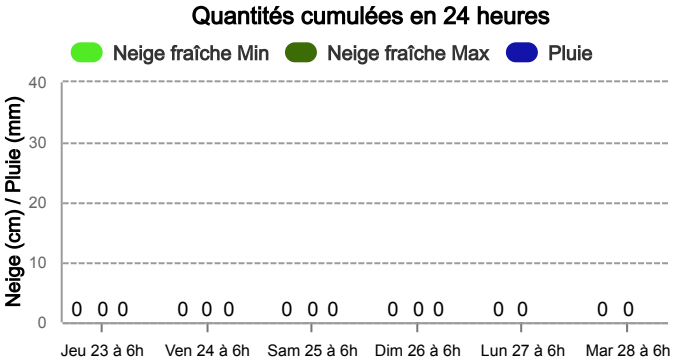

Tendance du mardi 28 avril

2

Indice de risque limité

Journée douce et nuageuse : mauvaises conditions en montagne et risque d'avalanche limité.

Pour consulter la vigilance en cours, veuillez vous rendre sur le site https://vigilance.meteofrance.fr/fr

Météo-France - 73 avenue de Paris, 94165 Saint-Mandé cedex - Contact : contact@meteo.fr

Rédigé par Météo-France avec la contribution des observateurs du réseau nivo-météorologiques. Partenariat : ANMSM (Maires de Stations de Montagne), DSF (Domaines Skiables de France), ADSP (Directeurs de Pistes et de la Sécurité des Stations de Sports d'Hiver) et autres acteurs de la montagne.

Bulletin neige & avalanches par téléphone au 0 892 68 10 20 Service 0,35 € / min + prix appel

RÉPUBLIQUE FRANÇAISE
Liberté Égalité Fraternité

METEO FRANCE
À VOS CÔTÉS, DANS UN CLIMAT QUI CHANGE

Bulletin d'estimation du risque d'avalanche

(valable en dehors des pistes balisées et ouvertes)

MASSIF : Haute-Tarentaise

Rédigé le dimanche 26 avril 2026 à 17h

Conditions nivo-météo des 7 derniers jours

	lun. 20/04				mar. 21/04				mer. 22/04				jeu. 23/04				ven. 24/04				sam. 25/04				dim. 26/04			
	03h	09h	15h	21h	03h	09h	15h	21h	03h	09h	15h	21h	03h	09h	15h	21h	03h	09h	15h	21h	03h	09h	15h	21h	03h	09h	15h	21h
Météo																												
Vent (km/h)	40	40	35	40	40	30	25	40	40	35	20	10	10	20	15	15	10	10	20	10	10	20	20	10	10	10	10	10
à 3500m	→	→	→	→	→	→	→	→	→	→	→	↙	↙	←	↙	↙	←	↓	↘	↘	↗	→	↓	↑	↑	↓	↗	→
Vent (km/h)	15	20	20	15	15	15	15	15	15	20	15	5	10	15	10	5	5	5	15	5	5	15	15	5	5	5	5	5
à 2500m	→	→	→	→	→	→	→	→	→	→	→	←	↙	←	↙	←	↓	↑	↘	↘	→	↘	→	↓	↑	↓	↗	↑

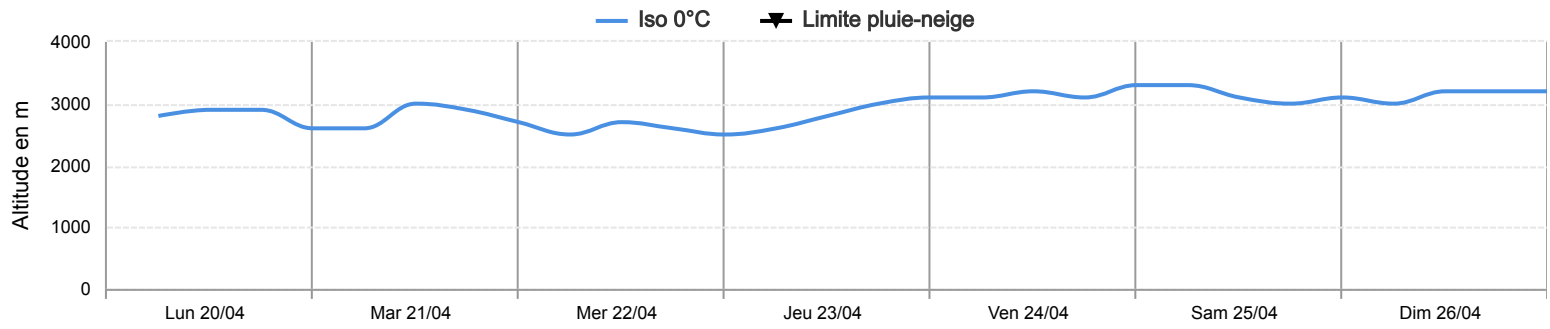

Neige fraîche à 06h

0 cm	0 cm	0 cm	0 cm	0 cm	0 cm

Risque d'avalanche	lun. 20/04	mar. 21/04	mer. 22/04	jeu. 23/04	ven. 24/04	sam. 25/04	dim. 26/04
	2	2	2	2	2	2	2

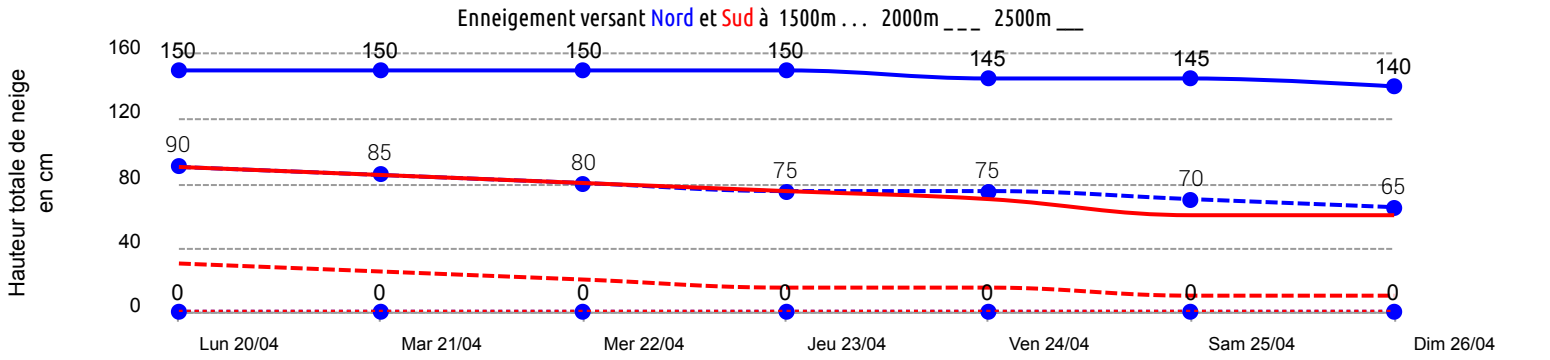

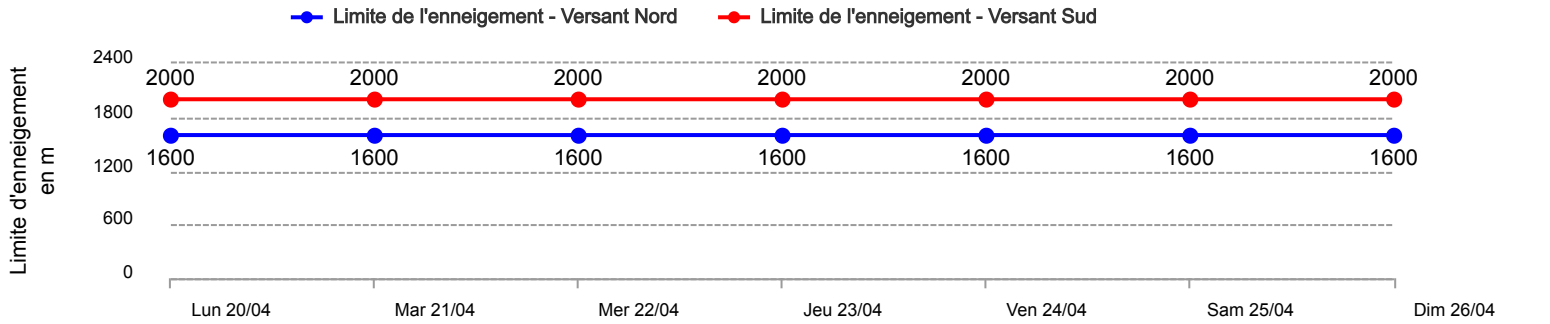

Pour consulter la vigilance en cours, veuillez vous rendre sur le site https://vigilance.meteofrance.fr/fr

Météo-France - 73 avenue de Paris, 94165 Saint-Mandé cedex - Contact : contact@meteo.fr

Rédigé par Météo-France avec la contribution des observateurs du réseau nivo-météorologiques. Partenariat : ANMSM (Maires de Stations de Montagne), DSF (Domaines Skiables de France), ADSP (Directeurs de Pistes et de la Sécurité des Stations de Sports d'Hiver) et autres acteurs de la montagne.

Bulletin neige & avalanches par téléphone au

0 892 68 10 20 Service 0,35 € / min + prix appel