Dienstag 28.04.2026

Veröffentlicht am 27.04.2026 um 17:00

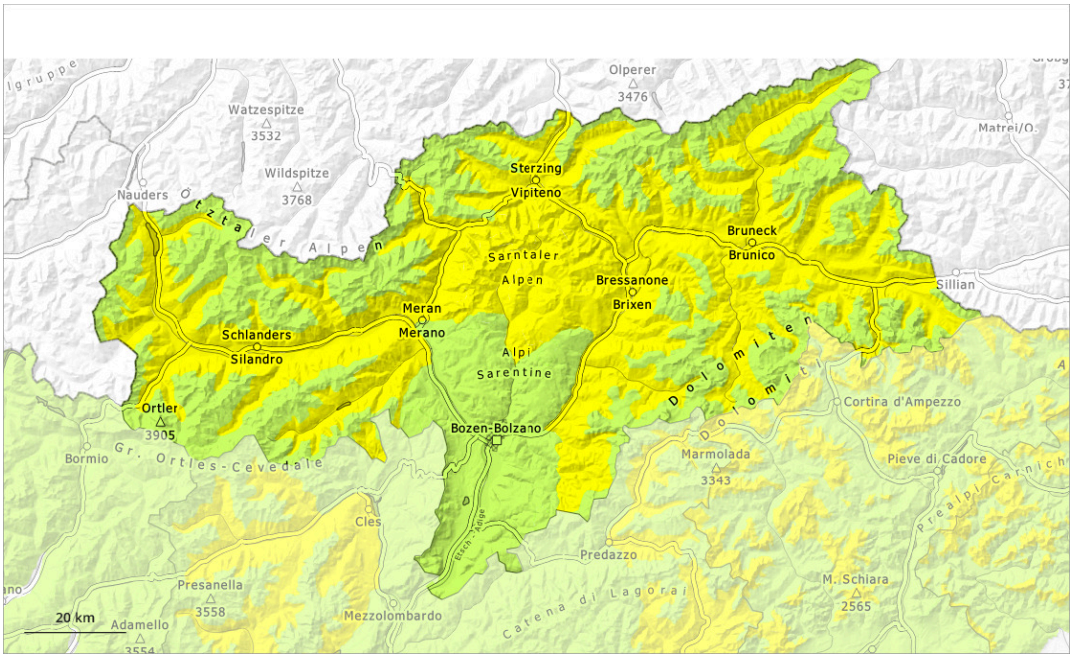

1	2	3	4	5
gering	mäßig	erheblich	groß	sehr groß

Gefahrenstufe 2 - Mäßig

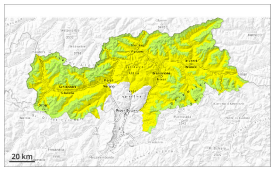

2600m

Tendenz: Lawinengefahr bleibt gleich
am Mittwoch, den 29.04.2026

Nassschnee

2600m

Vorsicht vor Nassschnee.

Nasse Lawinen können vereinzelt von einzelnen Wintersportlern ausgelöst werden. Dies besonders unterhalb von rund 2600 m.

Mit Neuschnee und mäßigem Wind entstehen vor allem im Hochgebirge gut sichtbare Triebschneeansammlungen. Diese sind klein und nur vereinzelt auslösbar.

Schwachschichten im Altschnee können vor allem an sehr steilen Schattenhängen vereinzelt und meist mit großer Zusatzbelastung ausgelöst werden, vor allem oberhalb von rund 2500 m.

Schneedecke

Gefahrenmuster gm.3: regen auf schnee | gm.1: bodennahe schwachschicht

Die nächtliche Abstrahlung ist zeitweise stark eingeschränkt. Die Schneeoberfläche gefriert kaum und weicht rasch auf. Am Nachmittag fällt gebietsweise etwas Regen.

Schattenhänge oberhalb von rund 2500 m: Im unteren Teil der Altschneedecke sind in der Höhe kantig aufgebaute Schwachschichten vorhanden.

An steilen Sonnenhängen sowie unterhalb von rund 1800 m liegt kaum Schnee.

Tendenz

Es fällt gebietsweise Regen bis auf 2600 m. Die Gefahr von nassen Lawinen besteht schon am Morgen.

Gefahrenstufe 1 - Gering

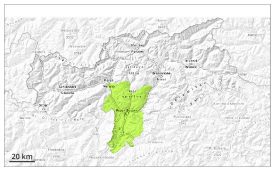

1

Tendenz: Lawinengefahr bleibt gleich
am Mittwoch, den 29.04.2026

Nassschnee beachten.

Es sind nur noch vereinzelt nasse Lawinen möglich. Vorsicht an extrem steilen Schattenhängen. Lawinen sind meist eher klein.

Schneedecke

Gefahrenmuster gm.3: regen auf schnee | gm.10: frühjahrssituation

Die nächtliche Abstrahlung ist stark eingeschränkt. Die Schneeoberfläche gefriert kaum und weicht rasch auf. Am Nachmittag fällt etwas Regen.

Tendenz

Geringe Lawinengefahr. Nassschnee beachten.