Dienstag 28.04.2026

Veröffentlicht am 27.04.2026 um 17:00

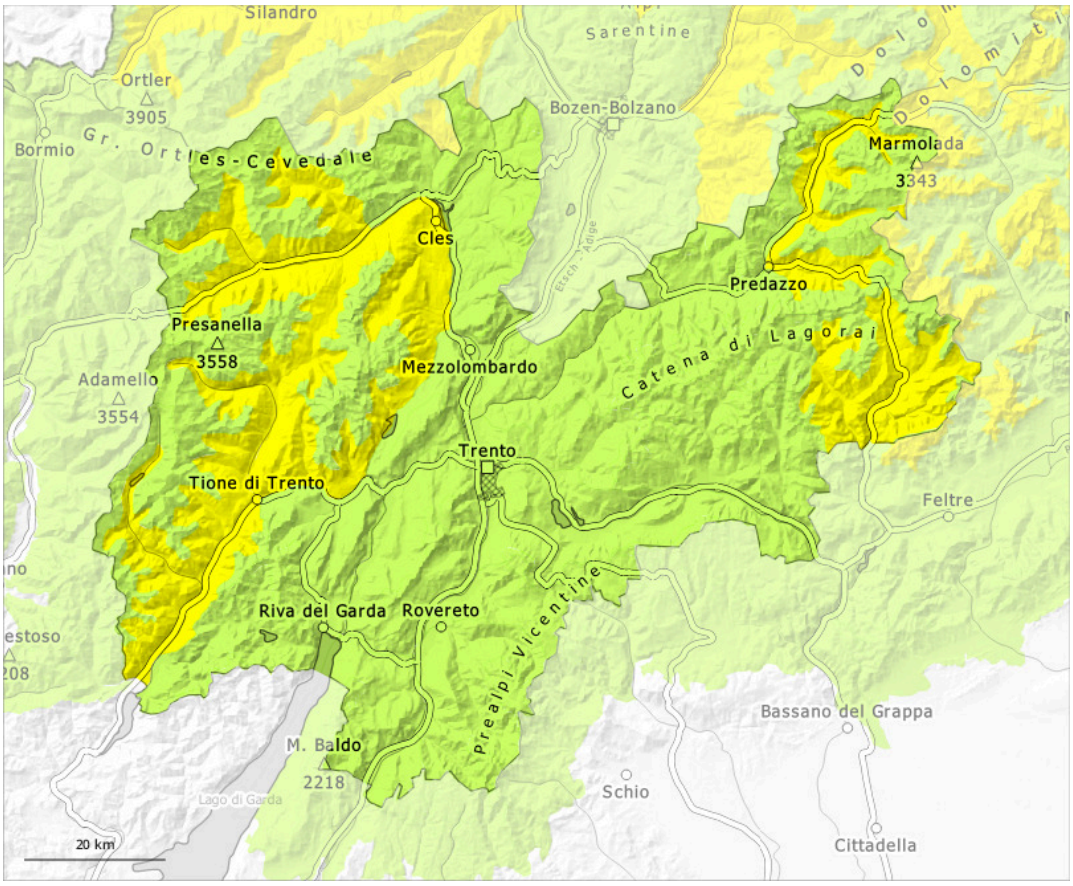

1	2	3	4	5
gering	mäßig	erheblich	groß	sehr groß

Gefahrenstufe 2 - Mäßig

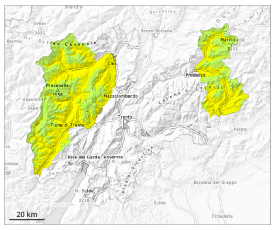

2800m

Tendenz: Lawinengefahr bleibt gleich
am Mittwoch, den 29.04.2026

Nassschnee

2800m

Altschnee

2500m

Anstieg der Gefahr von nassen Lawinen im Tagesverlauf.

Mit Neuschnee und Wind entstehen vor allem im Hochgebirge Triebschneeansammlungen. Die feuchten Lawinen können an sehr steilen Hängen spontan abgehen und vereinzelt mittlere Größe erreichen. Mit der Erwärmung steigt die Lawinengefahr an.
Einzelne Gefahrenstellen liegen an sehr steilen Schattenhängen oberhalb von rund 2500 m. Lawinen können mit meist großer Belastung ausgelöst werden und mittlere Größe erreichen. Diese können sehr vereinzelt bis auf den Boden durchreißen und groß werden.

Schneedecke

Gefahrenmuster gm.10: frühjahrssituation | gm.1: bodennahe schwachschicht

Die Schneeoberfläche gefriert nur knapp und weicht rasch auf. Es fallen gebietsweise oberhalb von rund 2400 m 5 bis 15 cm Schnee. Die frühlingshaften Wetterbedingungen führen unterhalb von rund 2800 m zu einer raschen Anfeuchtung der Schneedecke.
Steile West-, Nord- und Osthänge oberhalb von rund 2500 m: Im unteren Teil der Altschneedecke sind kantig aufgebaute Schwachschichten vorhanden.

Tendenz

Tagesverlauf: Die Lawinengefahr steigt innerhalb der Gefahrenstufe an.

Gefahrenstufe 1 - Gering

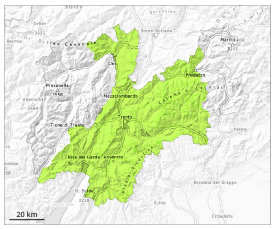

Tendenz: Lawinengefahr bleibt gleich
am Mittwoch, den 29.04.2026

Nassschnee

Geringe Lawinengefahr.

Aus noch nicht entladenen Einzugsgebieten sind nur noch vereinzelt nasse Lawinen möglich. Vorsicht an extrem steilen Schattenhängen. Lawinen sind meist eher klein.

Schneedecke

Gefahrenmuster gm.10: frühjahrssituation

Es fällt gebietsweise wenig Schnee. Die nächtliche Abstrahlung ist verbreitet reduziert. Die Schneeoberfläche ist nur in hohen Lagen tragfähig gefroren und weicht rasch auf.

Tendenz

Geringe Lawinengefahr.