ICGC Institut Cartogràfic i Geològic de Catalunya

Servei Meteorològic de Catalunya meteo.cat

Boletín de peligro de aludes para el Pirineo de Catalunya
Del 27/04/2026 al 28/04/2026

(Válido fuera pistas de esquí y zonas no controladas)

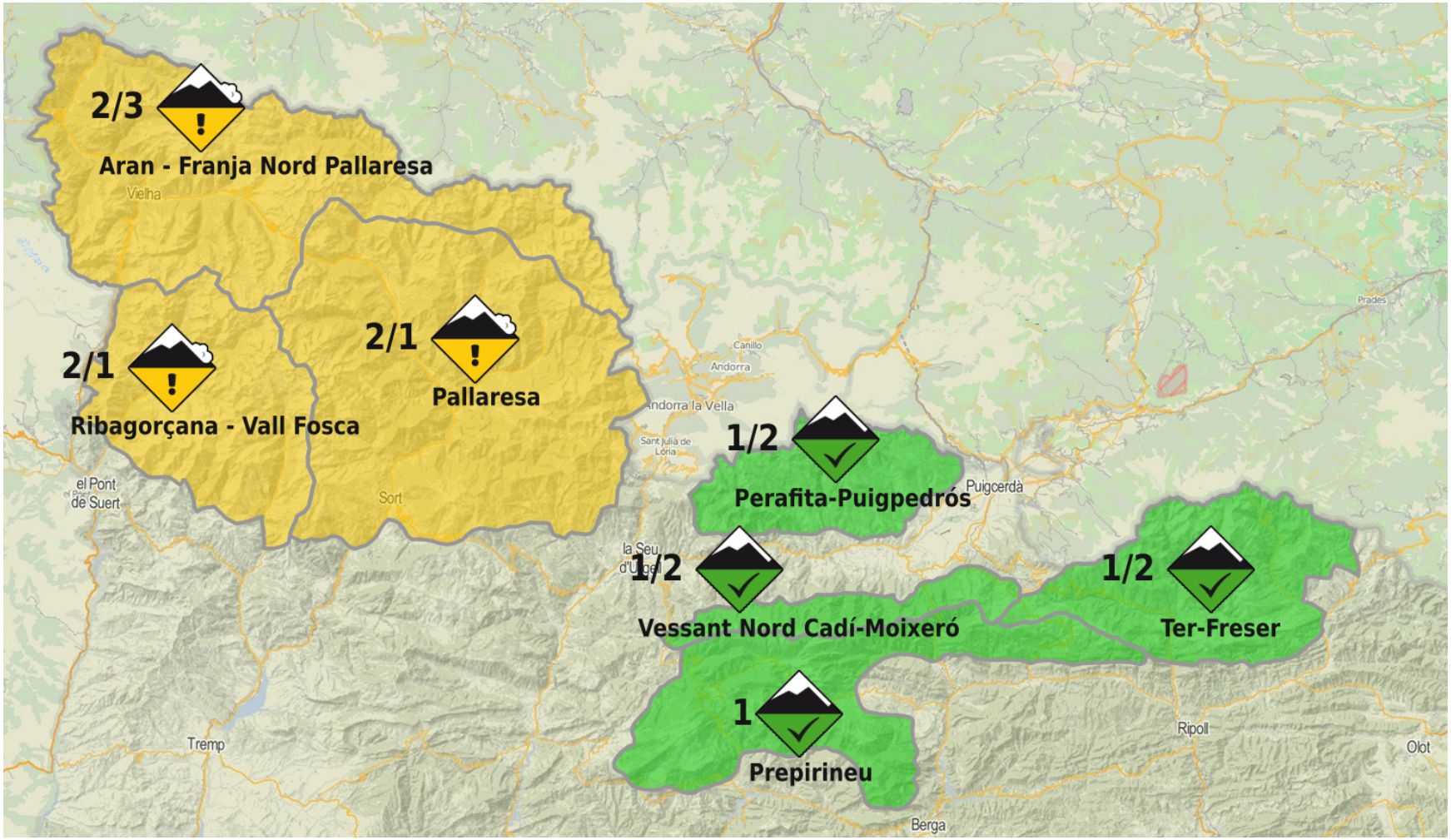

5 MUY FUERTE	4 FUERTE	3 NOTABLE	2 LIMITADO	1 DÉBIL

ICGC Institut Cartogràfic i Geològic de Catalunya

Servei Meteorològic de Catalunya

Boletín de peligro de aludes Aran - Franja Nord Pallaresa Del 27/04/2026 al 28/04/2026

(Válido fuera pistas de esquí y zonas no controladas)

LIMITADO (2), NOTABLE (3), en momentos de chubascos, por la tarde.

Situación primaria

Deslizamientos basales **Distribución** **Tamaño** **Origen** **Tendencia**

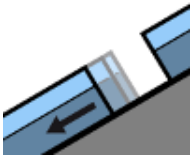

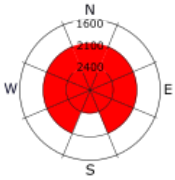

Situación secundaria

Nieve húmeda **Distribución** **Tamaño** **Origen** **Tendencia**

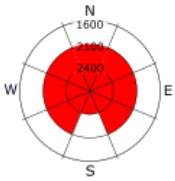

Estado del manto nivoso

El manto ha ido reculando a causa de los chubascos diarios de tarde y se muestra húmedo hasta su base. El rehielo es prácticamente inexistente y la nieve más dura de la madrugada se transforma rápidamente el transcurso de la mañana. Para el martes seguiremos con la dinámica de una mañana estable y tormentas de tarde. A partir de los 2.000 m todavía se esperan deslizamientos basales de hasta tamaño 2 (mediano), suficiente para enterrar a una persona. Localmente, no se descarta que puedan alcanzar también el tamaño grande. Además, son muy probables las caídas naturales de aludes de fusión a partir de media mañana y en momentos de chubascos, cuando la penetración de la humedad es mayor. Estos aludes también serán, en general, de tamaño 2 (mediano). Hay que prestar atención a la aparición de grietas de deslizamientos y evitar los momentos de lluvia, que es cuando puede aumentar la actividad. Se recomienda empezar temprano las excursiones de montaña y finalizarlas a media mañana.

Distribución del manto nivoso

Hay nieve en el suelo con continuidad y esquiable por encima de los 2.000 m en umbrías y es más discontinua en solanas, a partir de 2.200 m. Los espesores a unos 2.300 m rondan los 100-140 cm, con sobreacumulaciones que todavía se acercan a los 200 cm. Los valores se acercan a los normales para la época.

Tendencia para las próximas 48-72h

Se mantendrá la situación de chubascos de tarde con aludes de fusión a partir de media mañana y en momentos de lluvia. Evolución del peligro: ESTACIONARIO.

El próximo boletín será emitido el día 2026-04-28

5 MUY FUERTE	4 FUERTE	3 NOTABLE	2 LIMITADO	1 DÉBIL

EAWS EUROPEAN AVALANCHE WARNING SERVICES

ICGC Institut Cartogràfic i Geològic de Catalunya

meteo.cat Servei Meteorològic de Catalunya

Boletín de peligro de aludes Ribagorçana - Vall Fosca Del 27/04/2026 al 28/04/2026

(Válido fuera pistas de esquí y zonas no controladas)

LIMITADO (2), a partir de media mañana y con chubascos.
DÉBIL (1), de madrugada y a primera hora.

Situación primaria

Nieve húmeda

Distribución

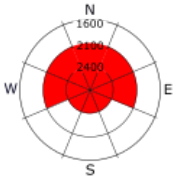

Tamaño

Origen

Tendencia

Situación secundaria

Deslizamientos basales

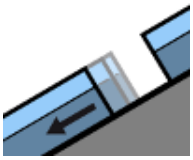

Distribución

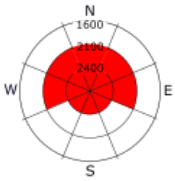

Tamaño

Origen

Tendencia

Estado del manto nivoso

El manto se encuentra humedecido hasta su base y ha ido reculando a causa de los chubascos de tarde y de la intensa radiación. El rehielo superficial es prácticamente inexistente y la nieve más dura de la madrugada se transforma rápidamente con el transcurso de la mañana. El martes el manto continuará húmedo y podrán caer aludes de fusión y algún deslizamiento basal, más local. Los aludes que puedan caer pueden llegar hasta tamaño 2 (mediano), con capacidad de enterrar a un montañero. Las vertientes más proclives son los terrenos herbosos de fuerte inclinación. Las orientaciones afectadas por deslizamientos y por aludes de fusión, en umbrías, son todas por encima de 2.100-2.200 m, y en las solanas, por encima de 2.400 m. Los tamaños de los aludes de mayor alcance serán en el extremo norte de este sector y por encima de los 2.300 m, donde encontramos un grosor mayor. Se recomienda empezar temprano las excursiones de montaña y finalizarlas a media mañana.

Distribución del manto nivoso

Hay nieve por encima de 2.000 m pero esquiable en N por encima de 2.100 m y de los 2.400 m en S, de forma discontinua. Se alcanzan los 70-90 cm a unos 2.300 m, en umbrías. Estos valores están por debajo de los normales para la época.

Tendencia para las próximas 48-72h

Se mantendrá la situación de chubascos de tarde con aludes húmedos a partir de media mañana y en momentos de lluvia. Evolución del peligro: ESTACIONARIO.

El próximo boletín será emitido el día 2026-04-28

5 MUY FUERTE	4 FUERTE	3 NOTABLE	2 LIMITADO	1 DÉBIL

EAWS EUROPEAN AVALANCHE WARNING SERVICES

ICGC Institut Cartogràfic i Geològic de Catalunya

Servei Meteorològic de Catalunya meteo.cat

Boletín de peligro de aludes Pallaresa
Del 27/04/2026 al 28/04/2026

(Válido fuera pistas de esquí y zonas no controladas)

LIMITADO (2), a partir de media mañana y con chubascos.
DÉBIL (1), de madrugada y a primera hora.

Situación primaria

Nieve húmeda

Distribución

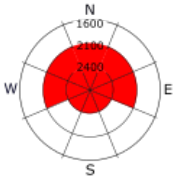

Tamaño

Origen

Tendencia

Situación secundaria

Deslizamientos basales

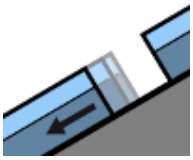

Distribución

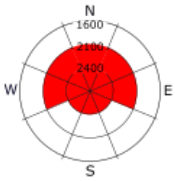

Tamaño

Origen

Tendencia

Estado del manto nivoso

El manto se encuentra humedecido hasta su base y ha ido reculando a causa de los chubascos de tarde y de la intensa radiación. El rehielo superficial es prácticamente inexistente y la nieve más dura de la madrugada se transforma rápidamente con el transcurso de la mañana. El martes el manto continuará húmedo y podrán caer aludes de fusión y algún deslizamiento basal, más local. Los aludes que puedan caer pueden llegar hasta tamaño 2 (mediano), con capacidad de enterrar a un montañero. Las vertientes más proclives son los terrenos herbosos de fuerte inclinación. Las orientaciones afectadas por deslizamientos y por aludes de fusión, en umbrías, son todas por encima de 2.100-2.200 m, y en las solanas, por encima de 2.400 m. Los tamaños de los aludes de mayor alcance serán en el extremo norte de este sector y por encima de los 2.300 m, donde encontramos un grosor mayor. Se recomienda empezar temprano las excursiones de montaña y finalizarlas a media mañana.

Distribución del manto nivoso

Hay nieve por encima de 2.000 m en Norte y es esquiable por encima de 2.100-2.200 m. En orientación Sur el manto es discontinuo. Se alcanzan los 70-90 cm a unos 2.200 m, con frecuentes deflaciones y acumulaciones por encima del nivel del bosque.

Tendencia para las próximas 48-72h

Se mantendrá la situación de chubascos de tarde con aludes húmedos a partir de media mañana y en momentos de lluvia. Evolución del peligro: ESTACIONARIO.

El próximo boletín será emitido el día 2026-04-28

5 MUY FUERTE	4 FUERTE	3 NOTABLE	2 LIMITADO	1 DÉBIL

EAWS EUROPEAN AVALANCHE WARNING SERVICES

ICGC Institut Cartogràfic i Geològic de Catalunya

Servei Meteorològic de Catalunya

Boletín de peligro de aludes Perafita-Puigpedrós Del 27/04/2026 al 28/04/2026

(Válido fuera pistas de esquí y zonas no controladas)

DÉBIL (1), LIMITADO (2), a partir de mediodía y con chubascos.

Situación primaria

Nieve húmeda

Distribución

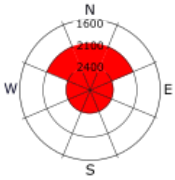

Tamaño

Origen

Tendencia

Situación secundaria

Deslizamientos basales

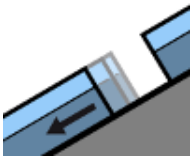

Distribución

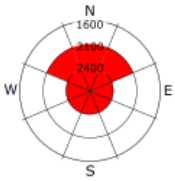

Tamaño

Origen

Tendencia

Estado del manto nivoso

Los chubascos de tarde, la intensa radiación y las temperaturas positivas mantendrán el manto húmedo y favorecerán su fusión. A primera hora del día aparece un leve rehielo a umbrías que desaparece rápidamente con el transcurso de la mañana. Para el martes, los problemas continuarán relacionados con los aludes de nieve húmeda y por algún deslizamiento basal, de forma más local. Los aludes que puedan caer pueden llegar hasta tamaño 2 (mediano), con capacidad de enterrar a un montañero. Las vertientes más proclives son los terrenos herbosos de fuerte inclinación. Las orientaciones afectadas por deslizamientos y por aludes de fusión son todas por encima de 2.100-2.200 m en umbrías y por encima de 2.400 m en las solanas. Los tamaños de los aludes de mayor alcance serán en el extremo norte de este sector y por encima de los 2.200 m, donde encontramos un grosor mayor. Se recomienda empezar temprano las excursiones de montaña y finalizarlas a media mañana.

Distribución del manto nivoso

Hay nieve esquiable en umbrías por encima de 2.100 m en orientaciones N y de 2.300 m en Sur, de forma discontinua. El grosor total en el suelo a umbrías oscila entre los 30 y los 70 cm a unos 2.300 m. Estos valores están por debajo de los normales por la época.

Tendencia para las próximas 48-72h

Se mantendrá la situación de chubascos de tarde con aludes húmedos a partir de media mañana y en momentos de lluvia. Evolución del peligro: ESTACIONARIO.

El próximo boletín será emitido el día 2026-04-28

5 MUY FUERTE	4 FUERTE	3 NOTABLE	2 LIMITADO	1 DÉBIL

EAWS EUROPEAN AVALANCHE WARNING SERVICES

ICGC Institut Cartogràfic i Geològic de Catalunya

Servei Meteorològic de Catalunya meteo.cat

Boletín de peligro de aludes
Vessant Nord Cadí-Moixeró
Del 27/04/2026 al 28/04/2026

(Válido fuera pistas de esquí y zonas no controladas)

DÉBIL (1), LIMITADO (2), a partir de mediodía y con chubascos.

Situación primaria

Nieve húmeda

Distribución

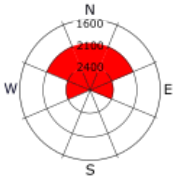

Tamaño

Origen

Tendencia

Estado del manto nivoso

El manto se muestra húmedo hasta su base y las costras internas aparecen muy degradadas. A primera hora del día aparece un leve rehielo a umbrías elevadas que desaparece rápidamente con el transcurso de la mañana. Para el martes el manto continuará humedeciéndose y con estas condiciones se esperan caídas naturales de aludes de fusión, sobre todo en momentos de chubascos, en cualquier orientación y alcanzarán mayor alcance por encima de los 2.200 m, donde hay mayor grosor de manto movilizable. En caso de que se desencadenen pueden alcanzar tamaño 2 (mediano), suficiente para enterrar a un montañero. Los sectores más peligrosos son las canales, donde todavía se acumula cerca de un metro de nieve. Habrá que evitar los momentos de chubascos y las horas de mayor humedecimiento. Se recomienda empezar las actividades de montaña temprano y finalizarlas a media mañana.

Distribución del manto nivoso

Hay nieve por encima de 2.000 m en N y de 2.200 mm en Sur, de forma muy escasa y discontinua. Se alcanzan los 90-110 cm a unos 2.300 m, en umbrías. Estos valores están por encima de los normales para la época.

Tendencia para las próximas 48-72h

Se mantendrá la situación de aludes de fusión a partir de media mañana y en momentos de lluvia. Evolución del peligro: ESTACIONARIO.

El próximo boletín será emitido el día 2026-04-28

5 MUY FUERTE	4 FUERTE	3 NOTABLE	2 LIMITADO	1 DÉBIL

EAWS EUROPEAN AVALANCHE WARNING SERVICES

ICGC Institut Cartogràfic i Geològic de Catalunya

Servei Meteorològic de Catalunya meteo.cat

Boletín de peligro de aludes Prepirineu
Del 27/04/2026 al 28/04/2026

(Válido fuera pistas de esquí y zonas no controladas)

DÉBIL (1).

Situación primaria

Nieve húmeda

Distribución

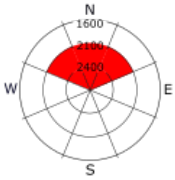

Tamaño

Origen

Tendencia

Estado del manto nivoso

El manto va retrocediendo progresivamente debido a los chubascos de tarde, la intensa radiación y por las temperaturas positivas. De madrugada y a primera hora del día aparece un leve rehielo a umbrías que desaparece rápidamente en el transcurso de la mañana. Por lo general, el manto se presenta húmedo en su totalidad. Para el martes los chubascos de tarde se repetirán y, por tanto, se esperan caídas naturales de aludes de fusión, sobre todo a partir de media mañana o en momentos de lluvia, en umbrías, donde hay más grosor de manto movilizable. Los aludes llegarán a tamaño 1 (pequeño), sin capacidad para enterrar a un montañero. Los sectores más peligrosos es el terreno trampa, como las depresiones, donde los grosores acumulados en caso de alud pueden ser mayores. Habrá que evitar los momentos de chubascos y las horas de mayor humedecimiento. Se recomienda empezar temprano las excursiones de montaña y finalizarlas a media mañana.

Distribución del manto nivoso

Hay nieve más continua, en umbrías, a partir de 2.100-2.200 m. En orientación Sur es discontinua y muy escasa hasta las cumbres. Encontramos alrededor de 40-50 cm de nieve en el suelo a unos 2.300 m, en umbrías.

Tendencia para las próximas 48-72h

Se mantendrá la situación de fusión-rehielo con aludes de fusión a partir de media mañana y en momentos de chubascos. Evolución del peligro: ESTACIONARIO.

El próximo boletín será emitido el día 2026-04-28

5 MUY FUERTE	4 FUERTE	3 NOTABLE	2 LIMITADO	1 DÉBIL

EAWS EUROPEAN AVALANCHE WARNING SERVICES

ICGC Institut Cartogràfic i Geològic de Catalunya

Servei Meteorològic de Catalunya

Boletín de peligro de aludes Ter-Freser Del 27/04/2026 al 28/04/2026

(Válido fuera pistas de esquí y zonas no controladas)

DÉBIL (1), LIMITADO (2), a partir de mediodía y con chubascos.

Situación primaria

Deslizamientos basales

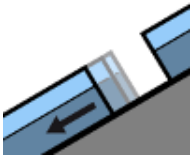

Distribución

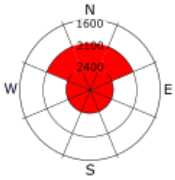

Tamaño

Origen

Tendencia

Situación secundaria

Nieve húmeda

Distribución

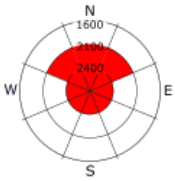

Tamaño

Origen

Tendencia

Estado del manto nivoso

Los chubascos de tarde, la intensa radiación y las temperaturas positivas mantendrán el manto húmedo y favorecerán su fundición. A primera hora del día aparece un leve rehielo en umbrías que desaparece rápidamente en el transcurso de la mañana. Para el martes, los problemas continuarán relacionados con los aludes de nieve húmeda y por algún deslizamiento basal, de forma más local. Los aludes que puedan caer pueden llegar hasta tamaño 2 (mediano), con capacidad de enterrar a un montañero. Las vertientes más proclives son los terrenos herbosos de fuerte inclinación. Las orientaciones afectadas por deslizamientos y por aludes de fusión son todas por encima de 2.100-2.200 m en umbrías y por encima de 2.400 m en las solanas. Los tamaños de los aludes de mayor alcance serán en el extremo norte de este sector y por encima de los 2.200 m, donde encontramos un grosor mayor. Se recomienda empezar temprano las excursiones de montaña y finalizarlas a media mañana.

Distribución del manto nivoso

Hay nieve por encima de 2,000 m en N y de 2.200 m en S. Los espesores rondan los 100 cm a unos 2.500 m. Estos valores están por encima de la media en umbrías de cota alta.

Tendencia para las próximas 48-72h

Se mantendrá la situación de chubascos de tarde con aludes húmedos a partir de media mañana y en momentos de lluvia. Evolución del peligro: ESTACIONARIO.

El próximo boletín será emitido el día 2026-04-28

5 MUY FUERTE	4 FUERTE	3 NOTABLE	2 LIMITADO	1 DÉBIL

EAWS EUROPEAN AVALANCHE WARNING SERVICES